GOBIERNO DE ESPAÑA
VICEPRESIDENCIA TERCERA DEL GOBIERNO
MINISTERIO PARA LA TRANSICIÓN ECOLÓGICA Y EL RETO DEMOGRÁFICO

Boletín de información nivológica y de peligro de aludes

Pirineo Catalán

aemet Agencia Estatal de Meteorología

domingo, 1 de febrero de 2026

Pronóstico hasta las 24 horas del lunes, día 2 de febrero

(Válido fuera de pistas de esquí balizadas y abiertas)

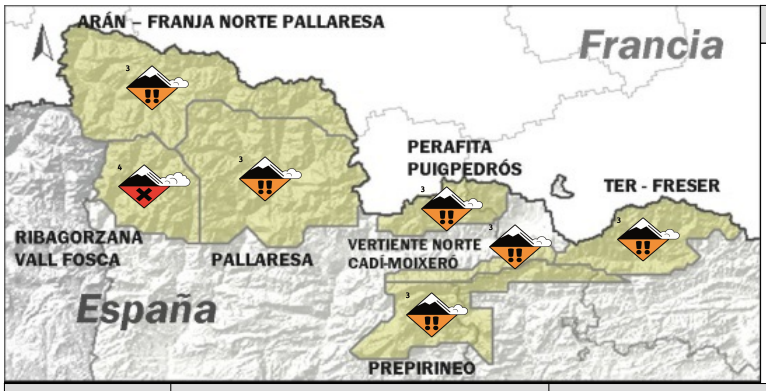

Problemas de aludes

Placas de viento

Nieve húmeda

Macizo	Peligro	Problemas de aludes, cota, orientación, tamaño	Innivación observada (m)
Arán - Franja norte Pallaresa	3 Notable	Placas de viento: 2100, N O E S, 2 Nieve húmeda: 2000, N O E S, 2	2026-02-01 N S Cotas bajas
Ribagorzana - Vall Fosca	4 Fuerte (3→4 2100, 3 Durante el día)	Placas de viento: 2100, N O E S, 3 Nieve húmeda: 2000, N O E S, 2	2026-02-01 N S Cotas bajas
Pallaresa	3 Notable	Placas de viento: 2100, N O E S, 2 Nieve húmeda: 2000, N O E S, 2	2026-02-01 N S Cotas bajas

AEMET. Se autoriza la reproducción de su contenido citando la fuente.

Boletín de información nivológica y de peligro de aludes

Pirineo Catalán

Perafita - Puigpedrós	3 **Notable**	**Placas de viento**  **Nieve húmeda** 	2026-02-01 Cotas bajas
Ter - Freser	3 **Notable**	**Placas de viento**  **Nieve húmeda** 	2026-02-01 Cotas bajas
Vertiente norte Cadí - Moixeró	3 **Notable**	**Placas de viento** 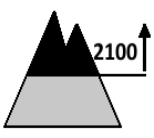  **Nieve húmeda** 	2026-02-01 Cotas bajas
Prepirineo	3 **Notable**	**Placas de viento** 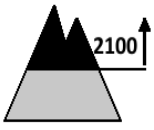  **Nieve húmeda** 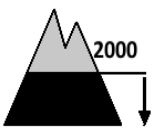 	2026-02-01 Cotas bajas

Estado del manto y observaciones recientes

Continua la situación de inestabilidad con las bajas presiones y el chorro polar instalados en nuestras latitudes. Las acumulaciones de nieve se van sucediendo en la cordillera prácticamente a diario, aunque con cantidades muy variables, y están siendo acompañadas de intensos vientos.

AEMET. Se autoriza la reproducción de su contenido citando la fuente.

Durante el día de ayer, se produjeron precipitaciones significativas en el Arán y Franja Norte Pallaresa, con observaciones de 15-25mm, mientras que en el resto de macizos no se superaron los 10mm, salvo localmente en algunos puntos de la Pallaresa y de la divisoria oriental. La cota de nieve se mantuvo por debajo de unos 1600 metros y los vientos han dado lugar a una repartición muy desigual de la nieve nueva. Hoy será un día de transición donde la radiación solar provocará una cierta humidificación en las solanas.

La cubierta de nieve comienza en cotas bajas y los espesores de gran parte de la red de observación están en máximos para la época. Estos se sitúan en torno a 120-150 cm por encima de 2100 metros, valores que pueden ser muy superiores conforme ganamos altitud, así como en ventisqueros u otras áreas de acumulación.

En cotas altas, la nieve presenta muy grandes acumulaciones, manteniéndose seca y muy venteada en superficie, al tiempo que, en umbrías, se observan estratos débiles internos así como una antigua capa débil persistente en la base del manto. En cotas inferiores, la nieve está más humedecida y estable, presentando generalmente una estructura superficial de nieve reciente sobre costra de rehielo.

Evolución del manto y peligro de aludes para el lunes, día 2

Problemas de placas de viento y capas débiles persistentes en cotas altas. Problemas de nieve reciente y nieve húmeda.

El mayor peligro se situará en cotas altas:
Allí, se formarán nuevas placas de viento, en orientaciones norte y este, que se sumarán a las ya existentes y que aún permanecen frágiles. De este modo, las podremos encontrar en todas las orientaciones y, con frecuencia, alejadas de crestas y collados. Estas se podrán desencadenar con facilidad y dar lugar a aludes de tamaño mediano o grande.
En las umbrías, no se descarta que las capas débiles persistentes antiguas sean susceptibles de colapsar en zonas de manto delgado, incluso ante sobrecargas débiles, dando lugar a aludes potencialmente grandes.
En laderas con la suficiente inclinación, es de esperar actividad de purgas de nieve reciente, de tamaño pequeño o mediano.

En cotas medias y bajas, las precipitaciones en forma de lluvia favorecerán los problemas de nieve húmeda, si bien la cota de nieve bajará notablemente por la tarde con la llegada de un frente frío. Las purgas y aludes asociados serán abundantes y podrán alcanzar el tamaño mediano, sin descartar localmente el grande. Los deslizamientos basales también serán posibles.

Predicción meteorológica para el lunes, día 2

Muy nuboso o cubierto, con visibilidad reducida, tendiendo a abrir algunos claros a últimas horas. Precipitaciones débiles o moderadas, más frecuentes, intensas y generalizadas en la segunda mitad del día. Cota de nieve pudiendo subir hasta 2000-2200 metros a primeras horas, descendiendo de manera acusada después, hasta alcanzar unos 1300 a últimas horas. No se descarta alguna tormenta ocasional al final del día. Temperaturas con ligeros cambios. Heladas débiles o moderadas, localmente fuertes y persistentes en la alta montaña. Viento moderado o fuerte de componente sur, tendiendo a componente oeste al final del día. En cotas altas y zonas expuestas, se esperan rachas muy fuertes del suroeste, que podrán

AEMET. Se autoriza la reproducción de su contenido citando la fuente.

superar los 100 km/h.

Datos en la atmósfera libre:

Altitud de la isoterma de 0 ºC: 2400 m
Altitud de la isoterma de -10 ºC: 4200 m

Viento a 1500 m: SW 30 km/h
Viento a 3000 m: SW 100 km/h

Evolución para el martes día 3

Nivel de peligro con pocos cambios.

Escala europea de peligro de aludes

1 Débil | 2 Limitado | 3 Notable | 4 Fuerte | 5 Muy Fuerte

Problemas de aludes

Nieve reciente | Placas de viento | Capas débiles persistentes | Nieve húmeda | Deslizamientos basales | Sin problema evidente

Nota1: Se recuerda que, siempre que haya nieve, la ausencia total de peligro no existe. Hay que tener presente que en circunstancias desfavorables, con aludes de tamaño 1 (alud pequeño o colada) y tamaño 2 (alud mediano), se pueden sufrir severos daños personales.

Nota2: Los BPA se elaboran en base a información meteorológica así como al estado del manto nivoso a través de sondeos puntuales. Se advierte a los usuarios de la variabilidad de esta información al extrapolarla a zonas extensas de montaña. Por ello, AEMET no se hace responsable de su uso para la toma de decisiones que conciernen a la seguridad personal, ni de los riesgos físicos o materiales de ellas derivadas.

AEMET. Se autoriza la reproducción de su contenido citando la fuente.