GOBIERNO DE ESPAÑA
VICEPRESIDENCIA TERCERA DEL GOBIERNO
MINISTERIO PARA LA TRANSICIÓN ECOLÓGICA Y EL RETO DEMOGRÁFICO

Boletín de información nivológica y de peligro de aludes

Pirineo Navarro y Aragonés

aemet Agencia Estatal de Meteorología

domingo, 1 de febrero de 2026

Pronóstico hasta las 24 horas del lunes, día 2 de febrero

(Válido fuera de pistas de esquí balizadas y abiertas)

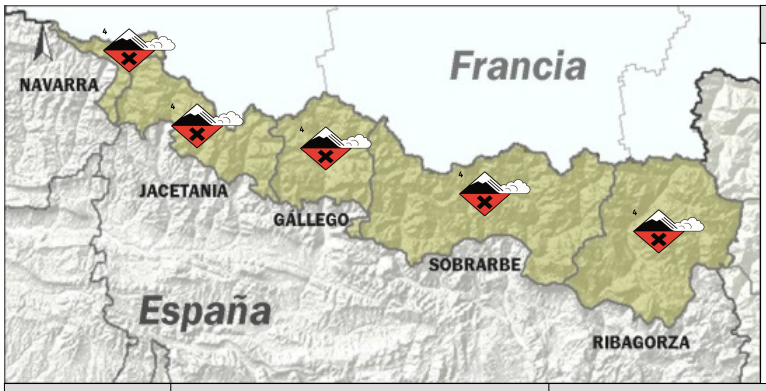

Problemas de aludes

Placas de viento

Nieve húmeda

Macizo	Peligro	Problemas de aludes, cota, orientación, tamaño	Innivación observada (m)
Navarra	4 / 4 3 2100 Fuerte	Placas de viento: 2100 ↑, N O E S, 3 Nieve húmeda: 2000 ↓, N O E S, 2	2026-02-01 N S Cotas bajas
Jacetania	4 / 4 3 2100 Fuerte	Placas de viento: 2100 ↑, N O E S, 3 Nieve húmeda: 2000 ↓, N O E S, 2	2026-02-01 N S Cotas bajas
Gállego	4 / 4 3 2100 Fuerte	Placas de viento: 2100 ↑, N O E S, 3 Nieve húmeda: 2000 ↓, N O E S, 2	2026-02-01 N S Cotas bajas

AEMET. Se autoriza la reproducción de su contenido citando la fuente.

Boletín de información nivológica y de peligro de aludes

Pirineo Navarro y Aragonés

Sobrarbe	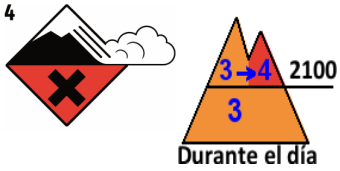 **Fuerte**	**Placas de viento** 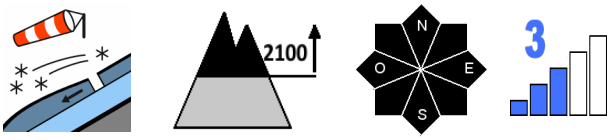 **Nieve húmeda** 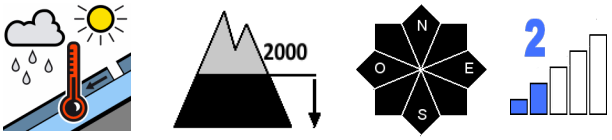	2026-02-01
Ribagorza	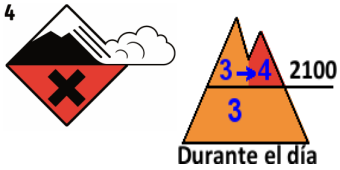 **Fuerte**	**Placas de viento** 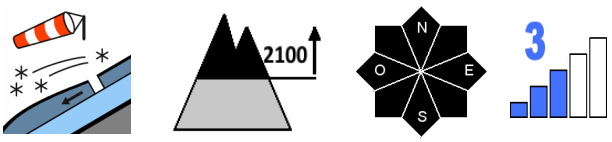 **Nieve húmeda** 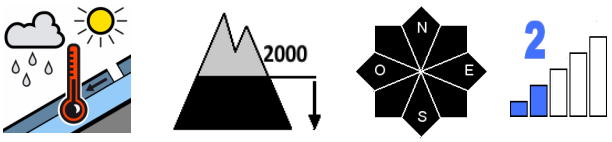	2026-02-01

Estado del manto y observaciones recientes

Continua la situación de inestabilidad con las bajas presiones y el chorro polar instalados en nuestras latitudes. Las acumulaciones de nieve se van sucediendo en la cordillera prácticamente a diario, aunque con cantidades muy variables, y están siendo acompañadas de intensos vientos.

Durante el día de ayer, se produjeron precipitaciones significativas en Navarra y Jacetania, con observaciones de 20-30mm, mientras que en el resto de macizos no se superaron los 10mm, salvo localmente en puntos de la divisoria fronteriza. La cota de nieve se mantuvo por debajo de unos 1200 metros y los vientos han dado lugar a una repartición muy desigual de la nieve nueva. Hoy será un día de transición donde la radiación solar provocará una cierta humidificación en las solanas, especialmente de la mitad oriental.

El manto comienza en cotas bajas, con espesores muy variables a causa del viento, pero que superan los 100-120 cm en torno a 1800 metros y los 150-200 cm por encima de 2100, notablemente más en ventisqueros y otras zonas de acumulación. Los espesores superan el percentil 80 de la serie histórica en la mayor parte de la red de observación.

En cotas altas, la nieve presenta muy grandes acumulaciones, manteniéndose seca y muy venteada en superficie mientras que, internamente y principalmente en umbrías, se observan niveles débiles de facetas, además de las antiguas capas débiles persistentes que siguen mostrando reactividad, como así confirman algunos de los últimos sondeos y aludes. En cotas inferiores, la nieve está más humedecida y estable, presentando generalmente una estructura superficial de nieve reciente sobre costra de rehielo.

AEMET. Se autoriza la reproducción de su contenido citando la fuente.

Se han reportado unos cuantos aludes durante los últimos días, a destacar tres de tamaño grande, dos de ellos naturales en el área de Panticosa, y un tercero accidental en el Pico Cibollés (Cerler), todos con estructura de placa sobre capa débil persistente y con salidas por encima de los 2300 metros.

Evolución del manto y peligro de aludes para el lunes, día 2

Problemas de placas de viento y capas débiles persistentes en cotas altas. Problemas de nieve reciente y nieve húmeda.

El mayor peligro se situará en cotas altas:
Allí, se formarán nuevas placas de viento, en orientaciones norte y este, que se sumarán a las numerosas ya existentes y que aún permanecen frágiles. De este modo, las podremos encontrar en todas las orientaciones y, con frecuencia, alejadas de crestas y collados. También podrán aparecer en cotas medias, aunque con tamaños más bien pequeños.
En las umbrías, las capas débiles persistentes antiguas siguen dando muestras de reactividad, siendo susceptibles de colapsar en zonas de manto delgado.
Ambos tipos de problema pueden dar lugar a aludes de tamaño grande con el paso de una sola persona, incluso en zonas ya transitadas, y no se descarta que localmente alcancen el tamaño muy grande.
En laderas con la suficiente inclinación, es de esperar actividad de purgas de nieve reciente, de tamaño pequeño o mediano.
Por último, cabe mencionar la proliferación de cornisas y la posibilidad de desencadenamiento de aludes bajo estas en caso de ruptura.

En cotas medias y bajas, las precipitaciones en forma de lluvia favorecerán los problemas de nieve húmeda, si bien la cota de nieve bajará notablemente por la tarde con la llegada de un frente frío. Las purgas y aludes asociados serán abundantes y podrán fácilmente alcanzar el tamaño mediano, sin descartar localmente el grande. Los deslizamientos basales también serán posibles.

Predicción meteorológica para el lunes, día 2

Pirineo navarro:
Muy nuboso o cubierto, con visibilidad reducida, tendiendo a abrir algunos claros a últimas horas. Precipitaciones débiles o moderadas, más frecuentes e intensas en la segunda mitad del día. Cota de nieve pudiendo subir hasta 2200 metros a primeras horas, descendiendo de manera acusada después, hasta alcanzar unos 1100 a últimas horas. Temperaturas sin cambios o en ligero ascenso, con las mínimas al final del día. Heladas débiles o moderadas, principalmente en cotas altas. Viento fuerte de componente sur, con intervalos de muy fuerte y rachas que, en cotas altas y zonas expuestas, podrán superar los 100 km/h.

Pirineo aragonés:
Muy nuboso o cubierto, con visibilidad reducida, tendiendo a abrir algunos claros a últimas horas. Precipitaciones débiles o moderadas, y persistentes, sin descartar que localmente puedan llegar a ser fuertes al final del día. Cota de nieve pudiendo subir hasta 2000-2200 metros a primeras horas, descendiendo de manera acusada después, hasta alcanzar unos 1200 a últimas horas. No se descarta alguna tormenta ocasional al final del día. Temperaturas con ligeros cambios, esperándose las mínimas al final del día. Heladas débiles o moderadas, localmente fuertes y persistentes en la alta montaña. Viento moderado o fuerte de

AEMET. Se autoriza la reproducción de su contenido citando la fuente.

componente sur, tendiendo a componente oeste al final del día. En cotas altas y zonas expuestas, se esperan rachas muy fuertes del suroeste, que podrán superar los 100 km/h.

Datos en la atmósfera libre:

Altitud de la isoterma de 0 ºC: 2200 m
Altitud de la isoterma de -10 ºC: 4100 m

Viento a 1500 m: S 35 km/h
Viento a 3000 m: SW 90 km/h

Evolución para el martes día 3

Nivel de peligro con pocos cambios.

(Información elaborada a partir de los datos recibidos de los refugios de Linza, Lizara, Panticosa, Bachimaña, Góriz, Pineta, Estós, Angel Orús, La Renclusa, Cap de Llauset y Belagua, de las estaciones de esquí de Formigal y Panticosa (lagos), de la estación de esquí de fondo de Llanos del Hospital y de Ordesa Pradera)

Escala europea de peligro de aludes

Débil | Limitado | Notable | Fuerte | Muy Fuerte

Problemas de aludes

Nieve reciente | Placas de viento | Capas débiles persistentes | Nieve húmeda | Deslizamientos basales | Sin problema evidente

Nota1: Se recuerda que, siempre que haya nieve, la ausencia total de peligro no existe. Hay que tener presente que en circunstancias desfavorables, con aludes de tamaño 1 (alud pequeño o colada) y tamaño 2 (alud mediano), se pueden sufrir severos daños personales.

Nota2: Los BPA se elaboran en base a información meteorológica así como al estado del manto nivoso a través de sondeos puntuales. Se advierte a los usuarios de la variabilidad de esta información al extrapolarla a zonas extensas de montaña. Por ello, AEMET no se hace responsable de su uso para la toma de decisiones que conciernen a la seguridad personal, ni de los riesgos físicos o materiales de ellas derivadas.

AEMET. Se autoriza la reproducción de su contenido citando la fuente.