ICGC Institut Cartogràfic i Geològic de Catalunya

Servei Meteorològic de Catalunya meteo.cat

Boletín de peligro de aludes para el Pirineo de Catalunya
Del 01/02/2026 al 02/02/2026

(Válido fuera pistas de esquí y zonas no controladas)

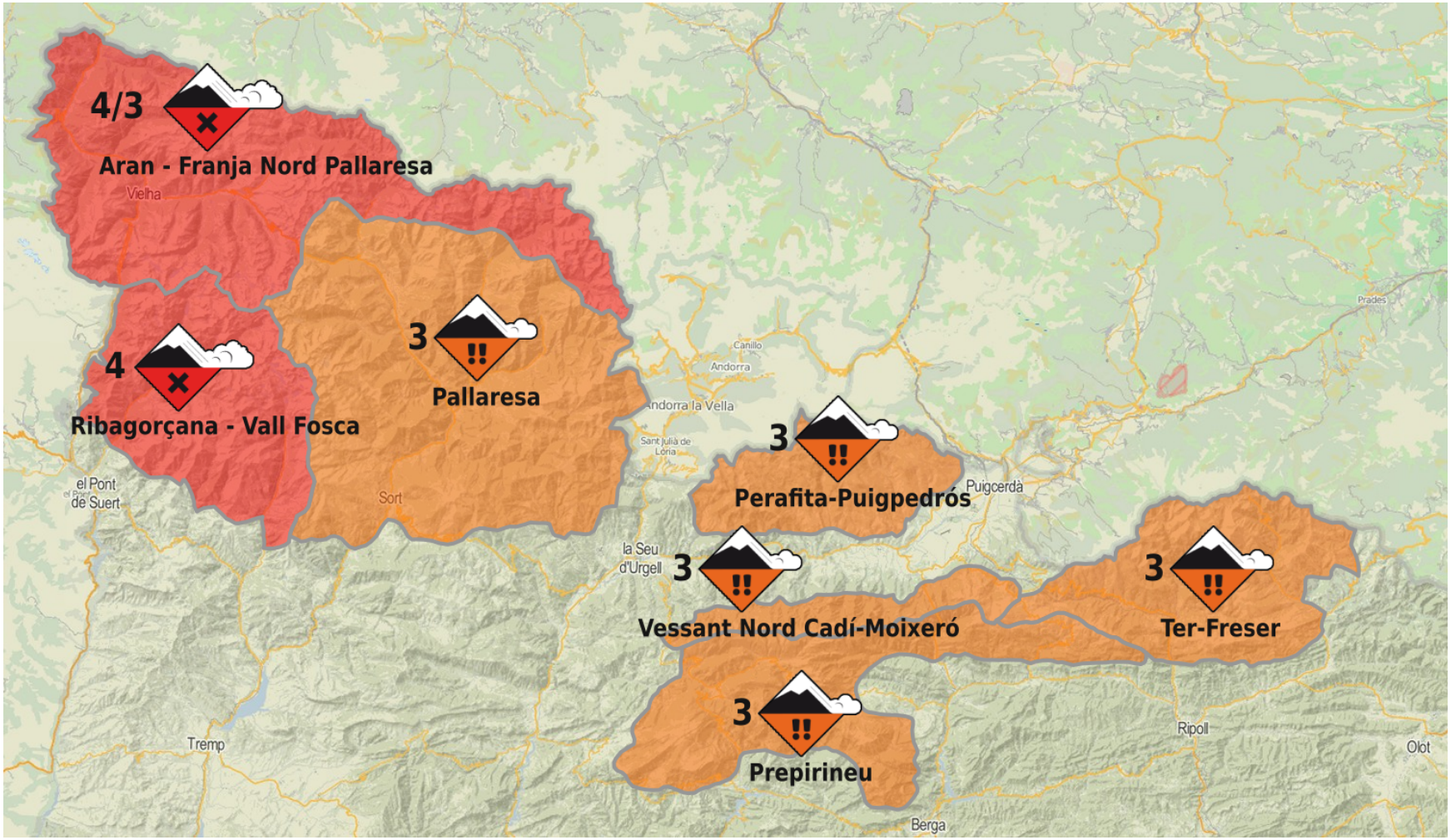

5 MUY FUERTE	4 FUERTE	3 NOTABLE	2 LIMITADO	1 DÉBIL

ICGC Institut Cartogràfic i Geològic de Catalunya

Servei Meteorològic de Catalunya meteo.cat

Boletín de peligro de aludes Aran - Franja Nord Pallaresa Del 01/02/2026 al 02/02/2026

(Válido fuera pistas de esquí y zonas no controladas)

FUERTE (4) extremo sur Aran y Franja Norte Pallaresa. NOTABLE (3) en el resto.

Situación primaria

Nieve venteada

Distribución

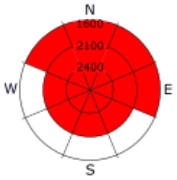

Tamaño

Origen

Tendencia

Situación secundaria

Nieve húmeda

Distribución

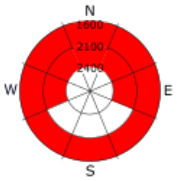

Tamaño

Origen

Tendencia

Estado del manto nivoso

El lunes desde la mañana se prevé una nevada de nieve húmeda con lluvia hasta 2.200 m (20-30 cm en la Franja Norte de la Pallaresa y extremo sur del Aran) y disminuirá mucho hacia el norte del Aran; durante el día irá descendiendo de cota hasta fondo de valle. El viento será fuerte de S y W. Se formarán muchas placas de viento frágiles sobre la nevada más seca del sábado noche (20-25 cm de nieve de poca consistencia). Se esperan aludes naturales de placa de viento de tamaño 3, grandes, suficiente para cubrir un grupo de personas en orientaciones NW, N, NE y E. También serán muy probables aludes naturales de nieve húmeda de tamaño 2, mediano, suficiente para cubrir a una persona, a cualquier orientación por debajo de 2.200 m. Se reactivarán los aludes de deslizamiento basal, por debajo de 2.200 m mayoritariamente. Se recomienda no realizar actividades cerca de terreno avalanchoso. En la mitad norte del Arán, el tamaño de los aludes será menor, por lo general de tamaño 2, mediano.

Distribución del manto nivoso

Hay nieve en el suelo a 800 m. El manto es esquiable por encima de unos 1.500 m. Los espesores a unos 2.200 m rondan los 100-140 cm en el norte del Arán y 130-170 cm en la Franja Norte Pallaresa y en el sur de Aran, y son superiores a los normales por estas fechas.

Tendencia para las próximas 48-72h

Se mantendrá la fragilidad de las placas de viento, pero disminuirá la probabilidad de aludes de nieve húmeda. Peligro EN LIGERO DESCENSO.

El próximo boletín será emitido el día 2026-02-02

5 MUY FUERTE	4 FUERTE	3 NOTABLE	2 LIMITADO	1 DÉBIL

EAWS EUROPEAN AVALANCHE WARNING SERVICES

ICGC Institut Cartogràfic i Geològic de Catalunya

Servei Meteorològic de Catalunya

Boletín de peligro de aludes Ribagorçana - Vall Fosca Del 01/02/2026 al 02/02/2026

(Válido fuera pistas de esquí y zonas no controladas)

FUERTE (4).

Situación primaria

Nieve venteada

Distribución

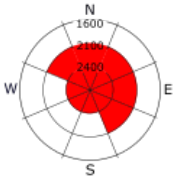

Tamaño

Origen

Tendencia

Situación secundaria

Nieve húmeda

Distribución

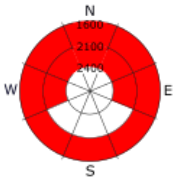

Tamaño

Origen

Tendencia

Estado del manto nivoso

El lunes desde la mañana se prevé una nevada de nieve húmeda con lluvia hasta 2.200 m (30-40 cm); durante el día irá descendiendo de cota hasta fondo de valle. El viento será fuerte de S y W. Se formarán muchas placas de viento frágiles sobre la nevada más seca del sábado noche (10-15 cm de nieve de poca consistencia). Se esperan aludes naturales de placa de viento de tamaño 3, grandes, suficiente para cubrir un grupo de personas en orientaciones NW, N, NE y E. También serán muy probables aludes naturales de nieve húmeda de tamaño 2, mediano, suficiente para cubrir a una persona, a cualquier orientación por debajo de 2.200 m. Se recomienda no realizar actividades cerca de terreno avalanchoso.

Distribución del manto nivoso

Hay nieve en el suelo a 1.200-1.300 m. El manto es esquiable por encima de unos 1.500 m. Los grosores alcanzan los 130-150 cm. Estos valores son muy superiores a los normales por la época.

Tendencia para las próximas 48-72h

Se mantendrá la fragilidad de las placas de viento, pero disminuirá la probabilidad de aludes de nieve húmeda. Peligro EN LIGERO DESCENSO.

El próximo boletín será emitido el día 2026-02-02

5 MUY FUERTE	4 FUERTE	3 NOTABLE	2 LIMITADO	1 DÉBIL

EAWS EUROPEAN AVALANCHE WARNING SERVICES

ICGC Institut Cartogràfic i Geològic de Catalunya

meteo.cat Servei Meteorològic de Catalunya

Boletín de peligro de aludes Pallaresa
Del 01/02/2026 al 02/02/2026

(Válido fuera pistas de esquí y zonas no controladas)

NOTABLE (3).

Situación primaria

Nieve venteada

Distribución

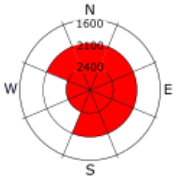

Tamaño

Origen

Tendencia

Situación secundaria

Nieve húmeda

Distribución

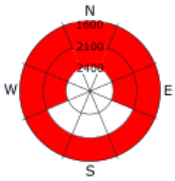

Tamaño

Origen

Tendencia

Estado del manto nivoso

El lunes desde la mañana se espera una nevada de nieve húmeda con lluvia hasta 2.200 m (aprox 20 cm); durante el día irá descendiendo de cota hasta fondo de valle. El viento será fuerte de S y W. Se formarán muchas placas de viento frágiles sobre la nevada más seca del sábado noche (10-15 cm de nieve de poca consistencia). Se esperan aludes naturales de placa de viento por lo general de tamaño 2, mediano, suficiente para cubrir una persona; puntualmente de hasta tamaño 3, grande, suficiente para cubrir un grupo de personas en orientaciones NW, N, NE y E. También serán muy probables aludes naturales de nieve húmeda de tamaño 2, mediano, en cualquier orientación por debajo de 2.200 m.

Distribución del manto nivoso

Hay nieve desde 1.200 a 1.300 m, esquiable a 1.500 m. Los espesores en cotas altas y medias rondan o superan los 130 cm. Estos valores son superiores a los normales para la época.

Tendencia para las próximas 48-72h

Se mantendrá la fragilidad de las placas de viento, pero disminuirá la probabilidad de aludes de nieve húmeda. Peligro EN LIGERO DESCENSO.

El próximo boletín será emitido el día 2026-02-02

5 MUY FUERTE	4 FUERTE	3 NOTABLE	2 LIMITADO	1 DÉBIL

EAWS EUROPEAN AVALANCHE WARNING SERVICES

ICGC Institut Cartogràfic i Geològic de Catalunya

Servei Meteorològic de Catalunya

Boletín de peligro de aludes Perafita-Puigpedrós Del 01/02/2026 al 02/02/2026

(Válido fuera pistas de esquí y zonas no controladas)

NOTABLE (3).

Situación primaria

Nieve venteada

Distribución

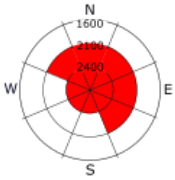

Tamaño

Origen

Tendencia

Situación secundaria

Nieve húmeda

Distribución

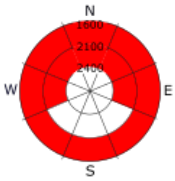

Tamaño

Origen

Tendencia

Estado del manto nivoso

El lunes desde la mañana se prevé una nevada de nieve húmeda con lluvia hasta 2.200 m (10-15 cm); durante el día irá descendiendo de cota hasta fondo de valle. El viento será fuerte de S y W. Se formarán muchas placas de viento frágiles sobre la nevada más seca del sábado noche (10-15 cm de nieve de poca consistencia). Se esperan aludes naturales de placa de viento por lo general de tamaño 2, mediano, suficiente para cubrir una persona; puntualmente de hasta tamaño 3, grande, suficiente para cubrir un grupo de personas en orientaciones NW, N, NE y E. También serán muy probables aludes naturales de nieve húmeda de tamaño 2, mediano, en cualquier orientación por debajo de 2.200 m.

Distribución del manto nivoso

Hay nieve en el suelo por encima de 1.300 m. Sin embargo, el manto es esquiable por encima de 1.500-1.600 m. Los grosores alcanzan los 120-140 cm a 2.200 m. Son grosores muy por encima de los habituales por la época.

Tendencia para las próximas 48-72h

Se mantendrá la fragilidad de las placas de viento, pero disminuirá la probabilidad de aludes de nieve húmeda. Peligro EN LIGERO DESCENSO.

El próximo boletín será emitido el día 2026-02-02

5 MUY FUERTE	4 FUERTE	3 NOTABLE	2 LIMITADO	1 DÉBIL

EAWS EUROPEAN AVALANCHE WARNING SERVICES

ICGC Institut Cartogràfic i Geològic de Catalunya

Servei Meteorològic de Catalunya meteo.cat

Boletín de peligro de aludes
Vessant Nord Cadí-Moixeró
Del 01/02/2026 al 02/02/2026

(Válido fuera pistas de esquí y zonas no controladas)

NOTABLE (3).

Situación primaria

Nieve venteada

Distribución

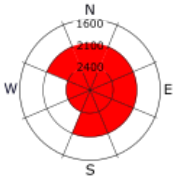

Tamaño

Origen

Tendencia

Situación secundaria

Nieve húmeda

Distribución

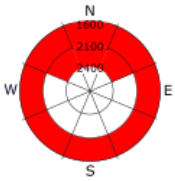

Tamaño

Origen

Tendencia

Estado del manto nivoso

El lunes desde la mañana se prevé una nevada de nieve húmeda con lluvia hasta 2.200 m (10-15 cm); durante el día irá descendiendo de cota hasta fondo de valle. El viento será fuerte de S y W. Se formarán muchas placas de viento frágiles sobre la nevada más seca del sábado noche (10-15 cm de nieve de poca consistencia). Se esperan aludes naturales de placa de viento por lo general de tamaño 2, mediano, suficiente para cubrir una persona; puntualmente en las canales del Cadí de hasta tamaño 3, grande, suficiente para cubrir un grupo de personas en orientaciones NW, N, NE y E. También serán muy probables aludes naturales de nieve húmeda de tamaño 2, mediano, en cualquier orientación por debajo de 2.200 m.

Distribución del manto nivoso

Hay nieve desde 1.200 a 1.300 m, esquiable por encima de unos 1.500 m. Los grosores están alrededor de 100-150 cm a 2.200 m, valores muy excedentarios para la época del año.

Tendencia para las próximas 48-72h

Se mantendrá la fragilidad de las placas de viento, pero disminuirá la probabilidad de aludes de nieve húmeda. Peligro EN LIGERO DESCENSO.

El próximo boletín será emitido el día 2026-02-02

5 MUY FUERTE	4 FUERTE	3 NOTABLE	2 LIMITADO	1 DÉBIL

EAWS EUROPEAN AVALANCHE WARNING SERVICES

ICGC Institut Cartogràfic i Geològic de Catalunya

Servei Meteorològic de Catalunya

Boletín de peligro de aludes Prepirineu
Del 01/02/2026 al 02/02/2026

(Válido fuera pistas de esquí y zonas no controladas)

NOTABLE (3).

Situación primaria

Nieve venteada

Distribución

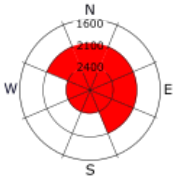

Tamaño

Origen

Tendencia

Situación secundaria

Nieve húmeda

Distribución

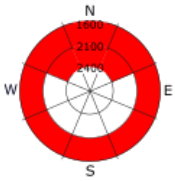

Tamaño

Origen

Tendencia

Estado del manto nivoso

El lunes desde la mañana se prevé una nevada de nieve húmeda con lluvia hasta 2.200 m (10-15 cm); durante el día irá descendiendo de cota hasta fondo de valle. El viento será fuerte de S y W. Se formarán muchas placas de viento frágiles sobre la nevada más seca del sábado noche (aprox 5 cm de nieve de poca consistencia). Se esperan aludes naturales de placa de viento por lo general de tamaño 2, mediano, suficiente para cubrir una persona; puntualmente de hasta tamaño 3, grande, suficiente para cubrir un grupo de personas en orientaciones NW, N, NE y E. También serán muy probables aludes naturales de nieve húmeda de tamaño 2, mediano, en cualquier orientación por debajo de 2.200 m.

Distribución del manto nivoso

Hay nieve desde 1.300 m. El manto es esquiable a partir de 1.600 m. Los grosores están alrededor de 90-110 cm a unos 2.200 m; son superiores a los habituales.

Tendencia para las próximas 48-72h

Se mantendrá la fragilidad de las placas de viento, pero disminuirá la probabilidad de aludes de nieve húmeda. Peligro EN LIGERO DESCENSO.

El próximo boletín será emitido el día 2026-02-02

5 MUY FUERTE	4 FUERTE	3 NOTABLE	2 LIMITADO	1 DÉBIL

EAWS EUROPEAN AVALANCHE WARNING SERVICES

ICGC Institut Cartogràfic i Geològic de Catalunya

meteo.cat Servei Meteorològic de Catalunya

Boletín de peligro de aludes Ter-Freser Del 01/02/2026 al 02/02/2026

(Válido fuera pistas de esquí y zonas no controladas)

NOTABLE (3).

Situación primaria

Nieve venteada

Distribución

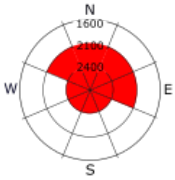

Tamaño

Origen

Tendencia

Situación secundaria

Nieve húmeda

Distribución

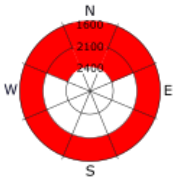

Tamaño

Origen

Tendencia

Estado del manto nivoso

El lunes desde la mañana se contempla una nevada de nieve húmeda con lluvia hasta 2.200 m (aprox 10 cm); durante el día irá descendiendo de cota hasta fondo de valle. El viento será fuerte de S y W. Se formarán muchas placas de viento frágiles sobre la nevada más seca del sábado noche (5-10 cm de nieve de poca consistencia). Se esperan aludes naturales de placa de viento por lo general de tamaño 2, mediano, suficiente para cubrir una persona; puntualmente de hasta tamaño 3, grande, suficiente para cubrir un grupo de personas en orientaciones NW, N, NE y E. También serán muy probables aludes naturales de nieve húmeda de tamaño 2, mediano, en cualquier orientación por debajo de 2.200 m.

Distribución del manto nivoso

Hay nieve desde 1.300 m, esquiable por encima de 1.500 a 1.600 m. Los espesores rondan los 90-130 cm a unos 2.000 my son muy excedentarios para la época del año.

Tendencia para las próximas 48-72h

Se mantendrá la fragilidad de las placas de viento, pero disminuirá la probabilidad de aludes de nieve húmeda. Peligro EN LIGERO DESCENSO.

El próximo boletín será emitido el día 2026-02-02

5 MUY FUERTE	4 FUERTE	3 NOTABLE	2 LIMITADO	1 DÉBIL

EAWS EUROPEAN AVALANCHE WARNING SERVICES