MINISTERO DELLA DIFESA

meteomont
Servizio Nazionale di previsione neve e valanghe

EAWS EUROPEAN AVALANCHE WARNING SERVICES

CARABINIERI

ALPI CARNICHE OCCIDENTALI

Bollettino Valanghe N. 332/2026 del 01/02/2026 ore 14.00
Validità 48 ore prossima emissione 02/02/2026

A cura del Servizio METEOMONT dell'ARMA dei CARABINIERI
In collaborazione con Servizio Meteorologico dell'Aeronautica militare

SITUAZIONE alle 14:00 del 01/02/2026

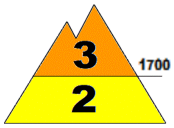

SITUAZIONE TIPO: nevicata dopo un lungo periodo di freddo.

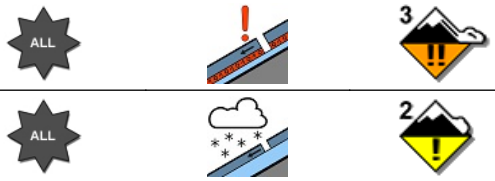

SITUAZIONE TIPO: nessuna situazione tipo evidente.

Quota neve (mslm)	Nord	Sud
	700	800

Altezza Neve (cm)	Neve al suolo	Neve Fresca	Quota (mslm)
	90	00	1710
	53	00	1425

VALANGHE OSSERVATE: Valanghe di piccole dimensioni, Valanghe di neve a debole coesione di superficie.

PREVISIONI 02/02/2026

GRADO DI PERICOLO: MARCATO 3

SITUAZIONE TIPO: neve a debole coesione e vento.

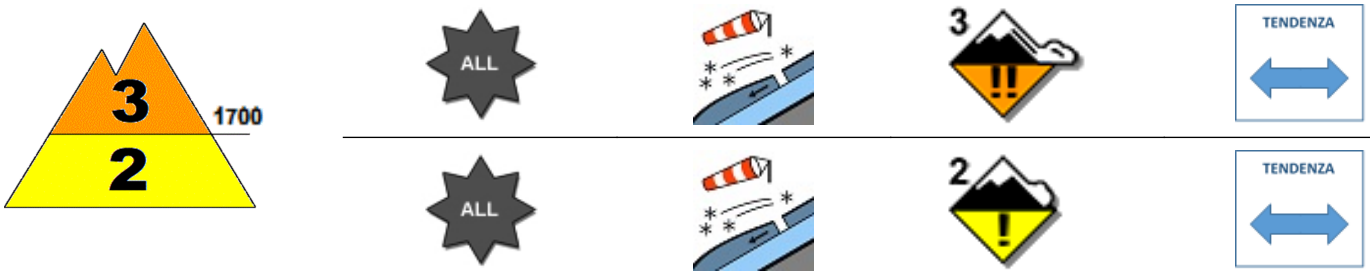

SITUAZIONE TIPO: neve a debole coesione e vento.

MANTO NEVOSO: La stabilità del manto nevoso è molto scarsa su molti punti (aree) per tutte le esposizioni al di sopra di 1700 mslm, possibili valanghe di dimensioni medie.
La stabilità del manto nevoso è scarsa su alcuni punti (aree) per tutte le esposizioni al di sotto di 1700 mslm, possibili valanghe di dimensioni medie.

AVVERTENZE

In considerazione dei recenti apporti di neve fresca, è richiesta un'ottima valutazione locale della stabilità ed individuazione dell'itinerario.

SCALA EUROPEA DEL GRADO DI PERICOLO VALANGHE

5 - MOLTO FORTE | 4 - FORTE | 3 - MARCATO | 2 - MODERATO | 1 - DEBOLE | NO NEVE | NO INFO

LEGENDA PROBLEMA

NEVE FRESCA | LASTRONI DA VENTO | STRATI DEBOLI PERSISTENTI | NEVE BAGNATA | SLITTAMENTO | CORNICI | NESSUN PROBLEMA VALANGHIVO EVIDENTE | NO_INFO

Bollettino realizzato su scala sinottica-regionale (standard EAWS). La sua valutazione non può escludere in alcun modo la necessità di una seria e capace valutazione locale del pericolo (singolo pendio) che può essere anche sensibilmente diverso. Le previsioni meteorologiche sono relative all'orario UTC (per l'Italia +1 in inverno e +2 in estate).

MINISTERO DELLA DIFESA

meteomont
Servizio Nazionale di previsione neve e valanghe

EAWS EUROPEAN AVALANCHE WARNING SERVICES

CARABINIERI

ALPI CARNICHE OCCIDENTALI

PREVISIONE METEO

Quota		02/02/2026 h6:00	02/02/2026 h12:00	02/02/2026 h18:00
1000	Venti	01 Nodi da Sud	01 Nodi da Est	01 Nodi da S-Est
	Temperature	-06 °C	-06 °C	-06 °C
	Temp.percepita	-6 °C	-6 °C	-6 °C
2000	Venti	01 Nodi da Ovest	01 Nodi da Nord	01 Nodi da Sud
	Temperature	-07 °C	-06 °C	-07 °C
	Temp.percepita	-7 °C	-6 °C	-7 °C
3000	Venti	02 nodi da N-Ovest	02 Nodi da Ovest	07 Nodi da S-Ovest
	Temperature	-10 °C	-09 °C	-08 °C
	Temp.percepita	-10 °C	-9 °C	-14 °C
Zero termico		0000-0200 m.	0300-0500 m.	0100-0300 m.
Fenomeno		—	—	—
Stato del cielo				

LEGENDA FENOMENI

— Assenza Fenomeni · Nebbia · Foschia · Pioggia debole · Pioggia moderata · Pioggia forte · Temporali

Nevicata debole · Nevicata moderata · Nevicata forte

STATO DEL CIELO

Sereno · Poco nuvoloso · Nuvoloso · Molto nuvoloso · Coperto

Parametri meteonivometrici registrati presso i campi di rilevamento il 01/02/2026.

Località	Comune	Quota (m.s.l.m.)	Altezza neve (cm)	Neve caduta nelle 24 ore (cm)	Temp. Min (°C)	Temp. Max (°C)	Condizioni del tempo
SAURIS DI SOPRA	Sauris (UD)	1425	53	0	-3	+9	Assenza di precipitazioni

(*) Rilievi fuori campo

L'INFORMAZIONE E' PREVENZIONE - LEGGI L'ATTUALE GRADO DI PERICOLO VALANGHE!

IL CAPO DEL CENTRO NAZIONALE METEOMONT
(Ten. Col. RFI Emanuela Gini)
FIRMA AUTOGRAFA OMESSA AI SENSI
DELL'ART.3 DEL D.LGS N.39/1993