MINISTERO DELLA DIFESA

meteomont Servizio Nazionale di previsione neve e valanghe

EAWS EUROPEAN AVALANCHE WARNING SERVICES

CARABINIERI

In collaborazione con: arpav

DOLOMITI MERIDIONALI

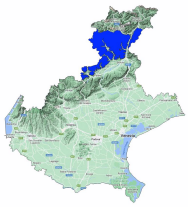

Bollettino Valanghe N. 334/2026 del 01/02/2026 ore 14.00
Validità 48 ore prossima emissione 02/02/2026

A cura del Servizio METEOMONT dell'ARMA dei CARABINIERI
In collaborazione con Servizio Meteorologico dell'Aeronautica militare

SITUAZIONE alle 14:00 del 01/02/2026

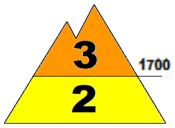

SITUAZIONE TIPO: nevicata dopo un lungo periodo di freddo.

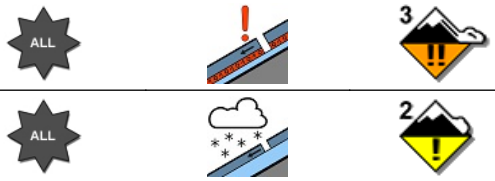

SITUAZIONE TIPO: nessuna situazione tipo evidente.

Quota neve (mslm)	Nord	Sud
	1100	1200 - 1300

Altezza Neve (cm)	Neve al suolo	Neve Fresca	Quota (mslm)
	75	00	2227
	50	00	1365

VALANGHE OSSERVATE: Valanghe di piccole dimensioni, Valanghe a lastroni di fondo.

PREVISIONI 02/02/2026

GRADO DI PERICOLO: MARCATO 3

SITUAZIONE TIPO: neve a debole coesione e vento.

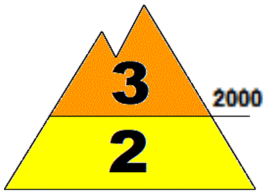

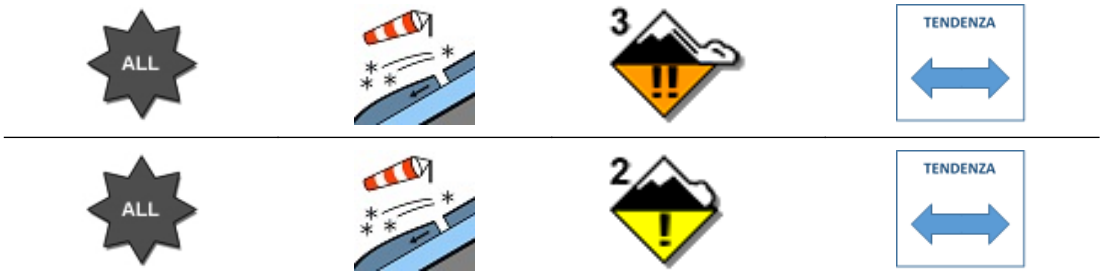

SITUAZIONE TIPO: neve a debole coesione e vento.

MANTO NEVOSO: La stabilità del manto nevoso è molto scarsa su molti punti (aree) per tutte le esposizioni al di sopra di 2000 mslm, possibili valanghe di dimensioni medie.
La stabilità del manto nevoso è scarsa su alcuni punti (aree) per tutte le esposizioni al di sotto di 2000 mslm, possibili valanghe di dimensioni medie.

AVVERTENZE

In considerazione dei recenti apporti di neve fresca, è richiesta un'ottima valutazione locale della stabilità ed individuazione dell'itinerario.

SCALA EUROPEA DEL GRADO DI PERICOLO VALANGHE

LEGENDA PROBLEMA

Bollettino realizzato su scala sinottica-regionale (standard EAWS). La sua valutazione non può escludere in alcun modo la necessità di una seria e capace valutazione locale del pericolo (singolo pendio) che può essere anche sensibilmente diverso. Le previsioni meteorologiche sono relative all'orario UTC (per l'Italia +1 in inverno e +2 in estate).

MINISTERO DELLA DIFESA

meteomont
Servizio Nazionale di previsione neve e valanghe

EAWS EUROPEAN AVALANCHE WARNING SERVICES

CARABINIERI

In collaborazione con: arpav

DOLOMITI MERIDIONALI

PREVISIONE METEO

Quota		02/02/2026 h6:00	02/02/2026 h12:00	02/02/2026 h18:00
1000	Venti	01 Nodi da Sud	01 Nodi da Est	00 Calma
	Temperature	-04 °C	-03 °C	-04 °C
	Temp.percepita	-4 °C	-3 °C	-4 °C
2000	Venti	02 Nodi da Ovest	01 nodi da N-Ovest	03 Nodi da Ovest
	Temperature	-06 °C	-04 °C	-06 °C
	Temp.percepita	-6 °C	-4 °C	-9 °C
3000	Venti	03 nodi da N-Ovest	04 Nodi da Ovest	11 Nodi da Ovest
	Temperature	-10 °C	-09 °C	-08 °C
	Temp.percepita	-13 °C	-13 °C	-15 °C
Zero termico		0000-0200 m.	0900-1100 m.	0200-0400 m.
Fenomeno		—	—	—
Stato del cielo				

LEGENDA FENOMENI

Assenza Fenomeni — Nebbia — Foschia — Pioggia debole — Pioggia moderata — Pioggia forte — Temporali

Nevicata debole — Nevicata moderata — Nevicata forte

STATO DEL CIELO

Sereno — Poco nuvoloso — Nuvoloso — Molto nuvoloso — Coperto

Parametri meteonivometrici registrati presso i campi di rilevamento il 01/02/2026.

Località	Comune	Quota (m.s.l.m.)	Altezza neve (cm)	Neve caduta nelle 24 ore (cm)	Temp. Min (°C)	Temp. Max (°C)	Condizioni del tempo
LE BUSE	Falcade (BL)	1820	59	0	-9	+10	Assenza di precipitazioni
P.SO PADON	Livinallongo del Col di Lana (BL)	2369	67	0	-9	+6	Assenza di precipitazioni

(*) Rilievi fuori campo

L'INFORMAZIONE E' PREVENZIONE - LEGGI L'ATTUALE GRADO DI PERICOLO VALANGHE!

IL CAPO DEL CENTRO NAZIONALE METEOMONT
(Ten. Col. RFI Emanuela Gini)
FIRMA AUTOGRAFA OMESSA AI SENSI
DELL'ART.3 DEL D.LGS N.39/1993