MINISTERO DELLA DIFESA

meteomont
Servizio Nazionale di previsione neve e valanghe

EAWS EUROPEAN AVALANCHE WARNING SERVICES

CARABINIERI

ALPI OROBICHE

Bollettino Valanghe N. 332/2026 del 01/02/2026 ore 14.00
Validità 48 ore prossima emissione 02/02/2026

A cura del Servizio METEOMONT dell'ARMA dei CARABINIERI
In collaborazione con Servizio Meteorologico dell'Aeronautica militare

SITUAZIONE alle 14:00 del 01/02/2026

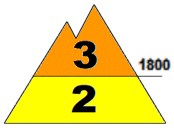

SITUAZIONE TIPO: freddo su caldo / caldo su freddo.

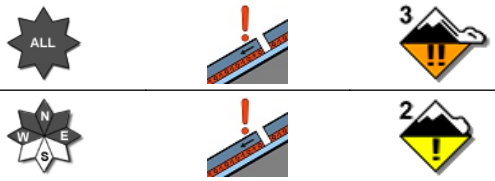

SITUAZIONE TIPO: freddo su caldo / caldo su freddo.

Quota neve (mslm)	Nord	Sud
	900 - 1100	1200 - 1500

Altezza Neve (cm)	Neve al suolo	Neve Fresca	Quota (mslm)
	105	0	2080
	56	0	1635

VALANGHE OSSERVATE: Valanghe di piccole dimensioni, Valanghe a lastroni di superficie.

PREVISIONI 02/02/2026

GRADO DI PERICOLO: MARCATO 3

SITUAZIONE TIPO: freddo su caldo / caldo su freddo.

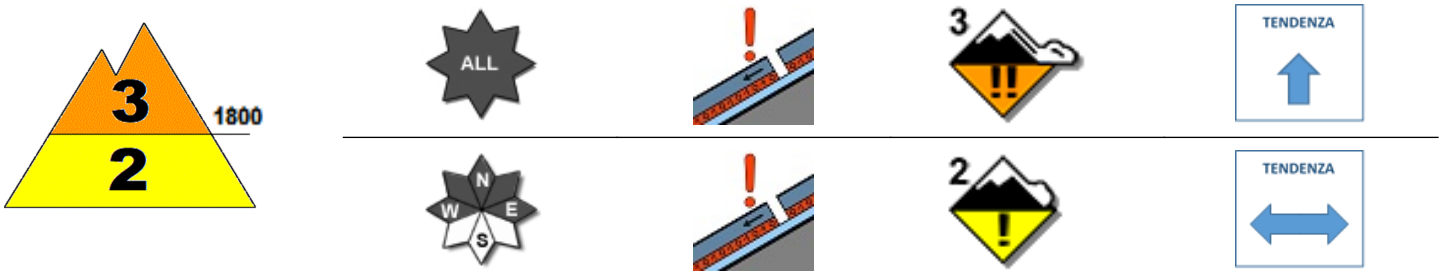

SITUAZIONE TIPO: passaggio da poca a molta neve.

MANTO NEVOSO: La stabilità del manto nevoso è scarsa su molti punti (aree) per tutte le esposizioni al di sopra di 1800 mslm, possibili valanghe di dimensioni medie.
La stabilità del manto nevoso è scarsa su alcuni punti (aree) per versanti da ovest a est al di sotto di 1800 mslm, possibili valanghe di dimensioni piccole.

AVVERTENZE

Viste le condizioni del manto nevoso, le attività al di fuori delle piste battute e segnalate richiedono ottime capacità di valutazione del pericolo locale.

SCALA EUROPEA DEL GRADO DI PERICOLO VALANGHE

LEGENDA PROBLEMA

Bollettino realizzato su scala sinottica-regionale (standard EAWS). La sua valutazione non può escludere in alcun modo la necessità di una seria e capace valutazione locale del pericolo (singolo pendio) che può essere anche sensibilmente diverso. Le previsioni meteorologiche sono relative all'orario UTC (per l'Italia +1 in inverno e +2 in estate).

MINISTERO DELLA DIFESA

meteomont
Servizio Nazionale di previsione neve e valanghe

EAWS EUROPEAN AVALANCHE WARNING SERVICES

CARABINIERI

ALPI OROBICHE

PREVISIONE METEO

Quota		02/02/2026 h6:00	02/02/2026 h12:00	02/02/2026 h18:00
1000	Venti	01 Nodi da N-Est	03 Nodi da S-Ovest	00 Calma
	Temperature	-04 °C	-05 °C	-03 °C
	Temp.percepita	-4 °C	-8 °C	-3 °C
2000	Venti	01 nodi da N-Ovest	03 Nodi da S-Ovest	03 Nodi da Ovest
	Temperature	-06 °C	-06 °C	-04 °C
	Temp.percepita	-6 °C	-9 °C	-6 °C
3000	Venti	03 nodi da Ovest	04 Nodi da Ovest	11 Nodi da S-Ovest
	Temperature	-10 °C	-09 °C	-10 °C
	Temp.percepita	-13 °C	-13 °C	-18 °C
Zero termico		0100-0300 m.	0500-0700 m.	0800-1000 m.
Fenomeno		—	—	—
Stato del cielo				

LEGENDA FENOMENI

— Assenza Fenomeni
Nebbia
Foschia
Pioggia debole
Pioggia moderata
Pioggia forte
Temporali
Nevicata debole
Nevicata moderata
Nevicata forte

STATO DEL CIELO

Sereno
Poco nuvoloso
Nuvoloso
Molto nuvoloso
Coperto

Parametri meteonivometrici registrati presso i campi di rilevamento il 01/02/2026.

Località	Comune	Quota (m.s.l.m.)	Altezza neve (cm)	Neve caduta nelle 24 ore (cm)	Temp. Min (°C)	Temp. Max (°C)	Condizioni del tempo
VODALA	Gromo (BG)	1635	56	0	-4	+2	Assenza di precipitazioni
QUARTA BAITA	Foppolo (BG)	1760	58	0	-7	+1	Assenza di precipitazioni
CIMA BIANCA	Colere (BG)	2080	105	0	-6	+1	Assenza di precipitazioni

(*) Rilievi fuori campo

L'INFORMAZIONE E' PREVENZIONE - LEGGI L'ATTUALE GRADO DI PERICOLO VALANGHE!

IL CAPO DEL CENTRO NAZIONALE METEOMONT
(Ten. Col. RFI Emanuela Gini)
FIRMA AUTOGRAFA OMESSA AI SENSI
DELL'ART.3 DEL D.LGS N.39/1993

Bollettino realizzato su scala sinottica-regionale (standard EAWS). La sua valutazione non può escludere in alcun modo la necessità di una seria e capace valutazione locale del pericolo (singolo pendio) che può essere anche sensibilmente diverso. Le previsioni meteorologiche sono relative all'orario UTC (per l'Italia +1 in inverno e +2 in estate).