MINISTERO DELLA DIFESA

meteomont
Servizio Nazionale di previsione neve e valanghe

EAWS EUROPEAN AVALANCHE WARNING SERVICES

CARABINIERI

ALPI LIGURI NORD

Bollettino Valanghe N. 332/2026 del 01/02/2026 ore 14.00
Validità 48 ore prossima emissione 02/02/2026

A cura del Servizio METEOMONT dell'ARMA dei CARABINIERI
In collaborazione con Servizio Meteorologico dell'Aeronautica militare

SITUAZIONE alle 14:00 del 01/02/2026

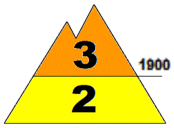

SITUAZIONE TIPO: neve a debole coesione e vento.



SITUAZIONE TIPO: neve da slittamento.

Quota neve (mslm)	Nord	Sud
	600	700

Altezza Neve (cm)	Neve al suolo	Neve Fresca	Quota (mslm)
	170	000	1930
	145	000	1625

VALANGHE OSSERVATE: -.

PREVISIONI 02/02/2026

GRADO DI PERICOLO: MARCATO 3

SITUAZIONE TIPO: neve a debole coesione e vento.

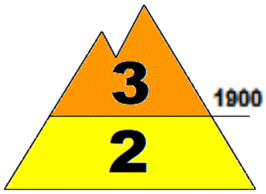

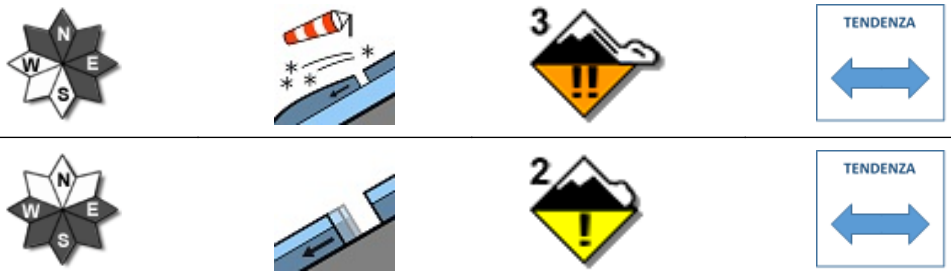

SITUAZIONE TIPO: neve da slittamento.

MANTO NEVOSO: La stabilità del manto nevoso è molto scarsa su alcuni punti (aree) per versanti da nord ovest a sud est compresi al di sopra di 1900 mslm, possibili valanghe di dimensioni grandi.
La stabilità del manto nevoso è scarsa su alcuni punti (aree) per versanti da est a ovest al di sotto di 1900 mslm, possibili valanghe di dimensioni medie.

AVVERTENZE

Viste le condizioni del manto nevoso, le attività al di fuori delle piste battute e segnalate richiedono buone capacità di valutazione del pericolo locale.

SCALA EUROPEA DEL GRADO DI PERICOLO VALANGHE

5 - MOLTO FORTE | 4 - FORTE | 3 - MARCATO | 2 - MODERATO | 1 - DEBOLE | NO NEVE | NO INFO

LEGENDA PROBLEMA

NEVE FRESCA | LASTRONI DA VENTO | STRATI DEBOLI PERSISTENTI | NEVE BAGNATA | SLITTAMENTO | CORNICI | NESSUN PROBLEMA VALANGHIVO EVIDENTE | NO_INFO

Bollettino realizzato su scala sinottica-regionale (standard EAWS). La sua valutazione non può escludere in alcun modo la necessità di una seria e capace valutazione locale del pericolo (singolo pendio) che può essere anche sensibilmente diverso. Le previsioni meteorologiche sono relative all'orario UTC (per l'Italia +1 in inverno e +2 in estate).

MINISTERO DELLA DIFESA

meteomont
Servizio Nazionale di previsione neve e valanghe

EAWS EUROPEAN AVALANCHE WARNING SERVICES

CARABINIERI

ALPI LIGURI NORD

PREVISIONE METEO

Quota		02/02/2026 h6:00	02/02/2026 h12:00	02/02/2026 h18:00
1000	Venti	01 Nodi da Ovest	00 Calma	01 nodi da N-Ovest
	Temperature	-04 °C	-04 °C	-04 °C
	Temp.percepita	-4 °C	-4 °C	-4 °C
2000	Venti	03 Nodi da Sud	03 Nodi da Sud	05 Nodi da Sud
	Temperature	-04 °C	-05 °C	-03 °C
	Temp.percepita	-6 °C	-8 °C	-7 °C
3000	Venti	11 Nodi da Ovest	05 Nodi da Ovest	14 Nodi da Sud
	Temperature	-07 °C	-05 °C	-06 °C
	Temp.percepita	-14 °C	-9 °C	-14 °C
Zero termico		0300-0500 m.	0600-0800 m.	0800-1000 m.
Fenomeno		—	—	
Stato del cielo				

LEGENDA FENOMENI

— Assenza Fenomeni
Nebbia
Foschia
Pioggia debole
Pioggia moderata
Pioggia forte
Temporali
Nevicata debole
Nevicata moderata
Nevicata forte

STATO DEL CIELO

Sereno
Poco nuvoloso
Nuvoloso
Molto nuvoloso
Coperto

(*) Dati meteonivometrici non presenti.

L'INFORMAZIONE E' PREVENZIONE - LEGGI L'ATTUALE GRADO DI PERICOLO VALANGHE!

IL CAPO DEL CENTRO NAZIONALE METEOMONT
(Ten. Col. RFI Emanuela Gini)
FIRMA AUTOGRAFA OMESSA AI SENSI
DELL'ART.3 DEL D.LGS N.39/1993

Bollettino realizzato su scala sinottica-regionale (standard EAWS). La sua valutazione non può escludere in alcun modo la necessità di una seria e capace valutazione locale del pericolo (singolo pendio) che può essere anche sensibilmente diverso. Le previsioni meteorologiche sono relative all'orario UTC (per l'Italia +1 in inverno e +2 in estate).