MINISTERO DELLA DIFESA

meteomont Servizio Nazionale di previsione neve e valanghe

EAWS EUROPEAN AVALANCHE WARNING SERVICES

CARABINIERI

APPENNINO EMILIANO CENTRALE

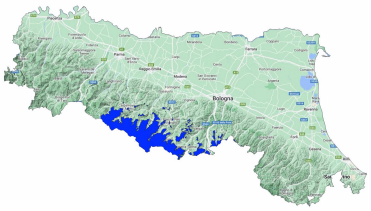

Bollettino Valanghe N. 305/2026 del 01/02/2026 ore 14.00
Validità 48 ore prossima emissione 02/02/2026

A cura del Servizio METEOMONT dell'ARMA dei CARABINIERI
In collaborazione con Servizio Meteorologico dell'Aeronautica militare

SITUAZIONE alle 14:00 del 01/02/2026

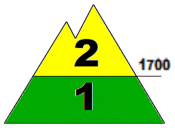

SITUAZIONE TIPO: passaggio da poca a molta neve.

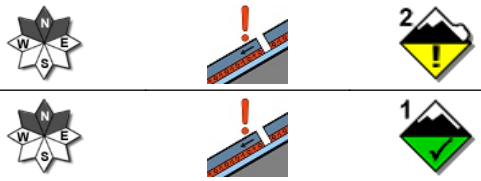

SITUAZIONE TIPO: passaggio da poca a molta neve.

Quota neve (mslm)	Nord	Sud
	1200 - 1300	1300

Altezza Neve (cm)	Neve al suolo	Neve Fresca	Quota (mslm)
	089	002	1840
	028	000	1550

VALANGHE OSSERVATE: Nessuna valanga.

PREVISIONI 02/02/2026

GRADO DI PERICOLO: MODERATO 2

SITUAZIONE TIPO: passaggio da poca a molta neve.

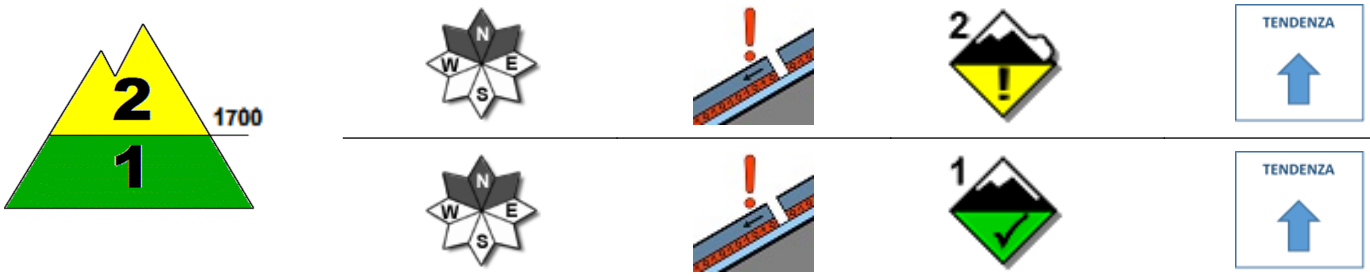

SITUAZIONE TIPO: passaggio da poca a molta neve.

MANTO NEVOSO: La stabilità del manto nevoso è scarsa su pochi punti (aree) per versanti settentrionali al di sopra di 1700 mslm, possibili valanghe di dimensioni medie.
La stabilità del manto nevoso è discreta su pochi punti (aree) per versanti settentrionali al di sotto di 1700 mslm, possibili valanghe di dimensioni piccole.

AVVERTENZE

In considerazione dei recenti apporti di neve fresca, è richiesta un'ottima valutazione locale della stabilità ed individuazione dell'itinerario.

SCALA EUROPEA DEL GRADO DI PERICOLO VALANGHE

5 - MOLTO FORTE | 4 - FORTE | 3 - MARCATO | 2 - MODERATO | 1 - DEBOLE | NO NEVE | NO INFO

LEGENDA PROBLEMA

NEVE FRESCA | LASTRONI DA VENTO | STRATI DEBOLI PERSISTENTI | NEVE BAGNATA | SLITTAMENTO | CORNICI | NESSUN PROBLEMA VALANGHIVO EVIDENTE | NO_INFO

Bollettino realizzato su scala sinottica-regionale (standard EAWS). La sua valutazione non può escludere in alcun modo la necessità di una seria e capace valutazione locale del pericolo (singolo pendio) che può essere anche sensibilmente diverso. Le previsioni meteorologiche sono relative all'orario UTC (per l'Italia +1 in inverno e +2 in estate).

APPENNINO EMILIANO CENTRALE

PREVISIONE METEO

Quota		02/02/2026 h6:00	02/02/2026 h12:00	02/02/2026 h18:00
1000	Venti	01 Nodi da S-Ovest	01 Nodi da S-Ovest	02 Nodi da Sud
	Temperature	+00 °C	+03 °C	+02 °C
	Temp.percepita	0 °C	3 °C	2 °C
2000	Venti	04 Nodi da Ovest	05 Nodi da Ovest	08 Nodi da S-Ovest
	Temperature	-04 °C	-04 °C	-03 °C
	Temp.percepita	-7 °C	-8 °C	-8 °C
3000	Venti	07 nodi da Ovest	07 Nodi da Ovest	10 Nodi da Ovest
	Temperature	-09 °C	-09 °C	-06 °C
	Temp.percepita	-15 °C	-15 °C	-13 °C
Zero termico		0800-1000 m.	1500-1700 m.	1400-1600 m.
Fenomeno		—	—	—
Stato del cielo				

LEGENDA FENOMENI

— Assenza Fenomeni · Nebbia · Foschia · Pioggia debole · Pioggia moderata · Pioggia forte · Temporali

Nevicata debole · Nevicata moderata · Nevicata forte

STATO DEL CIELO

Sereno · Poco nuvoloso · Nuvoloso · Molto nuvoloso · Coperto

Parametri meteonivometrici registrati presso i campi di rilevamento il 01/02/2026.

Località	Comune	Quota (m.s.l.m.)	Altezza neve (cm)	Neve caduta nelle 24 ore (cm)	Temp. Min (°C)	Temp. Max (°C)	Condizioni del tempo
RIFUGIO CAVONE	Lizzano in Belvedere (BO)	1416	37	0	-4	-1	Assenza di precipitazioni
LAGO DELLA NINFA	Sestola (MO)	1550	28	0	-3	+2	Assenza di precipitazioni
PIANCAVALLARO	Riolunato (MO)	1840	89	0	N.P.	N.P.	Assenza di precipitazioni

(*) Rilievi fuori campo

L'INFORMAZIONE E' PREVENZIONE - LEGGI L'ATTUALE GRADO DI PERICOLO VALANGHE!

IL CAPO DEL CENTRO NAZIONALE METEOMONT
(Ten. Col. RFI Emanuela Gini)
FIRMA AUTOGRAFA OMESSA AI SENSI
DELL'ART.3 DEL D.LGS N.39/1993

Bollettino realizzato su scala sinottica-regionale (standard EAWS). La sua valutazione non può escludere in alcun modo la necessità di una seria e capace valutazione locale del pericolo (singolo pendio) che può essere anche sensibilmente diverso. Le previsioni meteorologiche sono relative all'orario UTC (per l'Italia +1 in inverno e +2 in estate).