MINISTERO DELLA DIFESA

meteomont Servizio Nazionale di previsione neve e valanghe

EAWS EUROPEAN AVALANCHE WARNING SERVICES

CARABINIERI

AERONAUTICA MILITARE SERVIZIO METEOROLOGICO

MAINARDE-ALTO MOLISE

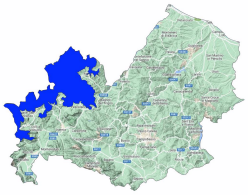

Bollettino Valanghe N. 282/2026 del 01/02/2026 ore 14.00
Validità 48 ore prossima emissione 02/02/2026

A cura del Servizio METEOMONT dell'ARMA dei CARABINIERI
In collaborazione con Servizio Meteorologico dell'Aeronautica militare

SITUAZIONE alle 14:00 del 01/02/2026

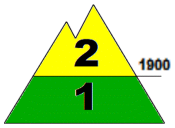

SITUAZIONE TIPO: passaggio da poca a molta neve.



SITUAZIONE TIPO: situazione primaverile.

	Nord	Sud
Quota neve (mslm)	*1200 - 1400*	*1200 - 1500*

	Neve al suolo	Neve Fresca	Quota (mslm)
Altezza Neve (cm)	*015*	*006*	*1500*
	002	*002*	*1220*

VALANGHE OSSERVATE: -.

PREVISIONI 02/02/2026

GRADO DI PERICOLO: MODERATO 2

SITUAZIONE TIPO: passaggio da poca a molta neve.

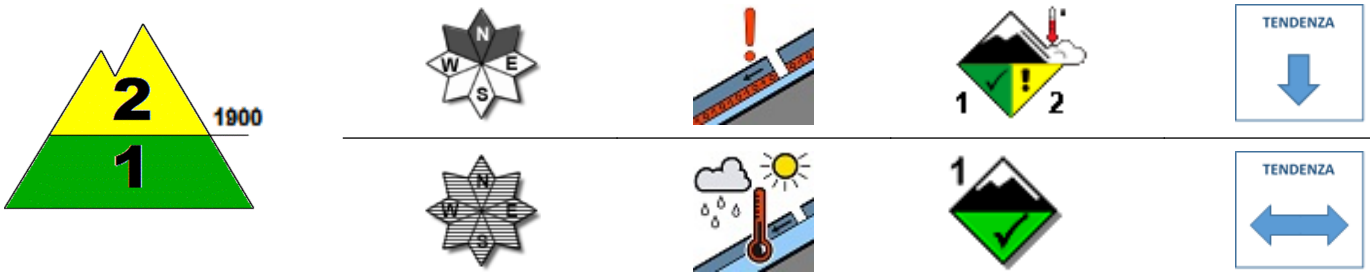

SITUAZIONE TIPO: situazione primaverile.

MANTO NEVOSO: La stabilità del manto nevoso è scarsa su pochi punti (aree) per versanti settentrionali al di sopra di 1900 mslm, possibili valanghe di dimensioni grandi.
La stabilità del manto nevoso è discreta su alcuni punti (aree) per isolati pendii al di sotto di 1900 mslm, possibili valanghe di dimensioni piccole.

AVVERTENZE

Viste le condizioni del manto nevoso, le attività al di fuori delle piste battute e segnalate richiedono buone capacità di valutazione del pericolo locale.

SCALA EUROPEA DEL GRADO DI PERICOLO VALANGHE

LEGENDA PROBLEMA

Bollettino realizzato su scala sinottica-regionale (standard EAWS). La sua valutazione non può escludere in alcun modo la necessità di una seria e capace valutazione locale del pericolo (singolo pendio) che può essere anche sensibilmente diverso. Le previsioni meteorologiche sono relative all'orario UTC (per l'Italia +1 in inverno e +2 in estate).

MINISTERO DELLA DIFESA

meteomont
Servizio Nazionale di previsione neve e valanghe

EAWS EUROPEAN AVALANCHE WARNING SERVICES

CARABINIERI

MAINARDE-ALTO MOLISE

PREVISIONE METEO

Quota		02/02/2026 h6:00	02/02/2026 h12:00	02/02/2026 h18:00
1000	Venti	03 Nodi da Ovest	01 Nodi da S-Ovest	01 Nodi da Ovest
	Temperature	-01 °C	+03 °C	+01 °C
	Temp.percepita	-3 °C	3 °C	1 °C
2000	Venti	09 nodi da N-Ovest	04 Nodi da Ovest	04 Nodi da Ovest
	Temperature	-02 °C	-02 °C	-01 °C
	Temp.percepita	-7 °C	-5 °C	-4 °C
3000	Venti	10 nodi da N-Ovest	11 Nodi da Ovest	11 Nodi da Ovest
	Temperature	-09 °C	-08 °C	-05 °C
	Temp.percepita	-16 °C	-15 °C	-12 °C
Zero termico		1100-1300 m.	1700-1900 m.	1700-1900 m.
Fenomeno		—	—	—
Stato del cielo				

LEGENDA FENOMENI

— Assenza Fenomeni · Nebbia · Foschia · Pioggia debole · Pioggia moderata · Pioggia forte · Temporali

Nevicata debole · Nevicata moderata · Nevicata forte

STATO DEL CIELO

Sereno · Poco nuvoloso · Nuvoloso · Molto nuvoloso · Coperto

Parametri meteonivometrici registrati presso i campi di rilevamento il 01/02/2026.

Località	Comune	Quota (m.s.l.m.)	Altezza neve (cm)	Neve caduta nelle 24 ore (cm)	Temp. Min (°C)	Temp. Max (°C)	Condizioni del tempo
PRATO GENTILE	Capracotta (IS)	1490	15	6	-1	+3	Assenza di precipitazioni
PESCOPENNATARO	Pescopennataro (IS)	1220	2	2	0	+8	Nebbia con cielo non visibile

(*) Rilievi fuori campo

L'INFORMAZIONE E' PREVENZIONE - LEGGI L'ATTUALE GRADO DI PERICOLO VALANGHE!

IL CAPO DEL CENTRO NAZIONALE METEOMONT
(Ten. Col. RFI Emanuela Gini)
FIRMA AUTOGRAFA OMESSA AI SENSI
DELL'ART.3 DEL D.LGS N.39/1993

Bollettino realizzato su scala sinottica-regionale (standard EAWS). La sua valutazione non può escludere in alcun modo la necessità di una seria e capace valutazione locale del pericolo (singolo pendio) che può essere anche sensibilmente diverso. Le previsioni meteorologiche sono relative all'orario UTC (per l'Italia +1 in inverno e +2 in estate).