MONTI SIMBRUINI E META

Bollettino Valanghe N. 267/2026 del 01/02/2026 ore 14.00
Validità 48 ore prossima emissione 02/02/2026

A cura del Servizio METEOMONT dell'ARMA dei CARABINIERI
In collaborazione con Servizio Meteorologico dell'Aeronautica militare

SITUAZIONE alle 14:00 del 01/02/2026

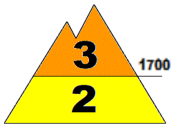

SITUAZIONE TIPO: neve a debole coesione e vento.



SITUAZIONE TIPO: passaggio da poca a molta neve.

Quota neve (mslm)	Nord	Sud
	1200 - 1400	1300 - 1500

Altezza Neve (cm)	Neve al suolo	Neve Fresca	Quota (mslm)
	074	000	1790
	036	000	1550

VALANGHE OSSERVATE: Nessuna valanga.

PREVISIONI 02/02/2026

GRADO DI PERICOLO: MARCATO 3

SITUAZIONE TIPO: neve a debole coesione e vento.

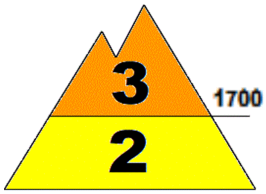

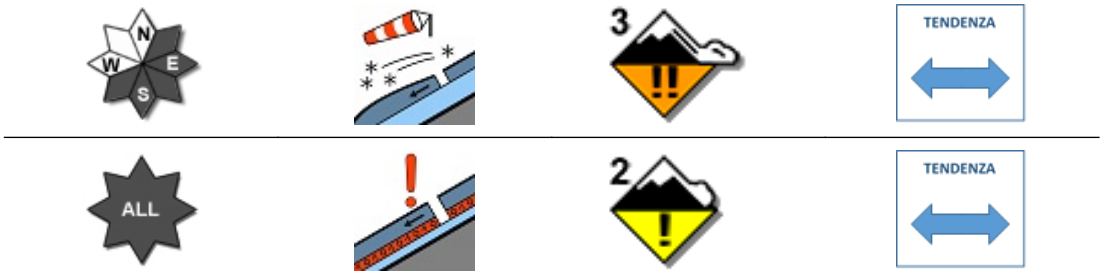

SITUAZIONE TIPO: passaggio da poca a molta neve.

MANTO NEVOSO: La stabilità del manto nevoso è scarsa su alcuni punti (aree) per versanti da nord est a sud ovest al di sopra di 1700 mslm, possibili valanghe di dimensioni medie.
La stabilità del manto nevoso è discreta su alcuni punti (aree) per tutte le esposizioni al di sotto di 1700 mslm, possibili valanghe di dimensioni medie.

AVVERTENZE

A seguito dell'attività eolica registrata sono da evitare le zone di accumulo, conche, canaloni, cambi di pendenza e pendii sotto vento in genere.

SCALA EUROPEA DEL GRADO DI PERICOLO VALANGHE

LEGENDA PROBLEMA

Bollettino realizzato su scala sinottica-regionale (standard EAWS). La sua valutazione non può escludere in alcun modo la necessità di una seria e capace valutazione locale del pericolo (singolo pendio) che può essere anche sensibilmente diverso. Le previsioni meteorologiche sono relative all'orario UTC (per l'Italia +1 in inverno e +2 in estate).

MONTI SIMBRUINI E META

PREVISIONE METEO

Quota		02/02/2026 h6:00	02/02/2026 h12:00	02/02/2026 h18:00
1000	Venti	01 Nodi da Nord	02 Nodi da Ovest	01 Nodi da Sud
	Temperature	+00 °C	+02 °C	+00 °C
	Temp.percepita	0 °C	2 °C	0 °C
2000	Venti	06 nodi da N-Ovest	05 nodi da Ovest	04 Nodi da Ovest
	Temperature	-02 °C	-02 °C	-02 °C
	Temp.percepita	-6 °C	-5 °C	-5 °C
3000	Venti	10 nodi da N-Ovest	11 Nodi da Ovest	09 nodi da Ovest
	Temperature	-09 °C	-08 °C	-06 °C
	Temp.percepita	-16 °C	-15 °C	-12 °C
Zero termico		1000-1200 m.	1500-1700 m.	1100-1300 m.
Fenomeno		—	—	—
Stato del cielo				

LEGENDA FENOMENI

— Assenza Fenomeni · Nebbia · Foschia · Pioggia debole · Pioggia moderata · Pioggia forte · Temporali

Nevicata debole · Nevicata moderata · Nevicata forte

STATO DEL CIELO

Sereno · Poco nuvoloso · Nuvoloso · Molto nuvoloso · Coperto

Parametri meteonivometrici registrati presso i campi di rilevamento il 01/02/2026.

Località	Comune	Quota (m.s.l.m.)	Altezza neve (cm)	Neve caduta nelle 24 ore (cm)	Temp. Min (°C)	Temp. Max (°C)	Condizioni del tempo
PRATI DI MEZZO	Picinisco (FR)	1430	17	0	-2	0	Assenza di precipitazioni
CAMPO CATINO	Guarcino (FR)	1790	72	0	-4	+1	Assenza di precipitazioni

(*) Rilievi fuori campo

L'INFORMAZIONE E' PREVENZIONE - LEGGI L'ATTUALE GRADO DI PERICOLO VALANGHE!

IL CAPO DEL CENTRO NAZIONALE METEOMONT
(Ten. Col. RFI Emanuela Gini)
FIRMA AUTOGRAFA OMESSA AI SENSI
DELL'ART.3 DEL D.LGS N.39/1993