Bulletin d'estimation du risque d'avalanche
(valable en dehors des pistes balisées et ouvertes)

MASSIF : Bauges

Rédigé le dimanche 1 février 2026 à 16h

Estimation des risques pour le : LUNDI 02 FÉVRIER

2

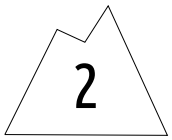

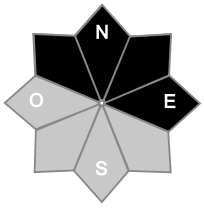

Indice de risque limité.

Départs spontanés : départs ponctuels dans la neige récente avec le réchauffement en surface

Déclenchements provoqués : plaques à vent sur un large secteur NO/N/NE/E

Indices de risque : 5 très fort - 4 fort - 3 marqué - 2 limité - 1 faible -- En noir : les pentes les plus dangereuses

Stabilité du manteau neigeux

Situation avalancheuse typique : neige ventée

Déclenchements provoqués :
* **Rares à quelques plaques à vent**, d'aspect friable. L'après-midi, de **nouvelles plaques** se forment dans la neige récente **sous le vent de sud-sud-ouest** (elles se rajoutent à celles déjà formées sous ce même vent vendredi). **Assez facile à déclencher.** Elles se situent essentiellement **au-dessus de 1800 m**, à proximité des crêtes. Taille 1 à 2 (petites à moyenne).

Observables : vaguelettes sur la neige de surface, fissures sous les skis, accumulations de neige récente.

Départs spontanés :
* Petites avalanches dans la neige récente, surtout dans les pentes raides, sous l'effet du couvert nuageux l'après-midi. Taille 1 (petite).

Qualité de la neige

Enneigement : Pour la saison, l'enneigement est correct.
On peut chausser les skis vers 900/1000 m. Pas de sous-couche sous 1500 m ou sur les crêtes, des cailloux sont cachés sous la neige récente.

Qualité de la neige ce lundi matin :
20/30 cm de neige récente, froide et légère reposant sur un fond dur. Dans les versants sud/sud-ouest la neige est plus dense et s'humidifie au soleil sous les éclaircies. Elle est parfois ventée vers les crêtes, surtout dans les versants N/NE.
En dessous de 1300 m, 10/20 cm de neige dense.

Aperçu météo pour le lundi 02 février

nuit	matin	après-midi	soir

Voile de plus en plus épais en journée. Le vent de sud-ouest se lève et les températures sont plus chaudes.

Pluie-Neige				
Iso 0 °C	1 500 m	2 000 m	2 400 m	2 400 m
Vent 1500 m	20 km/h	25 km/h	30 km/h	30 km/h
Vent 2000 m	30 km/h	40 km/h	50 km/h	50 km/h

Épaisseur de neige hors-piste

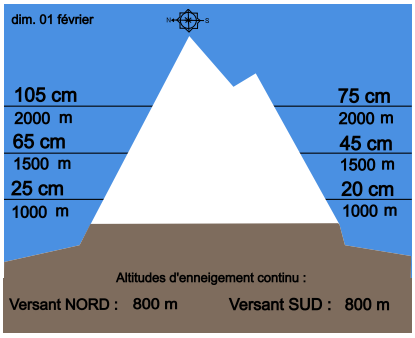

Précipitations à 1800 m

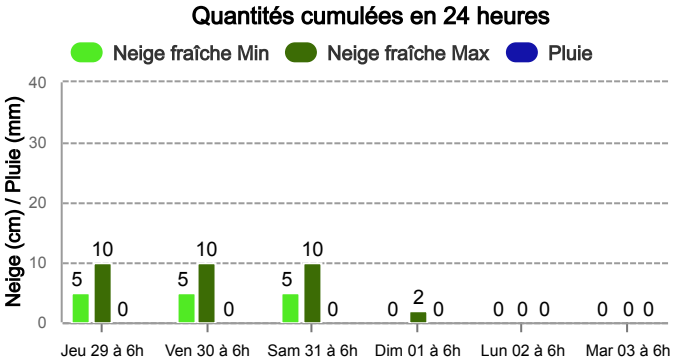

Tendance du mardi 03 février

3

Indice de risque marqué

Risque marqué, le vent de sud-ouest forcit dans la nuit, créant de nouvelles plaques à vent, même loin des crêtes.

Pour consulter la vigilance en cours, veuillez vous rendre sur le site https://vigilance.meteofrance.fr/fr

Météo-France - 73 avenue de Paris, 94165 Saint-Mandé cedex - Contact : contact@meteo.fr

Rédigé par Météo-France avec la contribution des observateurs du réseau nivo-météorologiques. Partenariat : ANMSM (Maires de Stations de Montagne), DSF (Domaines Skiables de France), ADSP (Directeurs de Pistes et de la Sécurité des Stations de Sports d'Hiver) et autres acteurs de la montagne.

Bulletin neige & avalanches par téléphone au
0 892 68 10 20 Service 0,35 € / min + prix appel

RÉPUBLIQUE FRANÇAISE
Liberté Égalité Fraternité

METEO FRANCE
À VOS CÔTÉS, DANS UN CLIMAT QUI CHANGE

Bulletin d'estimation du risque d'avalanche
(valable en dehors des pistes balisées et ouvertes)

MASSIF : Bauges

Rédigé le dimanche 1 février 2026 à 16h

Conditions nivo-météo des 7 derniers jours

	lun. 26/01				mar. 27/01				mer. 28/01				jeu. 29/01				ven. 30/01				sam. 31/01				dim. 01/02			
	03h	09h	15h	21h	03h	09h	15h	21h	03h	09h	15h	21h	03h	09h	15h	21h	03h	09h	15h	21h	03h	09h	15h	21h	03h	09h	15h	21h
Météo																												
Vent (km/h)	20	20	10	15	30	40	60	35	35	15	15	20	20	10	10	15	25	25	20	25	20	10	10	10	15	10	20	30
à 2000m																												
Vent (km/h)	10	10	5	10	20	30	35	15	10	10	10	10	15	5	5	10	20	20	15	20	15	5	5	5	10	5	10	15
à 1500m																												

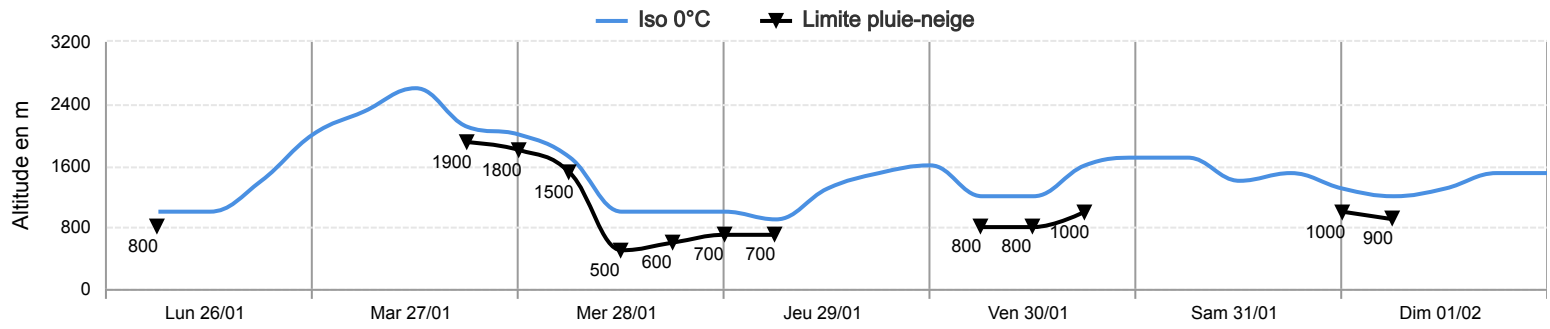

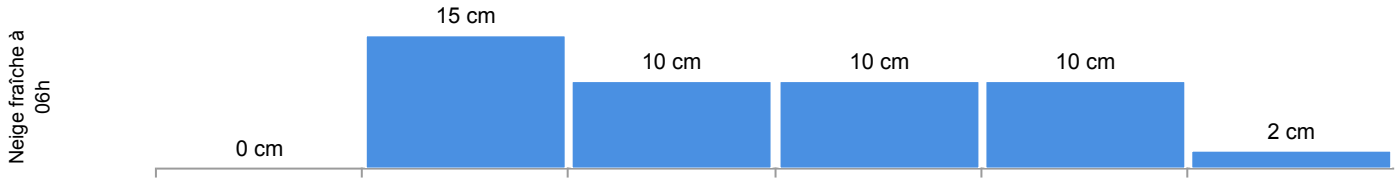

Risque d'avalanche	lun. 26/01	mar. 27/01	mer. 28/01	jeu. 29/01	ven. 30/01	sam. 31/01	dim. 01/02
	2	3	3	2	2	2	2

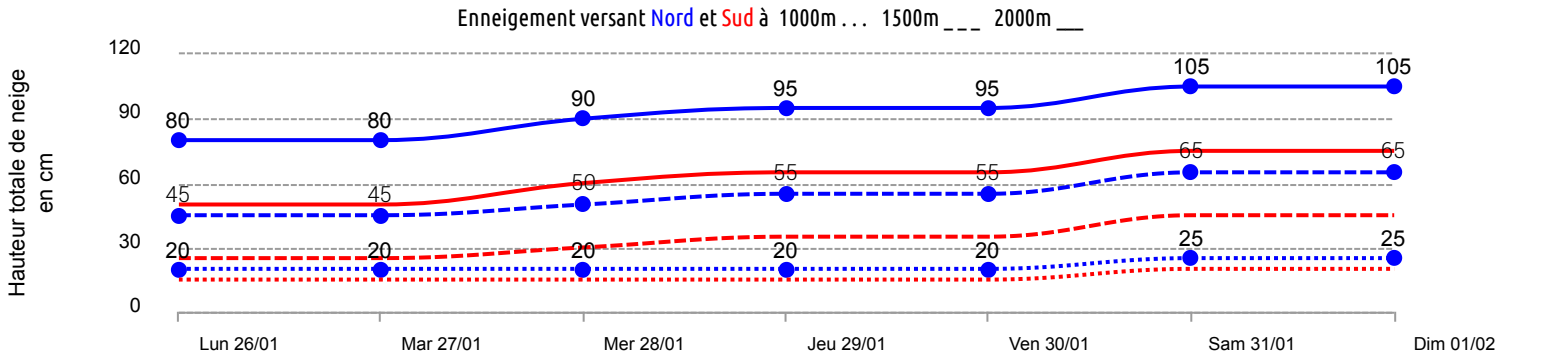

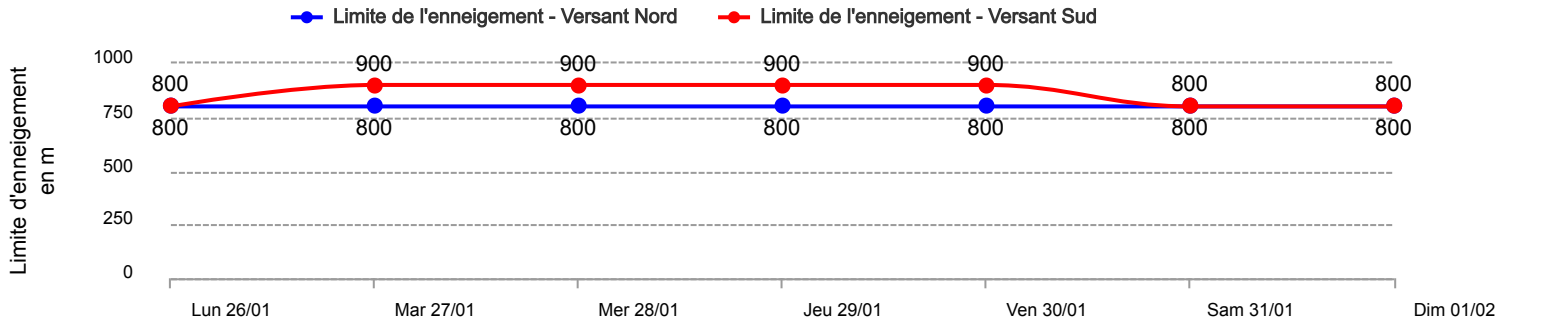

Pour consulter la vigilance en cours, veuillez vous rendre sur le site https://vigilance.meteofrance.fr/fr

Météo-France - 73 avenue de Paris, 94165 Saint-Mandé cedex - Contact : contact@meteo.fr

Bulletin neige & avalanches par téléphone au **0 892 68 10 20** Service 0,35 € / min + prix appel

Rédigé par Météo-France avec la contribution des observateurs du réseau nivo-météorologiques. Partenariat : ANMSM (Maires de Stations de Montagne), DSF (Domaines Skiables de France), ADSP (Directeurs de Pistes et de la Sécurité des Stations de Sports d'Hiver) et autres acteurs de la montagne.