# Bulletin d'estimation du risque d'avalanche

(valable en dehors des pistes balisées et ouvertes)

# MASSIF : Belledonne

Rédigé le dimanche 1 février 2026 à 16h

## Estimation des risques pour le : LUNDI 02 FÉVRIER

**NOUVELLES INSTABILITÉS EN FORMATION DANS LES VERSANTS FROIDS, AVEC LOCALEMENT DES COUCHES FRAGILES ENFOUIES.**

3

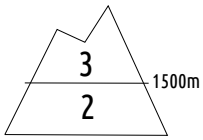


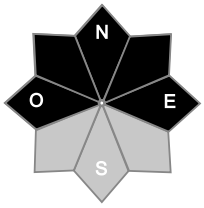


vent de Sud

Au-dessus de 1500m indice de risque marqué, plus bas indice limité.

**Départs spontanés :** Rares avalanches humides en pentes "réchauffées".

**Déclenchements provoqués :** Nouvelles instabilités sous le vent de Sud dans les versants froids. Très localement, possibilité de grande avalanche avec déclenchement en cascade.

Indices de risque : 5 très fort - 4 fort - 3 marqué - 2 limité - 1 faible -- En noir : les pentes les plus dangereuses

## Stabilité du manteau neigeux

**Situation avalancheuse typique :** neige ventée couche fragile persistante

**Déclenchements provoqués :** Risque devenant plus marqué au fil de la journée de lundi dans les versants froids d'un large Nord. De nouvelles instabilités vont se former dans la neige récente restée légère, avec le vent de Sud qui se renforce en cours de journée. D'abord assez locales et souvent peu épaisses en première partie de journée, elles se font de plus en plus nombreuses au fil des heures et notamment dans l'après-midi. Ces nouvelles plaques, souvent réactives et faciles à déclencher, sont situées dans les zones d'accumulation par le vent, à proximité des crêtes dans un premier temps, puis le risque augmente également dans les bas de pentes et plus loin des crêtes au fur et à mesure que le vent forcit. De plus, très ponctuellement au-dessus de 1800m environ, le départ d'une avalanche de surface pourrait également déclencher en cascade une avalanche de plus grande ampleur, en venant solliciter des couches fragiles persistantes enfouies dans le manteau. Ces couches fragiles pourraient être davantage présentes sur l'Est du massif, côté Maurienne, mais très localement on a pu également en observer plus à l'Ouest...
Sous 1400/1600 m environ, le risque devrait rester plus limité, la neige récente s'étant davantage alourdie/humidifiée.

**Départs spontanés :** En journée de lundi, de rares avalanches de neige humide de taille 1 à 2 (petites à moyennes) ne sont pas exclues dans la neige récente qui s'humidifie, notamment dans les pentes raides qui seront exposées au soleil et près des rochers. Très ponctuellement, un départ spontané linéaire (en plaque) atteignant la taille 3 ne peut être exclu.

## Qualité de la neige

**Qualification de l'enneigement :** L'enneigement s'est bien amélioré cette semaine et est désormais typique d'une fin janvier sur le massif (quoi que légèrement déficitaire à basse altitude). Les crêtes sont toutefois assez peu enneigées ainsi que les pentes plein Sud, les chemins sous les sapins...

**Limites skiables** : à partir de 1000/1300 m.

**Qualité de la neige lundi :** Neige récente en cours de tassement, généralement encore assez légère, et parfois travaillée par le vent à l'abord des crêtes. Sous 1400/1600 m et dans les versants ensoleillés, la neige s'est davantage alourdie, et peut être parfois croûtée. En journée, outre l'humidification qui peut reprendre au soleil, la neige récente subit de plus en plus les effets du vent de Sud, travaillée puis soufflée/arrachée vers les crêtes, dont certaines pourraient redevenir dégarnies. En toute fin de journée/soirée, quelques chutes de neige remontant du Sud peuvent commencer à déposer une fine couche de fraîche (de manière très irrégulière à cause du vent fort).

## Aperçu météo pour le lundi 02 février

| nuit | matin | après-midi | soir |
|---|---|---|---|
| | | | |

Ciel devenant voilé puis très nuageux dans l'après-midi. Qq chutes de neige à partir de la fin de journée/soirée. Net renforcement du vent de Sud.

| Pluie-Neige | | | | 1 800 m |
|---|---|---|---|---|
| Iso 0 °C | 1 600 m | 2 200 m | 2 400 m | 2 200 m |
| Vent 2000 m | 15 km/h | 20 km/h | 60 km/h | 100 km/h |
| Vent 3000 m | 30 km/h | 40 km/h | 70 km/h | 110 km/h |

## Épaisseur de neige hors-piste

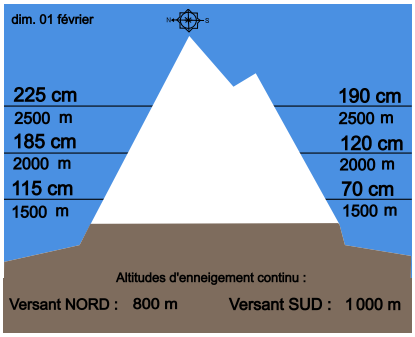


## Précipitations à 1800 m

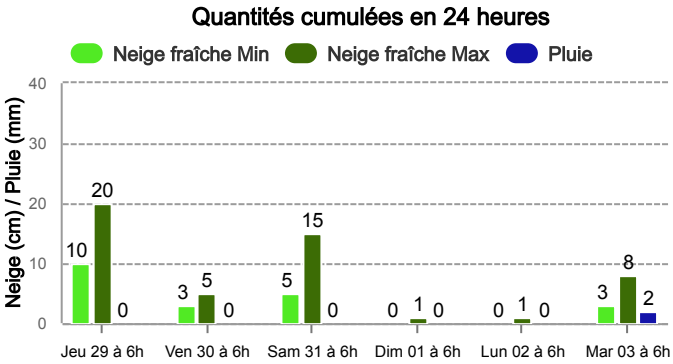


## Tendance du mardi 03 février

3 **Indice de risque marqué**

Mardi, risque restant marqué sur le massif, en augmentation par rapport à la veille. Le vent de Sud et les chutes de neige auront formé et formeront de nombreuses instabilités réactives, qui pourront elles-même plus facilement solliciter les quelques sous-couches fragiles enfouies par endroits dans le manteau neigeux.

Pour consulter la vigilance en cours, veuillez vous rendre sur le site https://vigilance.meteofrance.fr/fr

Météo-France - 73 avenue de Paris, 94165 Saint-Mandé cedex - Contact : contact@meteo.fr

Rédigé par Météo-France avec la contribution des observateurs du réseau nivo-météorologiques. Partenariat : ANMSM (Maires de Stations de Montagne), DSF (Domaines Skiables de France), ADSP (Directeurs de Pistes et de la Sécurité des Stations de Sports d'Hiver) et autres acteurs de la montagne.

Bulletin neige & avalanches par téléphone au 0 892 68 10 20 Service 0,35 € / min + prix appel

RÉPUBLIQUE FRANÇAISE
*Liberté Égalité Fraternité*

METEO FRANCE
À VOS CÔTÉS, DANS UN CLIMAT QUI CHANGE

# Bulletin d'estimation du risque d'avalanche

## (valable en dehors des pistes balisées et ouvertes)

# MASSIF : Belledonne

Rédigé le dimanche 1 février 2026 à 16h

## Conditions nivo-météo des 7 derniers jours

| | lun. 26/01 | | | | mar. 27/01 | | | | mer. 28/01 | | | | jeu. 29/01 | | | | ven. 30/01 | | | | sam. 31/01 | | | | dim. 01/02 | | | |
|---|---|---|---|---|---|---|---|---|---|---|---|---|---|---|---|---|---|---|---|---|---|---|---|---|---|---|---|---|
| | 03h | 09h | 15h | 21h | 03h | 09h | 15h | 21h | 03h | 09h | 15h | 21h | 03h | 09h | 15h | 21h | 03h | 09h | 15h | 21h | 03h | 09h | 15h | 21h | 03h | 09h | 15h | 21h |
| Météo | | | | | | | | | | | | | | | | | | | | | | | | | | | | |
| Vent (km/h) | 30 | 45 | 45 | 25 | 60 | 85 | 100 | 95 | 15 | 15 | 35 | 45 | 35 | 25 | 25 | 30 | 40 | 35 | 25 | 20 | 25 | 15 | 15 | 20 | 20 | 20 | 30 | 25 |
| à 3000m | ↓ | ↓ | ↓ | → | ↗ | ↑ | ↑ | ↑ | ↑ | ↓ | ↘ | ↓ | ↓ | ↘ | ↘ | ↘ | → | ↘ | ↘ | ↗ | ↗ | ↗ | ↗ | → | ↓ | ↘ | ↘ | → |
| Vent (km/h) | 15 | 35 | 35 | 15 | 45 | 80 | 90 | 90 | 5 | 5 | 10 | 15 | 10 | 5 | 5 | 5 | 15 | 20 | 15 | 15 | 15 | 10 | 10 | 10 | 10 | 10 | 15 | 15 |
| à 2000m | → | ↓ | ↓ | ↖ | ↑ | ↑ | ↖ | ↑ | ↖ | ↘ | ↓ | ↓ | ↓ | ↓ | ↓ | ↖ | ↗ | ↗ | ↗ | ↗ | ↗ | ↗ | ↗ | → | ↙ | ↓ | → | ↗ |

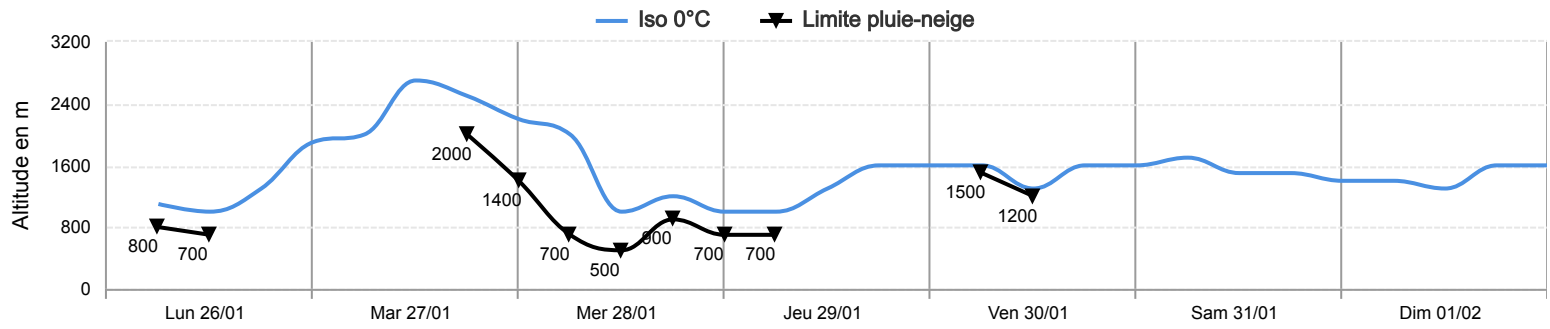


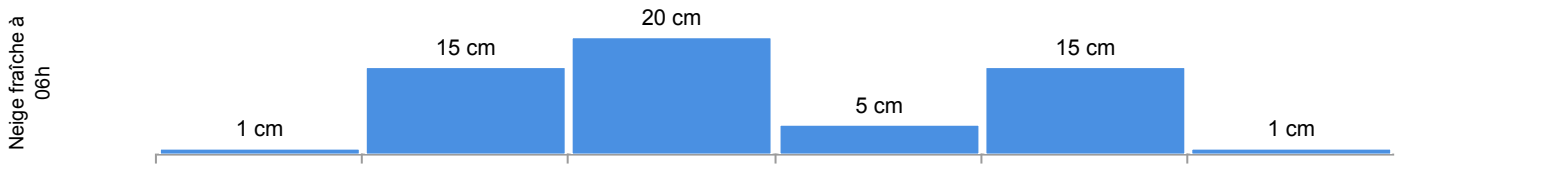


| Risque d'avalanche | lun. 26/01 | mar. 27/01 | mer. 28/01 | jeu. 29/01 | ven. 30/01 | sam. 31/01 | dim. 01/02 |
|---|---|---|---|---|---|---|---|
| | 3 | 3 | 3 | 3 | 3 | 3 | 3 |

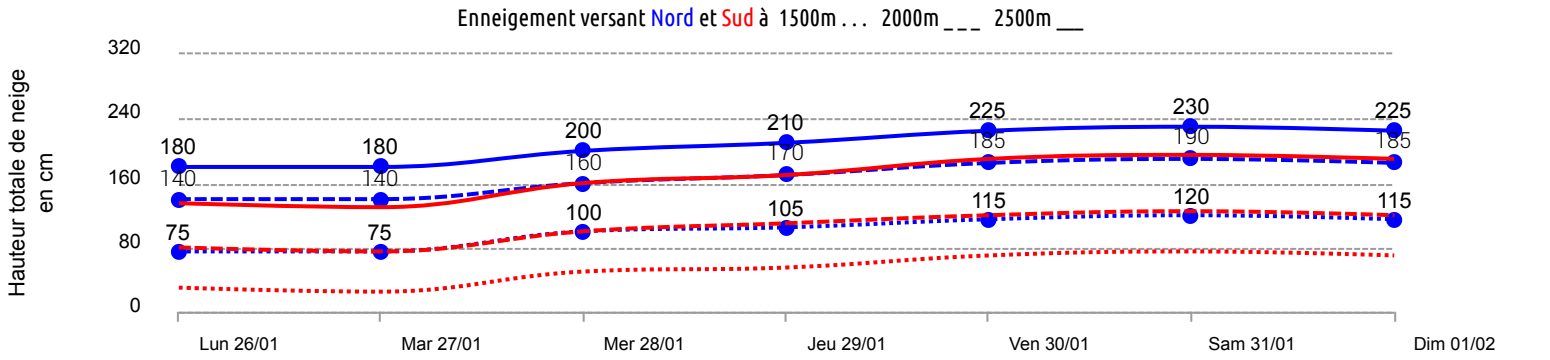


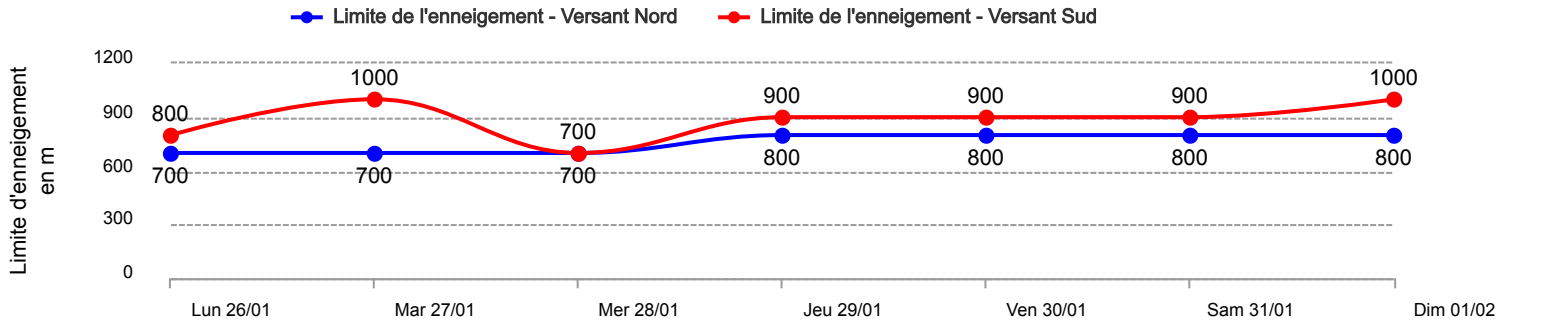


Pour consulter la vigilance en cours, veuillez vous rendre sur le site https://vigilance.meteofrance.fr/fr


**Météo-France - 73 avenue de Paris, 94165 Saint-Mandé cedex - Contact : contact@meteo.fr**



Rédigé par Météo-France avec la contribution des observateurs du réseau nivo-météorologiques. Partenariat : ANMSM (Maires de Stations de Montagne), DSF (Domaines Skiables de France), ADSP (Directeurs de Pistes et de la Sécurité des Stations de Sports d'Hiver) et autres acteurs de la montagne.



Bulletin neige & avalanches par téléphone au
0 892 68 10 20 Service 0,35 € / min + prix appel