Bulletin d'estimation du risque d'avalanche

(valable en dehors des pistes balisées et ouvertes)

MASSIF : Capcir Puymorens

Rédigé le dimanche 1 février 2026 à 16h

Estimation des risques pour le : LUNDI 02 FÉVRIER

MANTEAU NEIGEUX ENCORE PEU STABILISÉ ET HUMIDIFICATION JUSQU'EN SOIRÉE SOUS 2000/2200 M

3

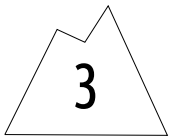

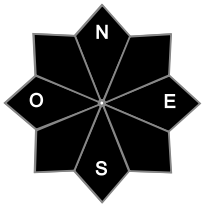

Indice de risque marqué.

Départs spontanés : Départs linéaires d'avalanches par humidification ou par surcharge due au vent

Déclenchements provoqués : Nombreuses instabilités déjà présentes et encore en formation dans la neige récente et ventée

Indices de risque : 5 très fort - 4 fort - 3 marqué - 2 limité - 1 faible -- En noir : les pentes les plus dangereuses

Stabilité du manteau neigeux

Situation avalancheuse typique : neige ventée neige humide

Déclenchements provoqués :
Avalanches de plaques possibles dans de nombreuses orientations, mais préférentiellement dans un large secteur nord à sud-est. Elles sont faciles à déclencher et peuvent générer des avalanches de taille moyenne à plus rarement grande (taille 2 à 3).
De nouvelles plaques continuent à se former lundi avec le vent de sud-ouest et s'ajoutent aux instabilités des chutes de neige ventées des derniers jours qui se trouve parfois loin des crêtes et dans des orientations variées. Une grande avalanche est également possible en cas de sollicitation d'une couche fragile persistante plus profondément enfouie, notamment dans les versants ombragés d'altitude (ouest/nord/est).

Départs spontanés :
Avalanche de taille petite à moyenne, rarement grande.
En journée, sous 2000/2100 m en toutes orientations, des avalanches spontanées peuvent entrainer l'ensemble de la neige récente, parfois même jusqu'au sol, dans les pentes raides en cours d'humidification. Départs ponctuels ou linéaires emportant les plaques formées ces derniers jours. L'humidification pourra s'accélérer en fin de journée sous la pluie jusqu'à 2000m.
Plus haut, des avalanches sont possibles dans les pentes raides d'un large secteur nord, par surcharge due au transport de neige par le vent de sud.

Qualité de la neige

Enneigement :
Enneigement excédentaire pour la saison à toutes altitudes, avec des cumuls récents importants et de nouveau apport de neige ce week-end jusqu'à basse altitude. On peut envisager de chausser les skis dès les premières pentes, avec une progression confortable dès 1300/1400 m avec des quantités de neige importantes.

État de la neige :
Lundi matin, la neige sera le plus souvent regelée en dessous de 1800/2000 m. En journée, la neige va progressivement s'humidifier, jusqu'à 2200 m en sud, et plutôt vers 2000 m en nord. L'humidification se fera en profondeur sous 2000 m avec plusieurs dizaines de cm de neige lourde devenant collante. Les précipitations de la fin de journée faciliteront également l'humidification dans ces zones.
Plus haut, elle restera sèche et on pourra trouver des combes poudreuses en altitude à l'abri du vent mais la neige sera souvent compacté par le vent avec une couverture très hétérogène proche des crêtes et sommets

Aperçu météo pour le lundi 02 février

Ciel nuageux et fort vent de sud/sud-ouest qui se renforce en journée. Limite pluie-neige haute en journée puis en baisse à partir de la soirée.

	nuit	matin	après-midi	soir
Pluie-Neige		2 000 m	1 900 m	1 700 m
Iso 0 °C	2 500 m	2 800 m	2 600 m	2 200 m
Vent 2000 m	20 km/h	50 km/h	75 km/h	45 km/h
Vent 3000 m	60 km/h	80 km/h	100 km/h	65 km/h

Épaisseur de neige hors-piste

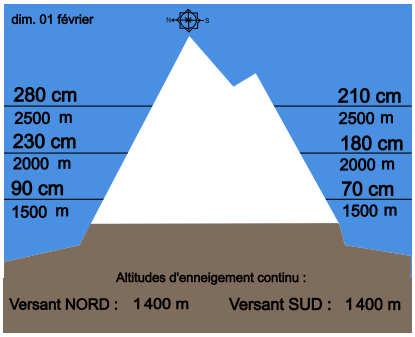

Précipitations à 1800 m

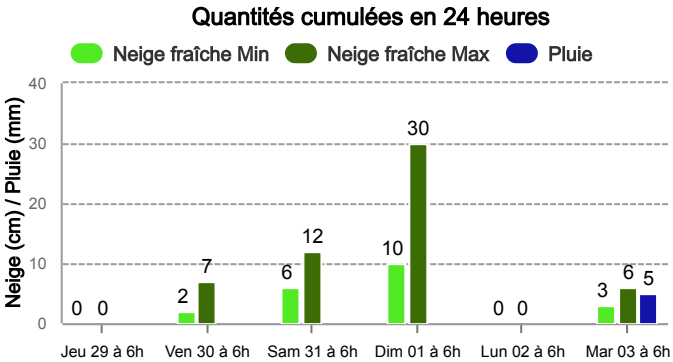

Tendance du mardi 03 février

3

Indice de risque marqué

Tendance à la stabilisation progressive des chutes de neige récente.

Pour consulter la vigilance en cours, veuillez vous rendre sur le site https://vigilance.meteofrance.fr/fr

Météo-France - 73 avenue de Paris, 94165 Saint-Mandé cedex - Contact : contact@meteo.fr

Rédigé par Météo-France avec la contribution des observateurs du réseau nivo-météorologiques. Partenariat : ANMSM (Maires de Stations de Montagne), DSF (Domaines Skiables de France), ADSP (Directeurs de Pistes et de la Sécurité des Stations de Sports d'Hiver) et autres acteurs de la montagne.

Bulletin neige & avalanches par téléphone au

0 892 68 10 20 Service 0,35 € / min + prix appel

RÉPUBLIQUE FRANÇAISE
Liberté Égalité Fraternité

METEO FRANCE
À VOS CÔTÉS, DANS UN CLIMAT QUI CHANGE

Bulletin d'estimation du risque d'avalanche

(valable en dehors des pistes balisées et ouvertes)

MASSIF : Capcir Puymorens

Rédigé le dimanche 1 février 2026 à 16h

Conditions nivo-météo des 7 derniers jours

	lun. 26/01				mar. 27/01				mer. 28/01				jeu. 29/01				ven. 30/01				sam. 31/01				dim. 01/02			
	03h	09h	15h	21h	03h	09h	15h	21h	03h	09h	15h	21h	03h	09h	15h	21h	03h	09h	15h	21h	03h	09h	15h	21h	03h	09h	15h	21h
Météo																												
Vent (km/h)	85	75	50	30	35	65	70	55	40	50	50	55	50	50	55	75	80	70	60	40	55	85	80	70	55	35	35	30
à 3000m																												
Vent (km/h)	65	65	35	20	20	50	55	40	25	35	35	35	30	30	40	50	55	45	45	25	35	65	65	50	35	25	20	15
à 2000m																												

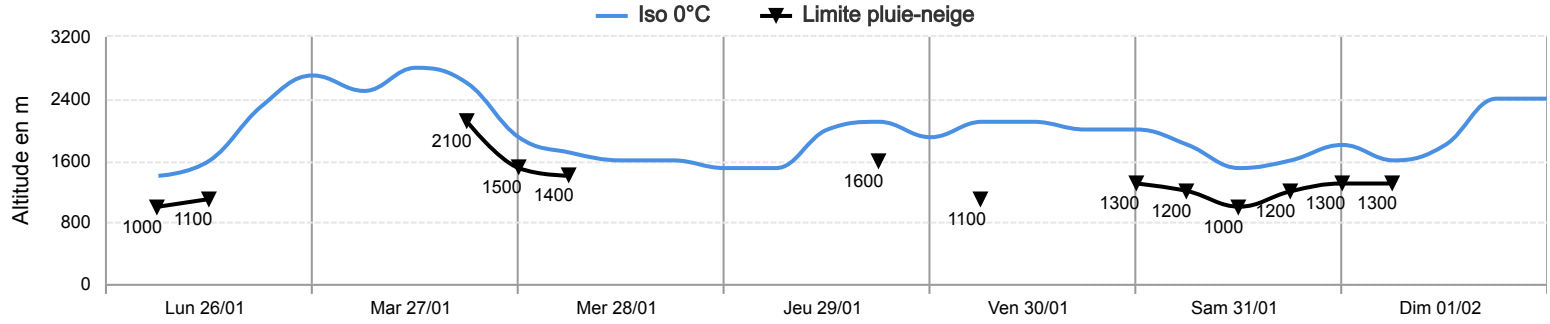

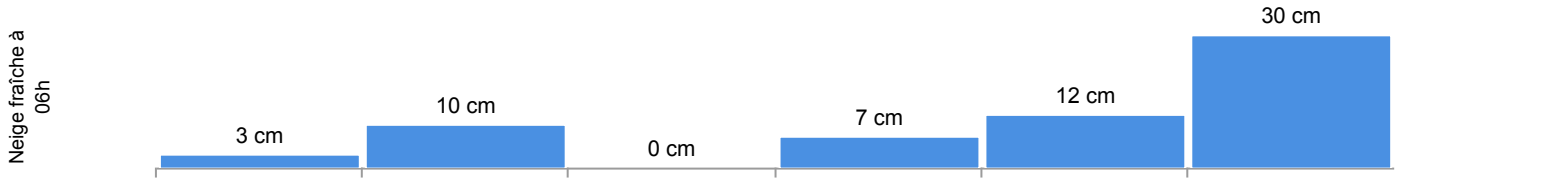

Risque d'avalanche	lun. 26/01	mar. 27/01	mer. 28/01	jeu. 29/01	ven. 30/01	sam. 31/01	dim. 01/02
	4	4	3	3	3	3	4

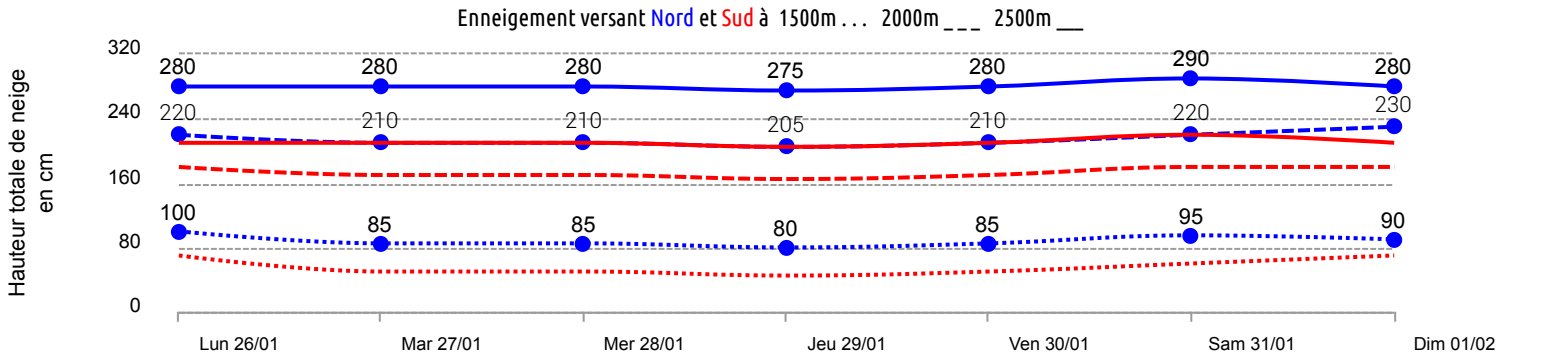

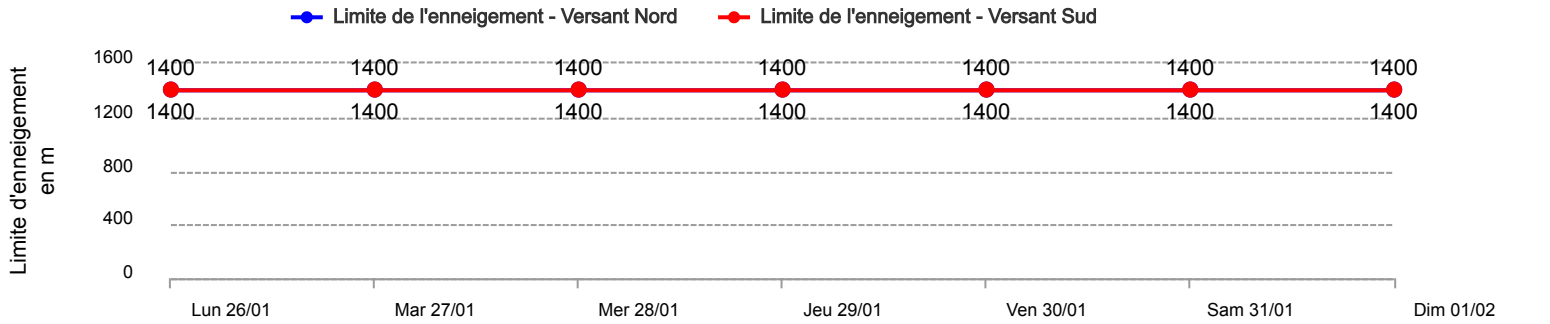

Pour consulter la vigilance en cours, veuillez vous rendre sur le site https://vigilance.meteofrance.fr/fr

Météo-France - 73 avenue de Paris, 94165 Saint-Mandé cedex - Contact : contact@meteo.fr

Rédigé par Météo-France avec la contribution des observateurs du réseau nivo-météorologiques. Partenariat : ANMSM (Maires de Stations de Montagne), DSF (Domaines Skiables de France), ADSP (Directeurs de Pistes et de la Sécurité des Stations de Sports d'Hiver) et autres acteurs de la montagne.

Bulletin neige & avalanches par téléphone au

0 892 68 10 20 Service 0,35 € / min + prix appel