Bulletin d'estimation du risque d'avalanche

(valable en dehors des pistes balisées et ouvertes)

MASSIF : Cerdagne Canigou

Rédigé le dimanche 1 février 2026 à 16h

Estimation des risques pour le : LUNDI 02 FÉVRIER

MANTEAU NEIGEUX ENCORE INSTABLE : NEIGE TRAVAILLÉE PAR LE VENT ET HUMIDIFICATION QUI PROGRESSE

3

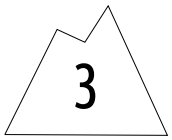

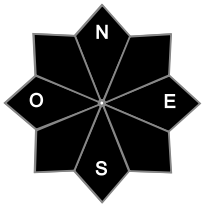

Indice de risque marqué.

Départs spontanés : Départ linéaires possibles avec l'humidification qui remonte en altitude et le transport de neige par le vent

Déclenchements provoqués : Instabilités dans la neige récente transportée par le vent

Indices de risque : 5 très fort - 4 fort - 3 marqué - 2 limité - 1 faible -- En noir : les pentes les plus dangereuses

Stabilité du manteau neigeux

Situation avalancheuse typique : neige ventée neige humide

Déclenchements provoqués :
Avalanches de plaques possibles, plus vraisemblablement dans un large secteur nord à sud-est, déclenchables au passage d'un skieur. Ces avalanches peuvent être principalement de taille petite à moyenne, voire grande dans un secteur de fortes accumulations et en altitude.
Ces instabilités se sont formées avec le transport des derniers jours, qui se poursuit avec le fort vent de sud-ouest de lundi, s'accompagnant de quelques précipitations en fin de journée. Les accumulations sont parfois loin des crêtes et dans des orientations variées et peuvent reposer sur une neige plus meuble faisant office de couche fragile.

Départs spontanés :
Avalanche de taille petite à moyenne, plus rarement grande.
En journée, sous 2000 m, des avalanches spontanées peuvent entrainer l'ensemble de la neige récente, parfois même jusqu'au sol, dans les pentes raides en cours d'humidification. Départs ponctuels ou linéaires emportant les plaques formées ces derniers jours. L'humidification pourra s'accélérer en fin de journée avec l'arrivée des précipitations. Plus haut, des départs spontanés linéaires des structures de plaques décrites plus hauts sont possibles par surcharge due au transport de neige par le vent ou par rupture de corniches.

Qualité de la neige

Enneigement :
Enneigement excédentaire pour la saison à toutes altitudes, avec quelques faibles apports de neige ce week-end jusqu'à basse altitude. On peut envisager de chausser les skis dès 1200 m en nord puis avec une progression confortable dès 1300/1400 m avec des quantités de neige devenant plus importantes.

État de la neige :
Lundi matin, la neige sera le plus souvent bien regelée en dessous de 1800/2000 m. En journée, la neige va progressivement s'humidifier, jusqu'à 2200 m en sud, et plutôt vers 2000 m en nord. L'humidification se fera en profondeur sous 2000 m avec plusieurs dizaines de cm de neige lourde devenant collante. Les précipitations proche de la frontière en journée faciliteront également l'humidification dans ces zones.
Plus haut, elle restera sèche mais la neige sera souvent compacté par le vent avec une couverture très hétérogène proche des crêtes et sommets

Aperçu météo pour le lundi 02 février

nuit	matin	après-midi	soir

Vent de sud-ouest fort en journée et précipitations principalement proche de la frontière espagnole avec de la douceur.

Pluie-Neige			2 000 m	1 700 m
Iso 0 °C	2 600 m	2 800 m	2 700 m	2 200 m
Vent 2000 m	↗ 35 km/h	↗ 60 km/h	↗ 80 km/h	↗ 55 km/h
Vent 3000 m	↗ 60 km/h	↗ 80 km/h	↗ 95 km/h	↗ 75 km/h

Épaisseur de neige hors-piste

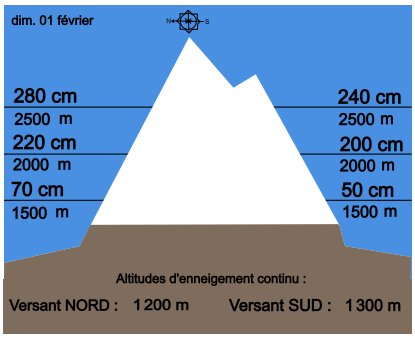

Précipitations à 1800 m

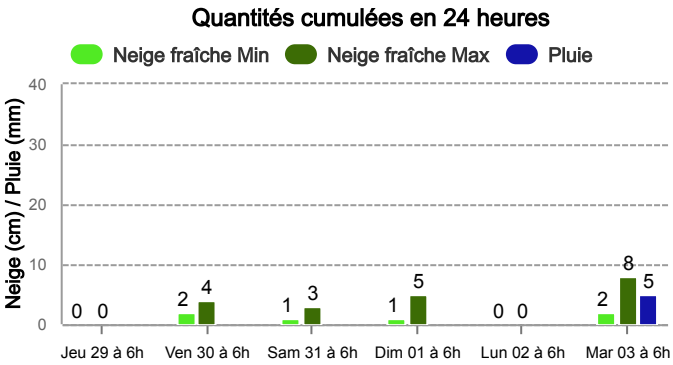

Tendance du mardi 03 février

3

Indice de risque marqué

Stationnaire, surtout en altitude. La stabilisation du manteau neigeux se poursuit.

Pour consulter la vigilance en cours, veuillez vous rendre sur le site https://vigilance.meteofrance.fr/fr

Météo-France - 73 avenue de Paris, 94165 Saint-Mandé cedex - Contact : contact@meteo.fr

Rédigé par Météo-France avec la contribution des observateurs du réseau nivo-météorologiques. Partenariat : ANMSM (Maires de Stations de Montagne), DSF (Domaines Skiables de France), ADSP (Directeurs de Pistes et de la Sécurité des Stations de Sports d'Hiver) et autres acteurs de la montagne.

Bulletin neige & avalanches par téléphone au 0 892 68 10 20 Service 0,35 € / min + prix appel

RÉPUBLIQUE FRANÇAISE
Liberté Égalité Fraternité

METEO FRANCE
À VOS CÔTÉS, DANS UN CLIMAT QUI CHANGE

Bulletin d'estimation du risque d'avalanche

(valable en dehors des pistes balisées et ouvertes)

MASSIF : Cerdagne Canigou

Rédigé le dimanche 1 février 2026 à 16h

Conditions nivo-météo des 7 derniers jours

	lun. 26/01				mar. 27/01				mer. 28/01				jeu. 29/01				ven. 30/01				sam. 31/01				dim. 01/02			
	03h	09h	15h	21h	03h	09h	15h	21h	03h	09h	15h	21h	03h	09h	15h	21h	03h	09h	15h	21h	03h	09h	15h	21h	03h	09h	15h	21h
Météo																												
Vent (km/h)	90	85	45	35	40	85	75	50	40	50	50	55	50	50	55	75	80	70	60	40	60	75	80	75	65	30	30	40
à 3000m																												
Vent (km/h)	60	60	25	20	20	55	50	30	25	35	35	35	30	30	40	50	55	45	45	25	30	60	55	55	40	15	15	15
à 2000m																												

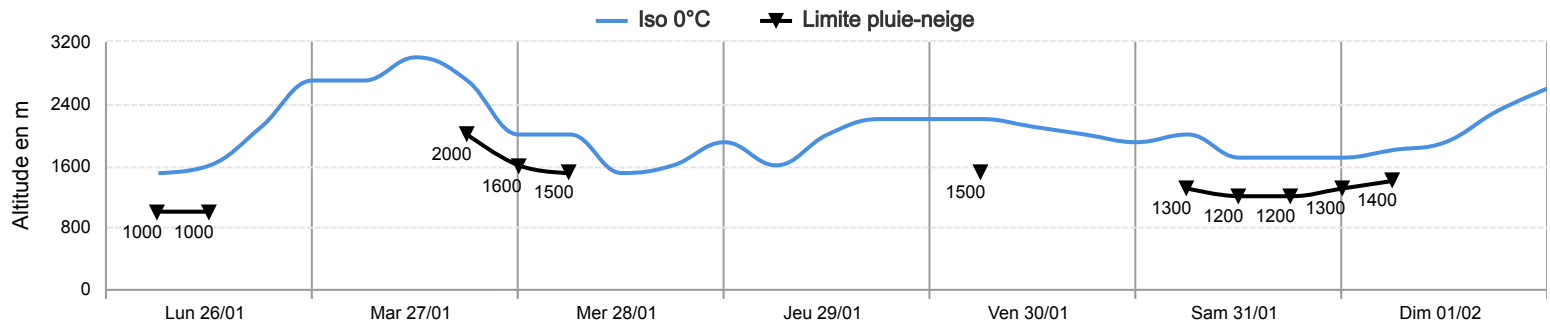

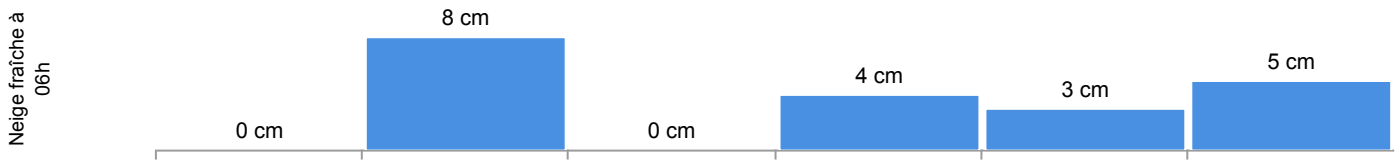

Risque d'avalanche	lun. 26/01	mar. 27/01	mer. 28/01	jeu. 29/01	ven. 30/01	sam. 31/01	dim. 01/02
	4	3	3	3	3	3	3

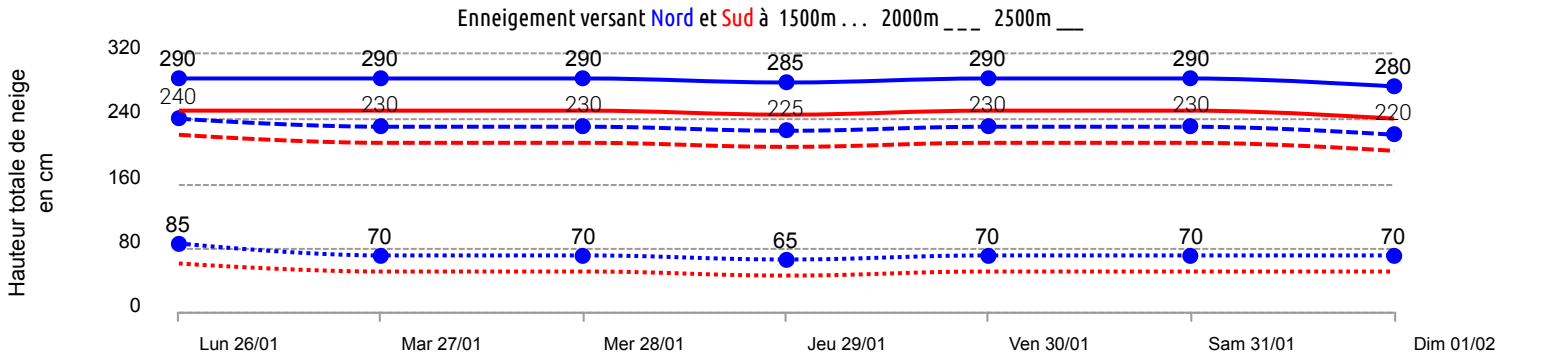

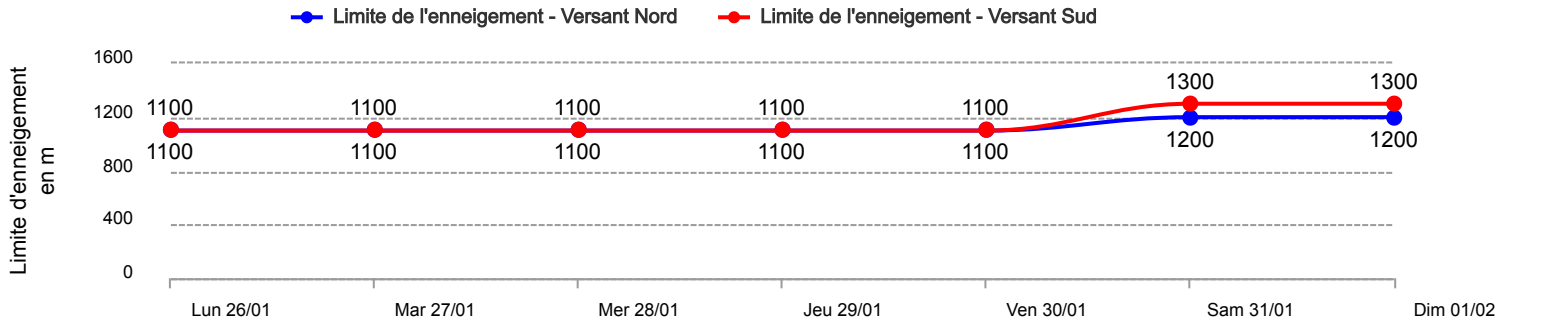

Pour consulter la vigilance en cours, veuillez vous rendre sur le site https://vigilance.meteofrance.fr/fr

Météo-France - 73 avenue de Paris, 94165 Saint-Mandé cedex - Contact : contact@meteo.fr

Rédigé par Météo-France avec la contribution des observateurs du réseau nivo-météorologiques. Partenariat : ANMSM (Maires de Stations de Montagne), DSF (Domaines Skiables de France), ADSP (Directeurs de Pistes et de la Sécurité des Stations de Sports d'Hiver) et autres acteurs de la montagne.

Bulletin neige & avalanches par téléphone au

0 892 68 10 20 Service 0,35 € / min + prix appel