Bulletin d'estimation du risque d'avalanche

(valable en dehors des pistes balisées et ouvertes)

MASSIF : Couserans

Rédigé le dimanche 1 février 2026 à 16h

Estimation des risques pour le : LUNDI 02 FÉVRIER

MANTEAU NEIGEUX ENCORE PEU STABILISÉ : INSTABILITÉ DANS LA NEIGE RÉCENTE VENTÉE ET HUMIDIFICATION QUI PROGRESSE

3

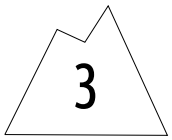

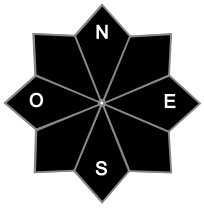

Indice de risque marqué.

Départs spontanés : Départs linéaires d'avalanches par humidification ou par surcharge due au vent

Déclenchements provoqués : Instabilités toujours présentes et en formation dans la neige récente ventée

Indices de risque : 5 très fort - 4 fort - 3 marqué - 2 limité - 1 faible -- En noir : les pentes les plus dangereuses

Stabilité du manteau neigeux

Situation avalancheuse typique : neige ventée neige humide

Déclenchements provoqués :
Le manteau neigeux reste instable en toutes orientations avec des avalanches de plaques déclenchables au passage d'un skieur, certainement plus épaisses (taille moyenne, voire grande) dans un large secteur nord à sud-est en altitude.
De nouvelles plaques continuent à se former lundi avec le vent de sud/sud-ouest et s'ajoutent aux plaques formées lors des chutes de neige ventée des derniers jours. Ces instabilités sont parfois loin des crêtes et peuvent être dans des orientations variées. Elles reposent sur une neige plus meuble faisant office de couche fragile, voire possiblement par endroits sur une couche fragile plus profondément enfouie.

Départs spontanés :
Avalanche de taille petite à moyenne, plus rarement grande.
Sous 2000/2100 m en toutes orientations, des avalanches spontanées peuvent entrainer l'ensemble de la neige récente, parfois même jusqu'au sol, dans les pentes raides en cours d'humidification. Départs ponctuels ou linéaires emportant les plaques formées ces derniers jours. Plus haut, des avalanches sont possibles dans les pentes raides d'un large secteur nord, par surcharge due au transport de neige par le vent de sud.

Autres : Quelques reptations se sont ouvertes ou pourraient s'ouvrir demain avec le redoux.

Qualité de la neige

Enneigement :
Enneigement excellent et excédentaire pour la saison, avec des cumuls importants de neige récente en montagne et des chutes de neige fraiche jusqu'à dimanche matin. Lundi, on pourra chausser les skis dès 1100 m en nord et plutôt 1200/1300 m au sud.

État de la neige
Lundi matin, la neige sera le plus souvent regelée en dessous de 1800/2000 m avec une croûte plutôt portante. En journée, la neige va progressivement s'humidifier, jusqu'à 2200/2300 m en sud, et plutôt vers 2000 m en nord. L'humidification se fera en profondeur sous 2000 m avec plusieurs dizaines de cm de neige lourde devenant collante. Les précipitations proches de la crête frontière en fin de journée faciliteront également l'humidification dans ces zones.
Plus haut, la neige devrait encore rester plus fraîche et légère dans les versants ombragés. On pourra trouver des combes poudreuses en altitude à l'abri du vent mais la neige sera souvent compacté par le vent avec une couverture très hétérogène proche des crêtes et sommets.

Aperçu météo pour le lundi 02 février

	nuit	matin	après-midi	soir

Fort vent de sud et effet de foehn. Douceur et quelques précipitations, principalement proche de la crête frontalière.

Pluie-Neige		2 000 m	1 900 m	1 500 m
Iso 0 °C	2 500 m	2 800 m	2 800 m	2 000 m
Vent 2000 m	↑ 30 km/h	↑ 65 km/h	↑ 80 km/h	↗ 45 km/h
Vent 3000 m	↑ 60 km/h	↑ 100 km/h	↑ 110 km/h	↑ 85 km/h

Épaisseur de neige hors-piste

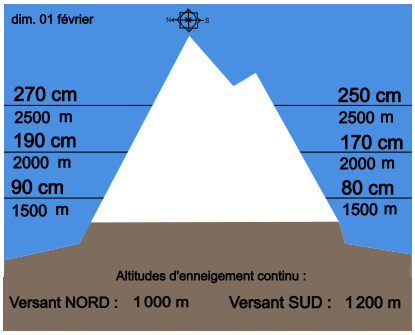

Précipitations à 1800 m

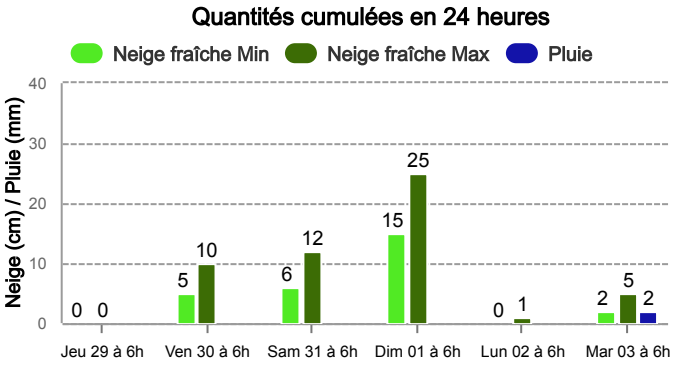

Tendance du mardi 03 février

3 **Indice de risque marqué**

Tendance à la stabilisation progressive des chutes de neige récente.

Pour consulter la vigilance en cours, veuillez vous rendre sur le site https://vigilance.meteofrance.fr/fr

Météo-France - 73 avenue de Paris, 94165 Saint-Mandé cedex - Contact : contact@meteo.fr

Rédigé par Météo-France avec la contribution des observateurs du réseau nivo-météorologiques. Partenariat : ANMSM (Maires de Stations de Montagne), DSF (Domaines Skiables de France), ADSP (Directeurs de Pistes et de la Sécurité des Stations de Sports d'Hiver) et autres acteurs de la montagne.

Bulletin neige & avalanches par téléphone au **0 892 68 10 20** Service 0,35 € / min + prix appel

RÉPUBLIQUE FRANÇAISE
Liberté Égalité Fraternité

METEO FRANCE
À VOS CÔTÉS, DANS UN CLIMAT QUI CHANGE

Bulletin d'estimation du risque d'avalanche

(valable en dehors des pistes balisées et ouvertes)

MASSIF : Couserans

Rédigé le dimanche 1 février 2026 à 16h

Conditions nivo-météo des 7 derniers jours

	lun. 26/01				mar. 27/01				mer. 28/01				jeu. 29/01				ven. 30/01				sam. 31/01				dim. 01/02			
	03h	09h	15h	21h	03h	09h	15h	21h	03h	09h	15h	21h	03h	09h	15h	21h	03h	09h	15h	21h	03h	09h	15h	21h	03h	09h	15h	21h
Météo																												
Vent (km/h)	80	65	40	45	70	90	80	45	40	50	50	55	50	50	55	75	80	70	60	40	65	70	75	70	60	30	25	40
à 3000m	↓	↓	↓	↑	↑	↑	↑	↑	↑	↑	↘	↘	↘	↘	↘	↘	↘	↘	↘	↘	↘	↘	↘	↘	↘	↘	↘	↑
Vent (km/h)	65	45	30	30	50	65	55	25	25	35	35	35	30	30	40	50	55	45	45	25	50	50	45	50	45	20	15	20
à 2000m	↘	→	→	↗	↗	↑	↗	↘	↑	↑	↘	→	↘	→	→	→	→	→	→	→	↑	↘	→	↘	→	→	↗	↑

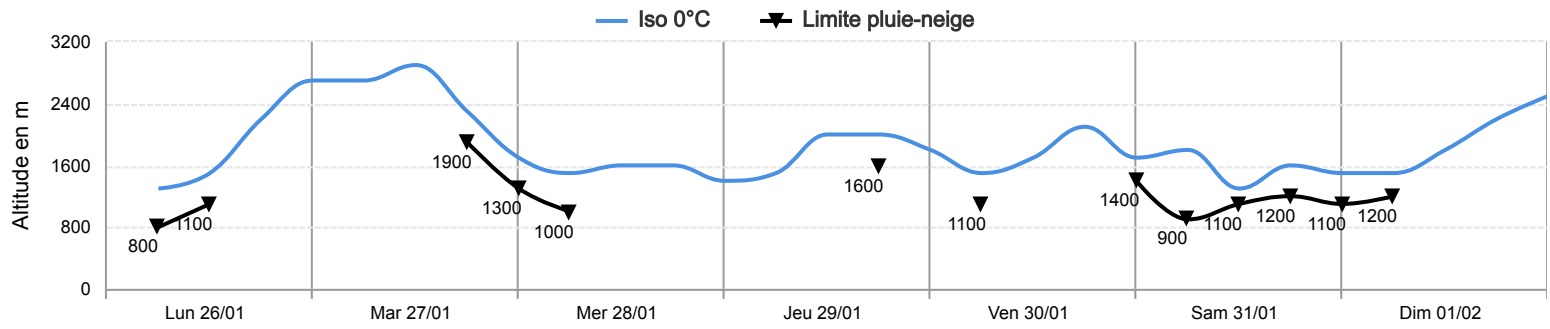

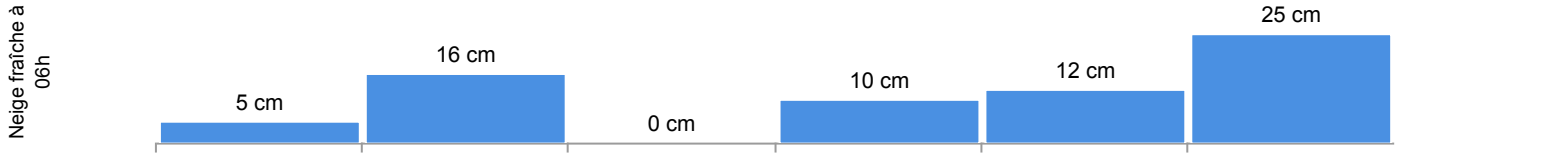

Risque d'avalanche	lun. 26/01	mar. 27/01	mer. 28/01	jeu. 29/01	ven. 30/01	sam. 31/01	dim. 01/02
	4	4	3	3	3	4	4

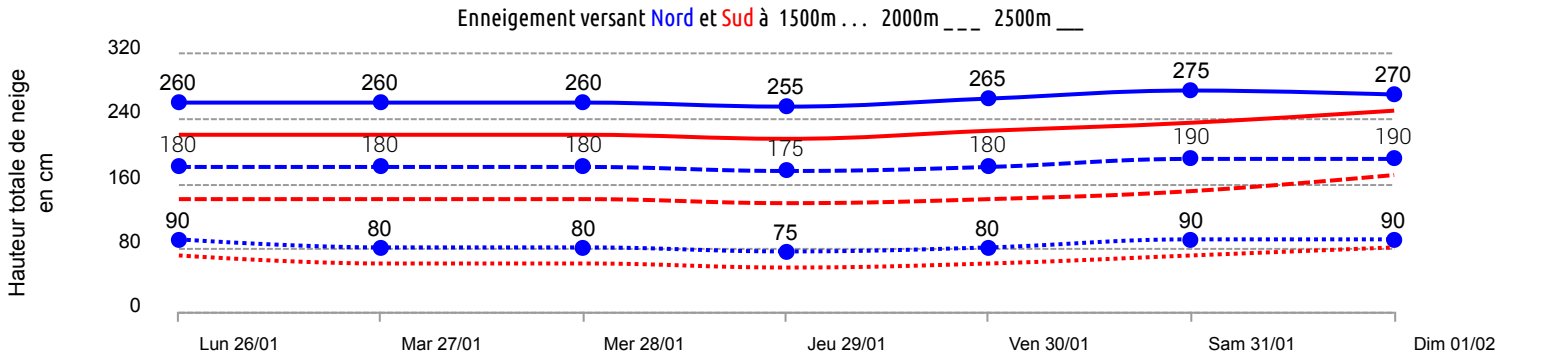

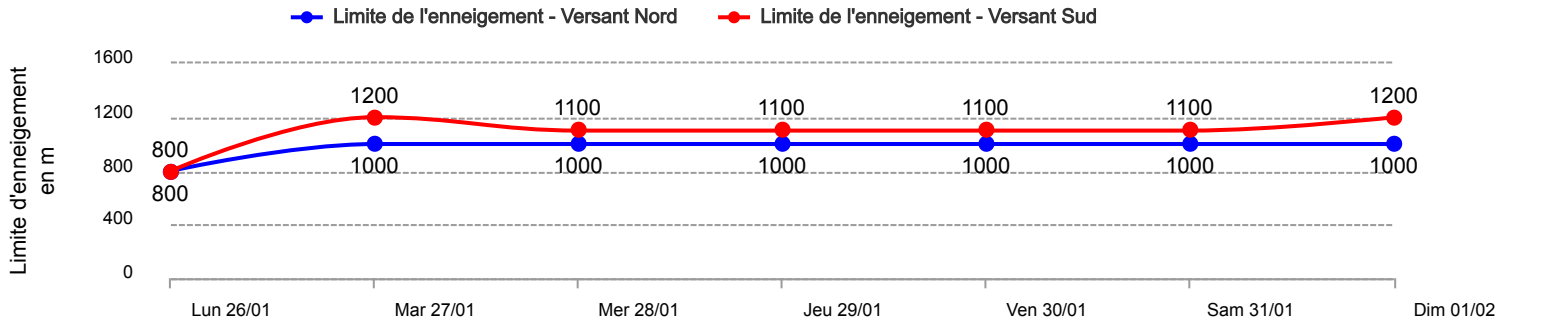

Pour consulter la vigilance en cours, veuillez vous rendre sur le site https://vigilance.meteofrance.fr/fr

Météo-France - 73 avenue de Paris, 94165 Saint-Mandé cedex - Contact : contact@meteo.fr

Rédigé par Météo-France avec la contribution des observateurs du réseau nivo-météorologiques. Partenariat : ANMSM (Maires de Stations de Montagne), DSF (Domaines Skiables de France), ADSP (Directeurs de Pistes et de la Sécurité des Stations de Sports d'Hiver) et autres acteurs de la montagne.

Bulletin neige & avalanches par téléphone au
0 892 68 10 20 Service 0,35 € / min + prix appel