Bulletin d'estimation du risque d'avalanche

(valable en dehors des pistes balisées et ouvertes)

MASSIF : Devoluy

Rédigé le dimanche 1 février 2026 à 16h

Estimation des risques pour le : LUNDI 02 FÉVRIER

NOUVELLES INSTABILITÉS EN FORMATION DANS LA NEIGE VENTÉE

3

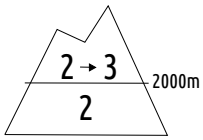

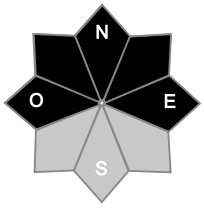

Au-dessus de 2000m indice de risque limité évoluant en marqué, plus bas indice limité.

Départs spontanés : de neige fraîche ventée en soirée et nuit suivante, taille moyenne à grande

Déclenchements provoqués : nouvelles instabilités en formation dans la neige ventée

Indices de risque : 5 très fort - 4 fort - 3 marqué - 2 limité - 1 faible -- En noir : les pentes les plus dangereuses

Stabilité du manteau neigeux

Situation avalancheuse typique : neige ventée couche fragile persistante

Déclenchements provoqués : le manteau neigeux n'est que modérément stabilisé en altitude. Ces instabilités se situent en orientations ouest, nord et est, au-dessus de 2000 m d'altitude. Un skieur peut les déclencher, parfois à distance, et générer des avalanches de taille moyenne (taille 2) . Peu nombreuses lundi matin, elles se multiplient en cours de journée, et sont le plus souvent d'aspect dur. Le fort vent de sud favorise la formation de nombreuses instabilités superficielles, qui reposent sur une couche de neige récente, faisant office de couche fragile temporaire. Plus rarement, un large départ linéaire de grande taille est possible, en cas de sollicitation de couche fragile persistante plus profondément enfouie.
En versants bien ensoleillés, et sous 2000 m environ, le risque est limité, le manteau neigeux a pris de la cohésion avec le redoux.

Départs spontanés : peu probables le matin. Ils se multiplient à haute altitude sous l'effet du vent, puis des chutes de neige. Encore rares l'après-midi, ils deviennent nombreux en soirée, de taille moyenne, à grande.

Qualité de la neige

L'enneigement est proche des normales pour un début février en vallées, plus proche des normales au-dessus de 2000 m.

Enneigement skiable dès 800/1000 m en ubacs, avec précaution sous 1400/1500 m en adrets.

État de la neige de surface : neige récente encore légère et poudreuse dans les secteurs bien abrités (ubacs, notamment forestiers) bien densifiée par le redoux et superficiellement croûtée en adrets jusque 2200 m environ. Sinon, elle est souvent travaillée par le vent, qui favorise de la chasse-neige l'après-midi.

Aperçu météo pour le lundi 02 février

	nuit	matin	après-midi	soir

Devenant perturbé. Neige dès la mi-journée en altitude, se renforçant en soirée et nuit suivante

Pluie-Neige			1 500 m	1 800 m
Iso 0 °C	1 600 m	1 700 m	1 800 m	2 200 m
Vent 2000 m	↗ 10 km/h	↑ 25 km/h	↖ 45 km/h	↑ 90 km/h
Vent 3000 m	↘ 35 km/h	↗ 50 km/h	↑ 70 km/h	↑ 120 km/h

Épaisseur de neige hors-piste

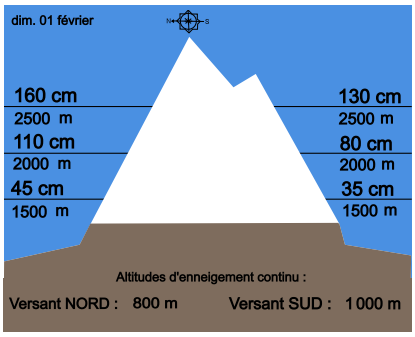

Précipitations à 1800 m

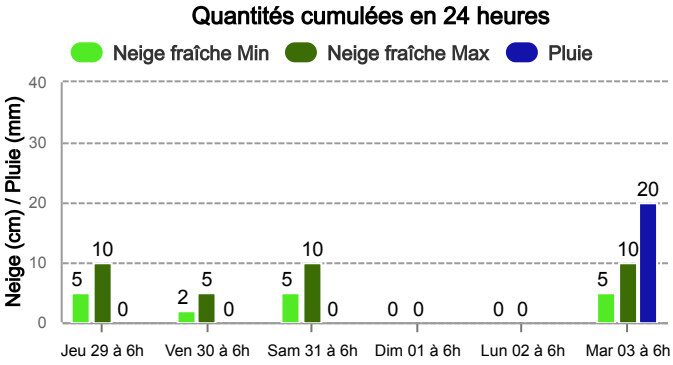

Tendance du mardi 03 février

4

Indice de risque fort

Risque en hausse après les chutes de neige de la nuit. Risque a minima marqué, mais risque fort non exclu.

Pour consulter la vigilance en cours, veuillez vous rendre sur le site https://vigilance.meteofrance.fr/fr

Météo-France - 73 avenue de Paris, 94165 Saint-Mandé cedex - Contact : contact@meteo.fr

Rédigé par Météo-France avec la contribution des observateurs du réseau nivo-météorologiques. Partenariat : ANMSM (Maires de Stations de Montagne), DSF (Domaines Skiables de France), ADSP (Directeurs de Pistes et de la Sécurité des Stations de Sports d'Hiver) et autres acteurs de la montagne.

Bulletin neige & avalanches par téléphone au

0 892 68 10 20 Service 0,35 € / min + prix appel

RÉPUBLIQUE FRANÇAISE
Liberté Égalité Fraternité

METEO FRANCE
À VOS CÔTÉS, DANS UN CLIMAT QUI CHANGE

Bulletin d'estimation du risque d'avalanche

(valable en dehors des pistes balisées et ouvertes)

MASSIF : Devoluy

Rédigé le dimanche 1 février 2026 à 16h

Conditions nivo-météo des 7 derniers jours

	lun. 26/01				mar. 27/01				mer. 28/01				jeu. 29/01				ven. 30/01				sam. 31/01				dim. 01/02			
	03h	09h	15h	21h	03h	09h	15h	21h	03h	09h	15h	21h	03h	09h	15h	21h	03h	09h	15h	21h	03h	09h	15h	21h	03h	09h	15h	21h
Météo																												
Vent (km/h)	30	50	50	20	20	50	70	70	60	40	35	50	50	35	30	30	35	40	40	25	25	5	5	10	20	20	40	30
à 3000m																												
Vent (km/h)	30	50	40	15	10	45	65	55	40	30	25	50	50	30	20	15	15	30	25	15	15	15	15	10	20	20	15	10
à 2000m																												

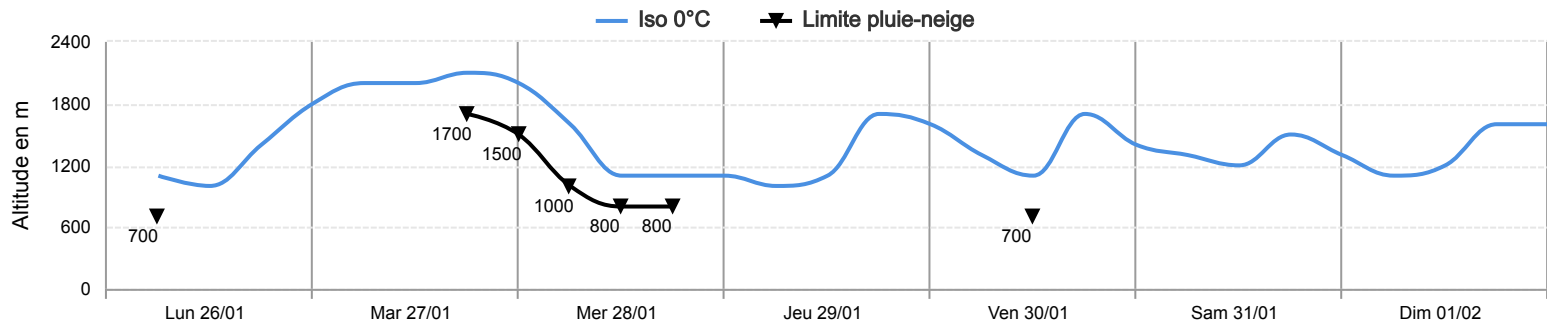

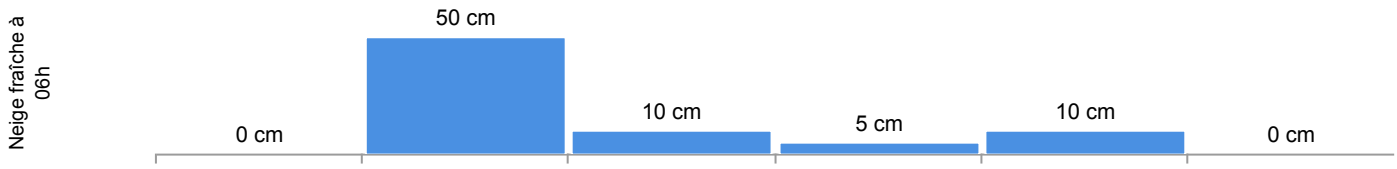

Risque d'avalanche	lun. 26/01	mar. 27/01	mer. 28/01	jeu. 29/01	ven. 30/01	sam. 31/01	dim. 01/02
	3	4	4	4	4	3	3

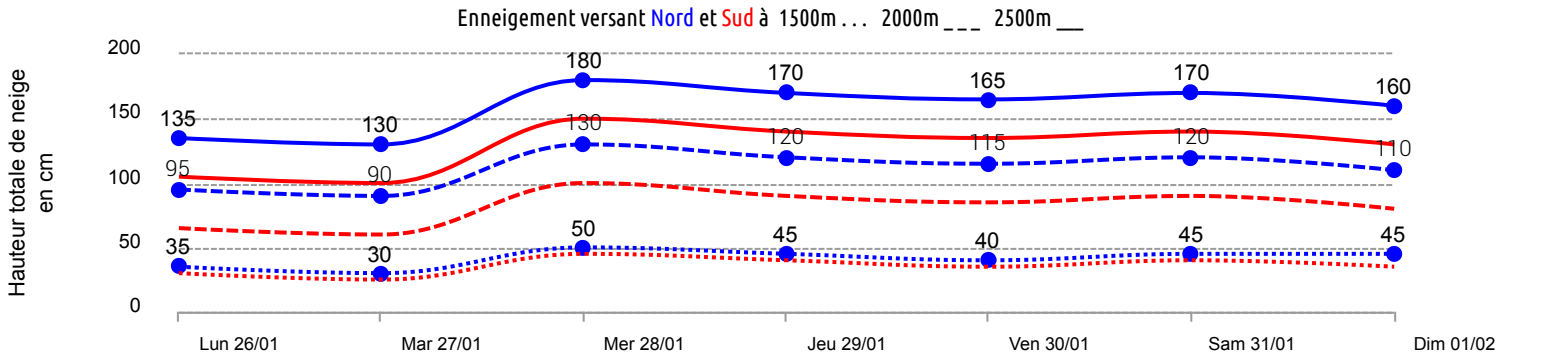

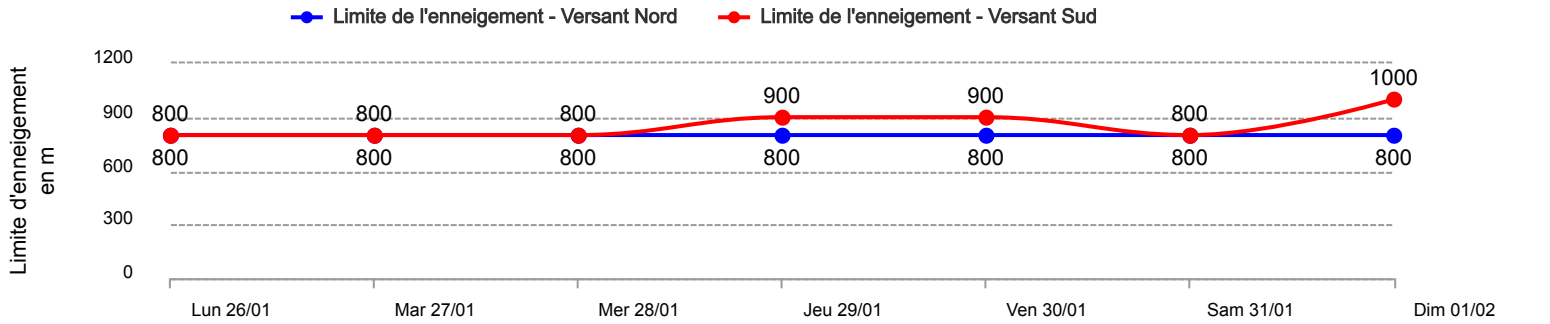

Pour consulter la vigilance en cours, veuillez vous rendre sur le site https://vigilance.meteofrance.fr/fr

Météo-France - 73 avenue de Paris, 94165 Saint-Mandé cedex - Contact : contact@meteo.fr

Bulletin neige & avalanches par téléphone au

0 892 68 10 20 Service 0,35 € / min + prix appel

Rédigé par Météo-France avec la contribution des observateurs du réseau nivo-météorologiques. Partenariat : ANMSM (Maires de Stations de Montagne), DSF (Domaines Skiables de France), ADSP (Directeurs de Pistes et de la Sécurité des Stations de Sports d'Hiver) et autres acteurs de la montagne.