Bulletin d'estimation du risque d'avalanche
(valable en dehors des pistes balisées et ouvertes)

MASSIF : Embrunais Parpaillon

Rédigé le dimanche 1 février 2026 à 16h

Estimation des risques pour le : LUNDI 02 FÉVRIER

INSTABILITÉS PERSISTANT EN ALTITUDE, DE NOUVELLES EN FORMATION

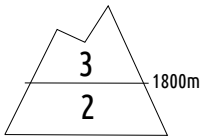

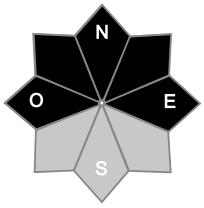

Au-dessus de 1800m indice de risque marqué, plus bas indice limité.

Départs spontanés : de neige fraîche ventée en soirée et nuit suivante, taille moyenne à grande

Déclenchements provoqués : instabilités en altitude, parfois très volumineuses

Indices de risque : 5 très fort - 4 fort - 3 marqué - 2 limité - 1 faible -- En noir : les pentes les plus dangereuses

Stabilité du manteau neigeux

Situation avalancheuse typique : couche fragile persistante neige ventée

Déclenchements provoqués : le manteau neigeux n'est que faiblement à modérément stabilisé en altitude. Ces instabilités se situent principalement en orientations ouest, nord et est d'altitude supérieure à 1800/2000 m. Un skieur isolé peut parfois les déclencher, même à distance, et générer des avalanches de taille moyenne (taille 2) à grande (taille 3). Ces instabilités restent souvent d'aspect friable, et non détectables depuis la surface. La neige récente repose en effet sur une couche fragile régulièrement répartie au sein du manteau neigeux. Ces instabilités restent possibles dans les secteurs réputés peu dangereux, comme les forêts clairsemées ; par ailleurs, en situation avalancheuse typique de couche fragile persistante, une pente déjà skiée n'est pas synonyme de stabilité.
De nouvelles instabilités se forment en cours de journée, surtout au-dessus de 2400/2500 m environ. Situées dans les zones d'accumulation par le vent de sud à est, parfois loin des crêtes, ces instabilités se présentent sous forme de plaques plus dures, et plus facilement identifiables.
En versants bien ensoleillés, et sous 1800 m environ, le risque est plus limité. La neige récente a pris de la cohésion et les couches fragiles persistantes sont moins fréquentes.

Départs spontanés : peu probables le matin. Ils se multiplient à haute altitude sous l'effet du vent, puis des chutes de neige. Encore rares l'après-midi, ils deviennent nombreux en soirée, de taille moyenne à grande.

Qualité de la neige

L'enneigement est un peu excédentaire pour un début février, notamment en vallées. Données observées vers 2500 m : 134 cm de neige dans le vallon du Chardonnet, 95 cm à la Nivôse du Galibier, 48 cm à celle des Rochilles.

Enneigement skiable dès les fonds de vallées, sous-couche un peu faible en adrets sous 1600 m.

État de la neige de surface : neige récente meuble (20 à 40 cm), encore légère et poudreuse en ubacs abrités du vent, bien densifiée par le redoux et superficiellement croûtée en adrets jusque 2200 m environ. Plus haut, neige plus souvent travaillée par le vent, qui favorise de la chasse-neige l'après-midi. Crêtes bien chargées, congères dans les pentes.

Aperçu météo pour le lundi 02 février

	nuit	matin	après-midi	soir
Devenant perturbé. Neige dès la mi-journée en altitude, se renforçant en soirée et nuit suivante				
Pluie-Neige			1 500 m	1 600 m
Iso 0 °C	1 600 m	1 600 m	1 900 m	2 000 m
Vent 2000 m	↗ 10 km/h	→ 10 km/h	↑ 15 km/h	↖ 25 km/h
Vent 3000 m	↘ 30 km/h	↗ 30 km/h	↗ 45 km/h	↑ 75 km/h

Épaisseur de neige hors-piste

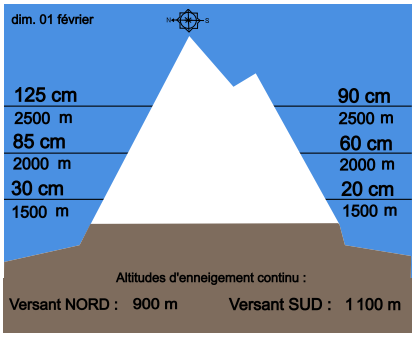

Précipitations à 1800 m

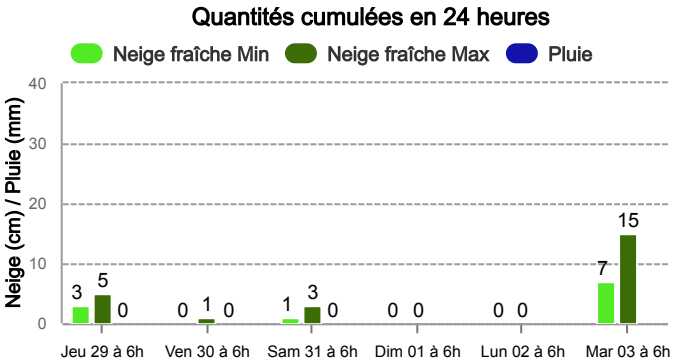

Tendance du mardi 03 février

Indice de risque fort

Forte instabilité du manteau neigeux après les chutes de neige ventées de la nuit, qui occasionnent de nombreuses avalanches de taille moyenne à grande.
Risque fort.

Pour consulter la vigilance en cours, veuillez vous rendre sur le site https://vigilance.meteofrance.fr/fr

Météo-France - 73 avenue de Paris, 94165 Saint-Mandé cedex - Contact : contact@meteo.fr

Rédigé par Météo-France avec la contribution des observateurs du réseau nivo-météorologiques. Partenariat : ANMSM (Maires de Stations de Montagne), DSF (Domaines Skiables de France), ADSP (Directeurs de Pistes et de la Sécurité des Stations de Sports d'Hiver) et autres acteurs de la montagne.

Bulletin neige & avalanches par téléphone au
0 892 68 10 20 Service 0,35 € / min + prix appel

RÉPUBLIQUE FRANÇAISE
Liberté Égalité Fraternité

METEO FRANCE
À VOS CÔTÉS, DANS UN CLIMAT QUI CHANGE

Bulletin d'estimation du risque d'avalanche

(valable en dehors des pistes balisées et ouvertes)

MASSIF : Embrunais Parpaillon

Rédigé le dimanche 1 février 2026 à 16h

Conditions nivo-météo des 7 derniers jours

	lun. 26/01				mar. 27/01				mer. 28/01				jeu. 29/01				ven. 30/01				sam. 31/01				dim. 01/02			
	03h	09h	15h	21h	03h	09h	15h	21h	03h	09h	15h	21h	03h	09h	15h	21h	03h	09h	15h	21h	03h	09h	15h	21h	03h	09h	15h	21h
Météo																												
Vent (km/h)	20	30	30	20	20	40	55	60	60	50	30	40	40	30	25	30	35	35	40	30	25	20	10	15	15	15	25	35
à 3000m																												
Vent (km/h)	10	15	15	10	5	25	45	50	40	25	15	25	25	15	15	20	20	25	30	20	15	15	10	10	10	10	10	10
à 2000m																												

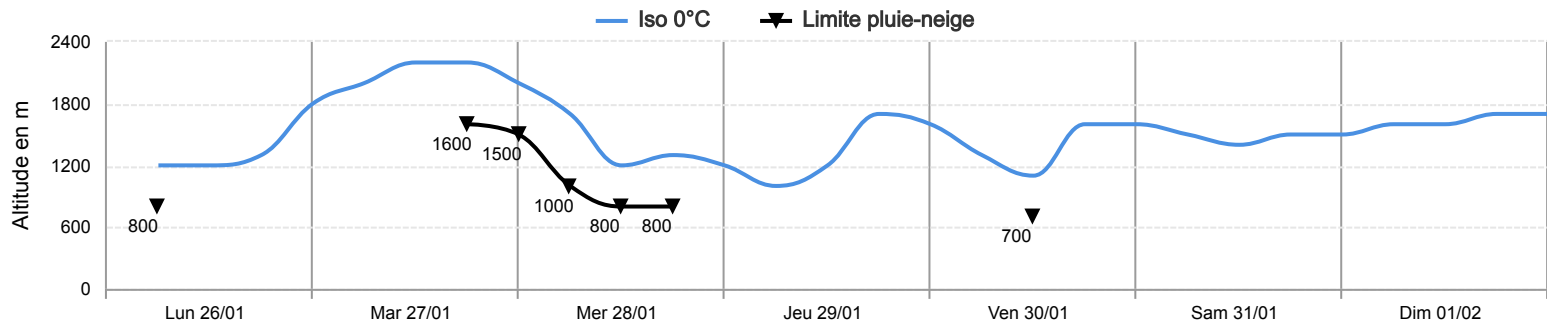

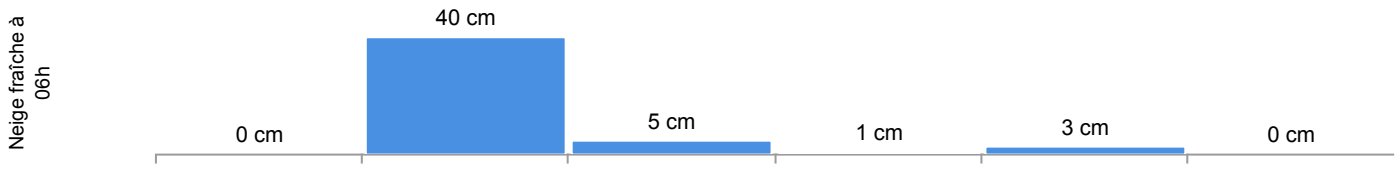

Risque d'avalanche	lun. 26/01	mar. 27/01	mer. 28/01	jeu. 29/01	ven. 30/01	sam. 31/01	dim. 01/02
	3	4	4	4	4	3	3

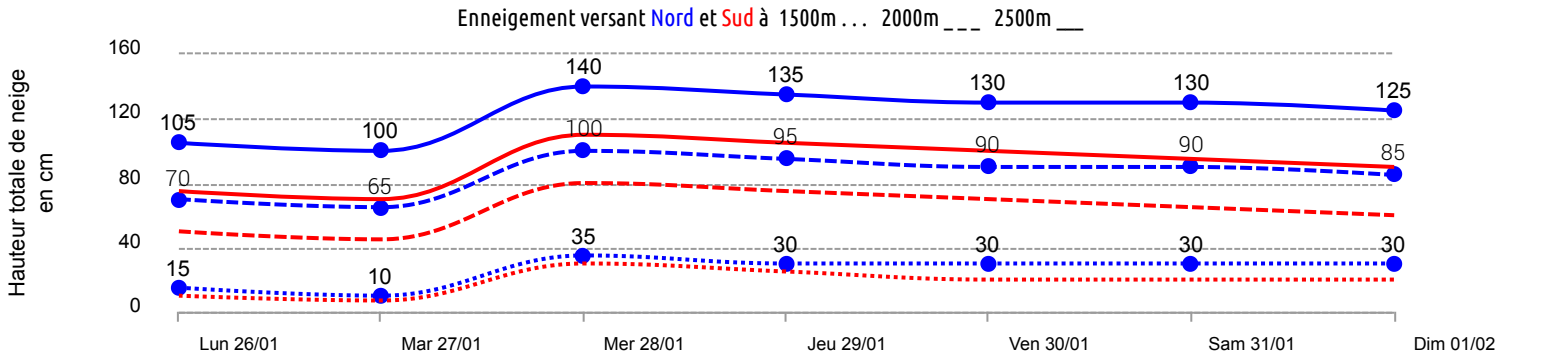

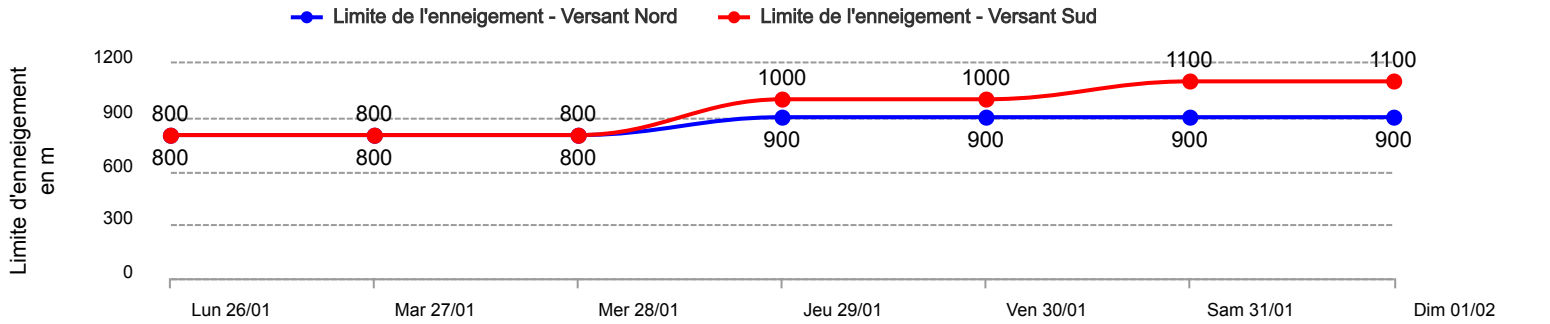

Pour consulter la vigilance en cours, veuillez vous rendre sur le site https://vigilance.meteofrance.fr/fr

Météo-France - 73 avenue de Paris, 94165 Saint-Mandé cedex - Contact : contact@meteo.fr

Bulletin neige & avalanches par téléphone au

0 892 68 10 20 Service 0,35 € / min + prix appel

Rédigé par Météo-France avec la contribution des observateurs du réseau nivo-météorologiques. Partenariat : ANMSM (Maires de Stations de Montagne), DSF (Domaines Skiables de France), ADSP (Directeurs de Pistes et de la Sécurité des Stations de Sports d'Hiver) et autres acteurs de la montagne.