Bulletin d'estimation du risque d'avalanche

(valable en dehors des pistes balisées et ouvertes)

MASSIF : Haut-Var Haut-Verdon

Rédigé le dimanche 1 février 2026 à 16h

Estimation des risques pour le : LUNDI 02 FÉVRIER

RISQUE MARQUÉ DE DÉCLENCHEMENT ACCIDENTEL : QUELQUES PLAQUES VOLUMINEUSES ET LOCALEMENT INSTABLES

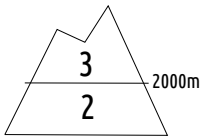

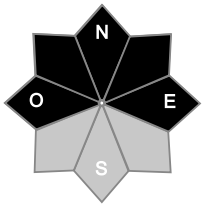

Au-dessus de 2000m indice de risque marqué, plus bas indice limité.

Départs spontanés : rares départs en neige fraiche ventée en soirée.

Déclenchements provoqués : quelques instabilités encore localement faciles à déclencher, parfois volumineuses

Indices de risque : 5 très fort - 4 fort - 3 marqué - 2 limité - 1 faible -- En noir : les pentes les plus dangereuses

Stabilité du manteau neigeux

Situation avalancheuse typique : neige ventée couche fragile persistante

Déclenchements provoqués :
Quelques plaques encore en place dans la neige récente. Possibles en toutes orientations, elles sont maintenant plutôt stabilisées, mais peuvent encore localement être faciles à déclencher au passage d'un skieur, notamment en fin de journée avec le retour des chutes de neige et le renforcement du vent. Le plus souvent d'aspect friable et difficiles à détecter, elles provoquent des avalanches de taille moyenne, parfois grande (taille 2 à 3).

Dans les versants est, nord et ouest au-dessus de 2000 m environ, une avalanche plus volumineuse est possible (taille 3, rare taille 4 non exclue) en cas de sollicitation de couches fragiles persistantes enfouies plus en profondeur dans le manteau neigeux. Déclenchement plus difficile mais possible au passage d'un skieur, notamment sur les croupes ou en bords de couloir où le manteau est moins épais, parfois à distance ; ou en cas de sur-avalanche après un premier départ dans la neige de surface.

En dessous de 2000 m les plaques sont moins nombreuses et moins volumineuses, mais leur présence reste possible en versants ombragés.

Départs spontanés : quelques boulettes au soleil en matinée. Rares départs de neige fraiche ventée en fin de journée, de taille petite à moyenne.

Qualité de la neige

Enneigement excédentaire à basse altitude pour une fin janvier.
Données observées à 2000 m en fond de vallon : 110 à 130 cm de hauteur totale de neige.

Enneigement skiable dès 1200/1300 m en terrain favorable, mais peu de sous-couche sous 1600 m en général.

État de la neige en surface : épaisse couche de neige récente : 20/30 cm à 1500 m, 40/50 cm à partir de 1800 m, localement 60 cm dans le Haut-Verdon. Cette neige est légèrement croutée en surface sous 1500/2000 m selon les orientations, souvent froide et légère au-dessus, localement travaillée par le vent en altitude. Corniches parfois volumineuses en place sur les crêtes.

Aperçu météo pour le lundi 02 février

	nuit	matin	après-midi	soir
Éclaircies le matin avant l'arrivée de faibles chute de neige l'après-midi, se renforçant en soirée.				
Pluie-Neige			1 000 m	1 200 m
Iso 0 °C	1 500 m	1 600 m	1 600 m	1 700 m
Vent 2000 m	↘ 10 km/h	→ 10 km/h	↖ 20 km/h	↖ 30 km/h
Vent 3000 m	↘ 20 km/h	↑ 25 km/h	↖ 40 km/h	↖ 55 km/h

Épaisseur de neige hors-piste

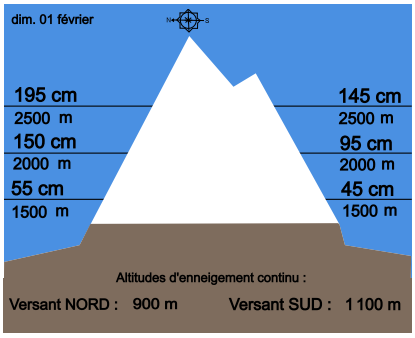

Précipitations à 1800 m

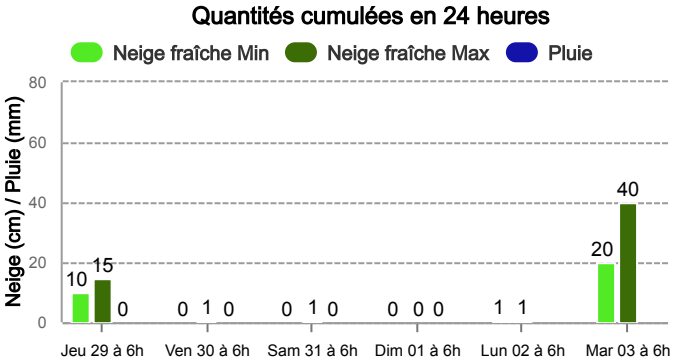

Tendance du mardi 03 février

Indice de risque fort

Risque devenant fort en cours de nuit de lundi à mardi avec les importantes chutes de neige. Nombreux départs spontanés volumineux attendus.

Pour consulter la vigilance en cours, veuillez vous rendre sur le site https://vigilance.meteofrance.fr/fr

Météo-France - 73 avenue de Paris, 94165 Saint-Mandé cedex - Contact : contact@meteo.fr

Rédigé par Météo-France avec la contribution des observateurs du réseau nivo-météorologiques. Partenariat : ANMSM (Maires de Stations de Montagne), DSF (Domaines Skiables de France), ADSP (Directeurs de Pistes et de la Sécurité des Stations de Sports d'Hiver) et autres acteurs de la montagne.

Bulletin neige & avalanches par téléphone au **0 892 68 10 20** Service 0,35 € / min + prix appel

RÉPUBLIQUE FRANÇAISE
Liberté Égalité Fraternité

METEO FRANCE
À VOS CÔTÉS, DANS UN CLIMAT QUI CHANGE

Bulletin d'estimation du risque d'avalanche

(valable en dehors des pistes balisées et ouvertes)

MASSIF : Haut-Var Haut-Verdon

Rédigé le dimanche 1 février 2026 à 16h

Conditions nivo-météo des 7 derniers jours

	lun. 26/01				mar. 27/01				mer. 28/01				jeu. 29/01				ven. 30/01				sam. 31/01				dim. 01/02			
	03h	09h	15h	21h	03h	09h	15h	21h	03h	09h	15h	21h	03h	09h	15h	21h	03h	09h	15h	21h	03h	09h	15h	21h	03h	09h	15h	21h
Météo																												
Vent (km/h)	30	30	30	20	20	55	65	60	45	25	5	30	45	40	35	20	45	60	50	20	20	20	20	15	20	15	15	15
à 3000m																												
Vent (km/h)	25	20	15	10	10	15	15	15	15	15	5	25	35	25	25	15	20	30	25	10	15	15	15	15	10	10	15	10
à 2000m																												

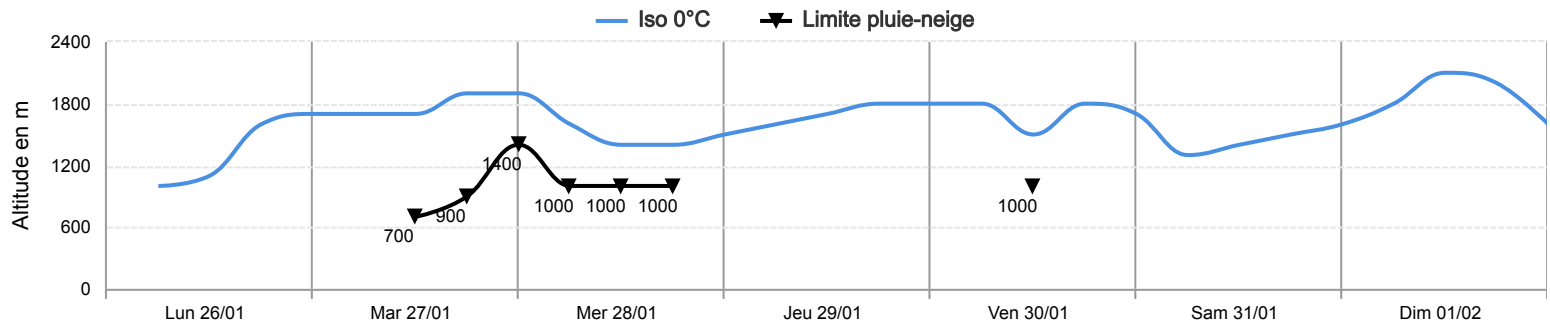

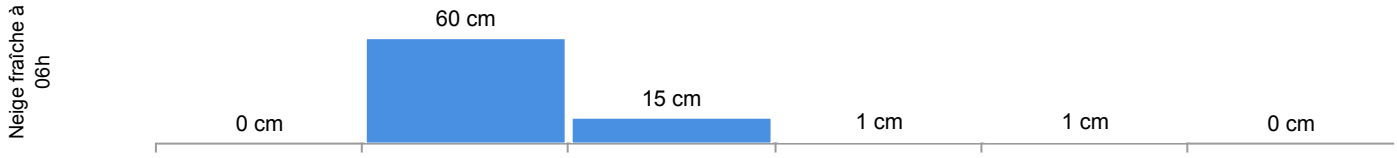

Risque d'avalanche	lun. 26/01	mar. 27/01	mer. 28/01	jeu. 29/01	ven. 30/01	sam. 31/01	dim. 01/02
	3	4	4	4	4	3	3

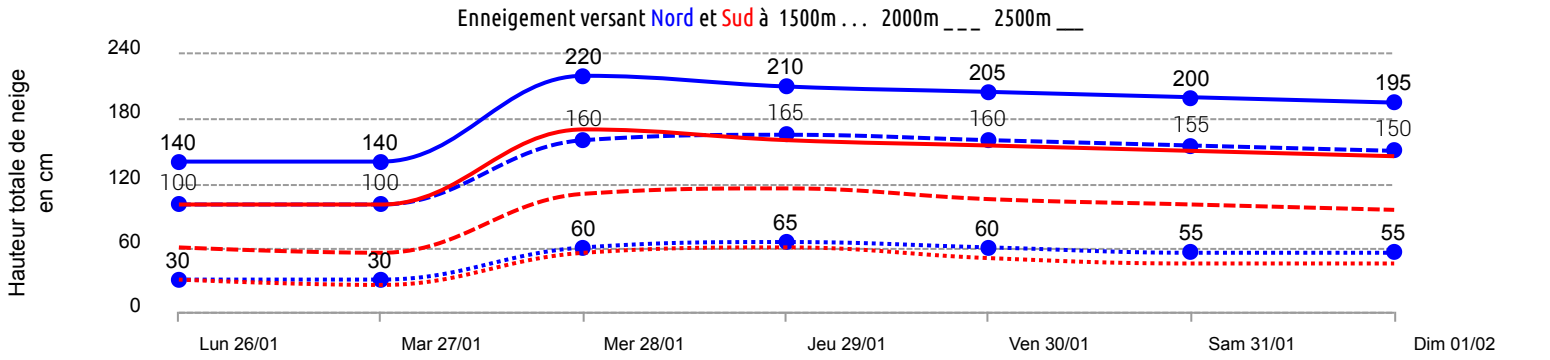

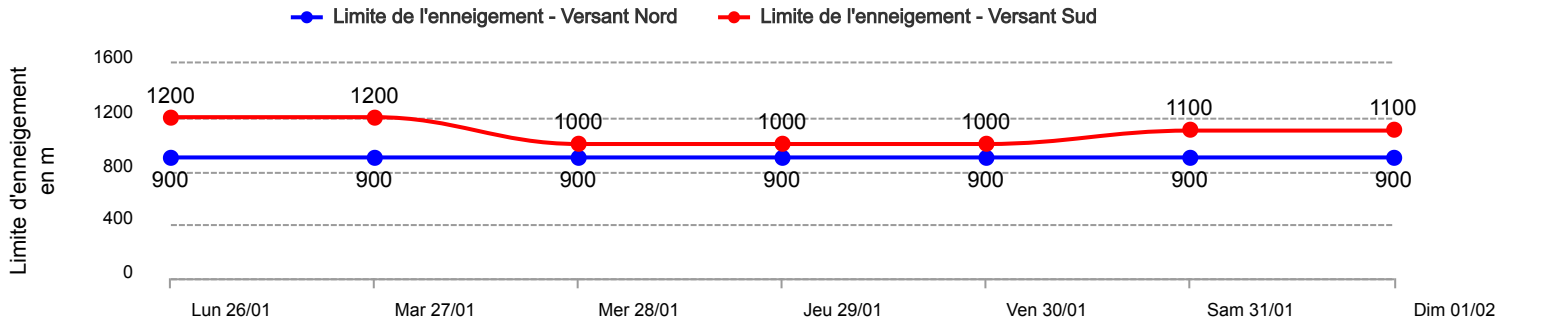

Pour consulter la vigilance en cours, veuillez vous rendre sur le site https://vigilance.meteofrance.fr/fr

Météo-France - 73 avenue de Paris, 94165 Saint-Mandé cedex - Contact : contact@meteo.fr

Rédigé par Météo-France avec la contribution des observateurs du réseau nivo-météorologiques. Partenariat : ANMSM (Maires de Stations de Montagne), DSF (Domaines Skiables de France), ADSP (Directeurs de Pistes et de la Sécurité des Stations de Sports d'Hiver) et autres acteurs de la montagne.

Bulletin neige & avalanches par téléphone au
0 892 68 10 20 Service 0,35 € / min + prix appel