Bulletin d'estimation du risque d'avalanche

(valable en dehors des pistes balisées et ouvertes)

MASSIF : Luchonnais

Rédigé le dimanche 1 février 2026 à 16h

Estimation des risques pour le : LUNDI 02 FÉVRIER

NEIGE HUMIDE SOUS 2000 M, NEIGE VENTEE AU-DESSUS.

3

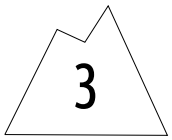

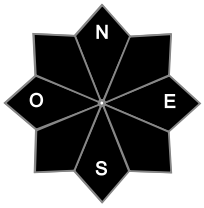

Plaques ventées

Indice de risque marqué.

Départs spontanés : Départs linéaires et ponctuels en neige humide ou ventée.

Déclenchements provoqués : Des plaques en formation lundi après-midi.

Indices de risque : 5 très fort - 4 fort - 3 marqué - 2 limité - 1 faible -- En noir : les pentes les plus dangereuses

Stabilité du manteau neigeux

Situation avalancheuse typique : neige humide neige ventée

Déclenchements provoqués :
Au-dessus de 2200 m: Par déclenchement en cassure linéaire des plaques formées ce samedi ou en formation, un randonneur peut induire des avalanches de tailles moyennes en toutes orientations ou parfois grandes dans les pentes d'accumulation (Nord/Nord-Est à Sud-Est) à l'issue des chutes de neige lundi après-midi. Avec le vent les plaques en sud peuvent rester sensibles au passage d'un randonneur.
Sous 2200 m : des **plaques instables sont en place,** mais l'humidification les rend plus difficilement déclenchables cette nuit et surtout lundi. Après l'humidification jusqu'à lundi midi et avec les chutes neigeuses en après-midi, de nouvelles plaques ventées se forment lundi après-midi au-dessus de 1800 m puis 1600/1500 m, elles sont **moins facilement déclenchables que les jours précédents. Par déclenchement en cassure linéaire par un randonneur ou par plusieurs, il peut résulter des avalanches de tailles petites à moyennes, rarement grandes en pentes nord d'accumulation si emport par cascade** des couches déposées ces 8 derniers jours.

Départs spontanés :
Au-dessus de 2000/2200 m : Le vent peut facilement déclencher les plaques récentes, des avalanches linéaires petites en secteur larges secteur ouest ou moyennes (taille 2) à grandes ailleurs restent probables. Activité naturelles favorisée par les chutes de neige en journée surtout en secteurs frontaliers où seront observés les meilleurs cumuls (15 à 30 cm vers 2500 m).

Sous 2200 m: L'humidification en cours se poursuit cette nuit et lundi midi jusqu'à 1900/2100 m. Des avalanches nombreuses sont à attendre cette nuit et surtout lundi, de taille petites à moyennes rarement grandes en larges versants Nord-Est à Sud. Avalanches ponctuelles en coulées en journée, mais aussi linéaires en pentes raides par glissement de fond lorsque l'humidification atteint le sol pour les plaques en place.

Qualité de la neige

Enneigement : L'enneigement est assez correct pour la saison, mais les crêtes, cols et sommets sont souvent pelés par le vent dans les expositions ouest. Sous 1800/1600 m le manteau neigeux prend la pluie et tend à se réduire fortement en après-midi ce lundi.
Limites skiables : Manteau neigeux skiable à partir de 1300 m le matin, probablement 1800 m en après-midi.
État de la neige : Neige souvent cartonnée en pentes ouest et nord, friable à croûtée au petit matin sous 2300 m mais probablement non portante. Neige récente sur 3 jours sur une épaisseur moyenne de 10 à 20 cm mais s'humidifiant. Neige très ventée qui s'est accumulée sous le vent d'ouest à nord.

Aperçu météo pour le lundi 02 février

	nuit	matin	après-midi	soir

Ciel dégagé cette nuit puis plus nuageux avec de faibles ondées. Redoux, chutes de neige marquées lundi après-midi en frontalier au-dessus de 1800 m.

	nuit	matin	après-midi	soir
Pluie-Neige	1 800 m	2 000 m	1 800 m	1 400 m
Iso 0 °C	2 500 m	2 700 m	2 200 m	1 800 m
Vent 2000 m	↑ 50 km/h	↑ 95 km/h	↑ 95 km/h	↗ 50 km/h
Vent 3000 m	↑ 70 km/h	↑ 125 km/h	↑ 120 km/h	↑ 80 km/h

Épaisseur de neige hors-piste

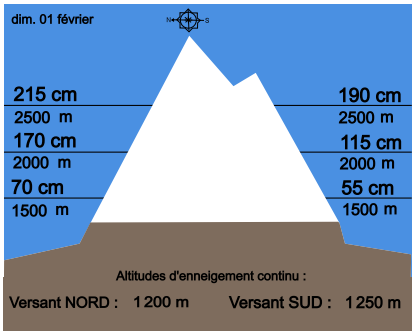

Précipitations à 1800 m

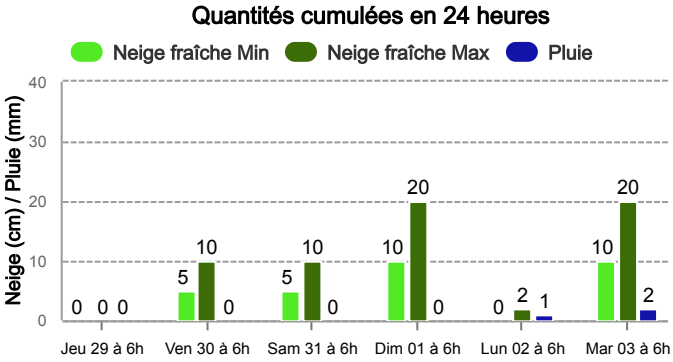

Tendance du mardi 03 février

3

Indice de risque marqué

Tassement et humidification au soleil, du transport possible sur les crêtes.

Pour consulter la vigilance en cours, veuillez vous rendre sur le site https://vigilance.meteofrance.fr/fr

Météo-France - 73 avenue de Paris, 94165 Saint-Mandé cedex - Contact : contact@meteo.fr

Rédigé par Météo-France avec la contribution des observateurs du réseau nivo-météorologiques. Partenariat : ANMSM (Maires de Stations de Montagne), DSF (Domaines Skiables de France), ADSP (Directeurs de Pistes et de la Sécurité des Stations de Sports d'Hiver) et autres acteurs de la montagne.

Bulletin neige & avalanches par téléphone au **0 892 68 10 20** Service 0,35 € / min + prix appel

RÉPUBLIQUE FRANÇAISE
Liberté Égalité Fraternité

METEO FRANCE
À VOS CÔTÉS, DANS UN CLIMAT QUI CHANGE

Bulletin d'estimation du risque d'avalanche

(valable en dehors des pistes balisées et ouvertes)

MASSIF : Luchonnais

Rédigé le dimanche 1 février 2026 à 16h

Conditions nivo-météo des 7 derniers jours

	lun. 26/01				mar. 27/01				mer. 28/01				jeu. 29/01				ven. 30/01				sam. 31/01				dim. 01/02			
	03h	09h	15h	21h	03h	09h	15h	21h	03h	09h	15h	21h	03h	09h	15h	21h	03h	09h	15h	21h	03h	09h	15h	21h	03h	09h	15h	21h
Météo																												
Vent (km/h)	90	70	50	80	110	110	65	70	60	55	55	80	70	100	70	90	100	90	60	90	100	100	100	70	40	40	45	50
à 3000m																												
Vent (km/h)	35	20	25	60	90	90	15	35	15	10	15	35	30	50	30	50	45	35	15	40	60	60	70	40	20	20	20	35
à 2000m																												

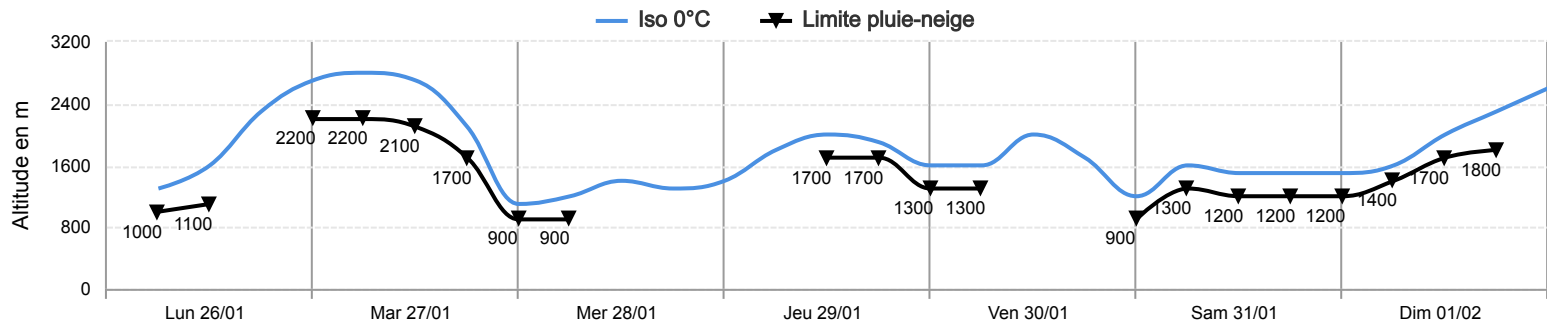

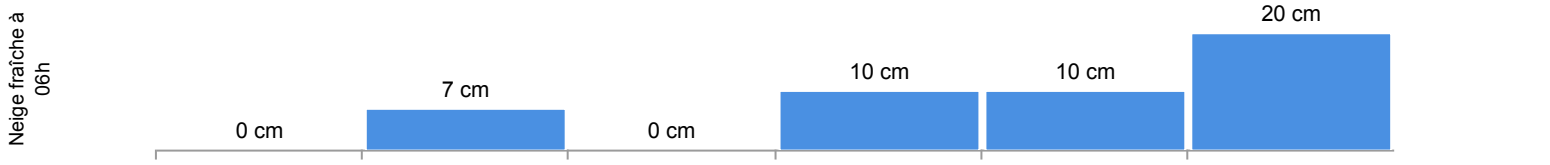

Risque d'avalanche	lun. 26/01	mar. 27/01	mer. 28/01	jeu. 29/01	ven. 30/01	sam. 31/01	dim. 01/02
	3	4	3	3	3	4	4

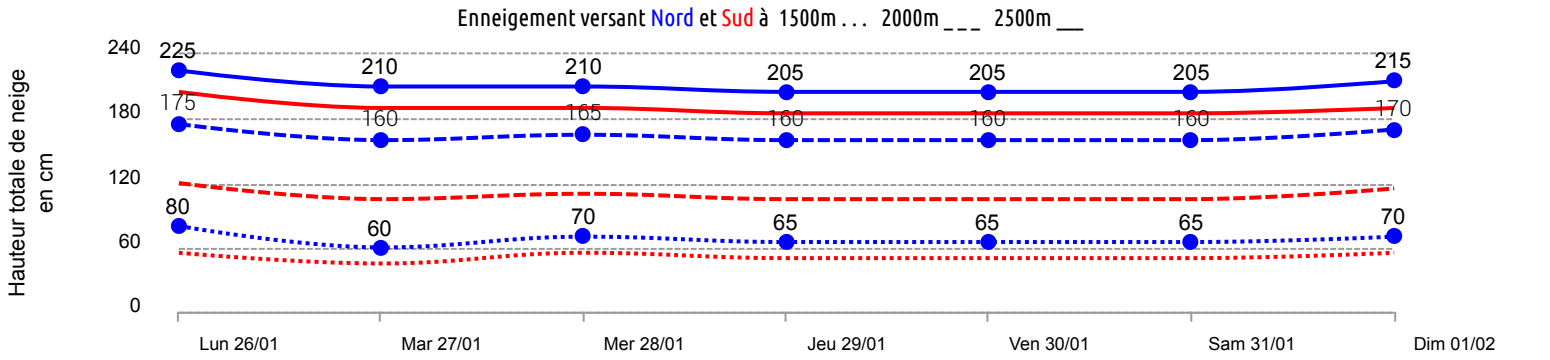

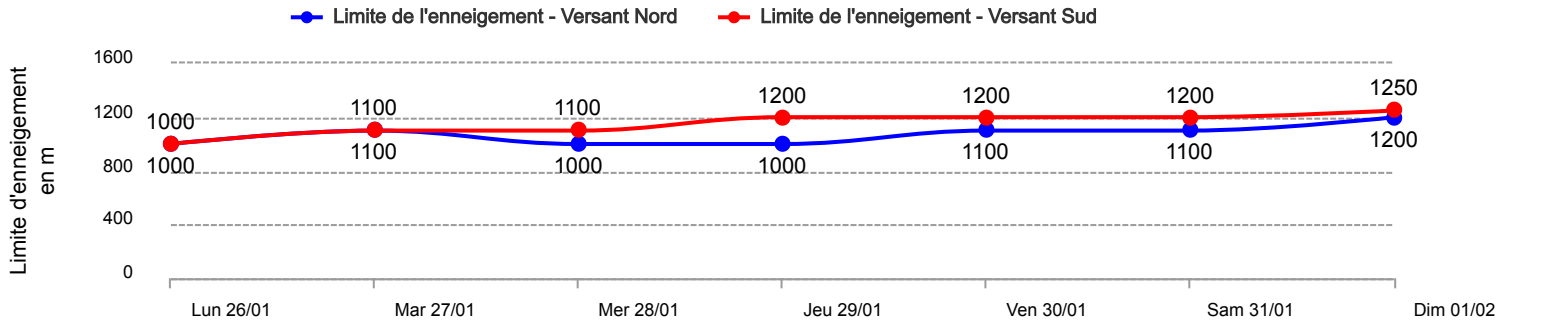

Pour consulter la vigilance en cours, veuillez vous rendre sur le site https://vigilance.meteofrance.fr/fr

Météo-France - 73 avenue de Paris, 94165 Saint-Mandé cedex - Contact : contact@meteo.fr

Rédigé par Météo-France avec la contribution des observateurs du réseau nivo-météorologiques. Partenariat : ANMSM (Maires de Stations de Montagne), DSF (Domaines Skiables de France), ADSP (Directeurs de Pistes et de la Sécurité des Stations de Sports d'Hiver) et autres acteurs de la montagne.

Bulletin neige & avalanches par téléphone au
0 892 68 10 20 Service 0,35 € / min + prix appel