Bulletin d'estimation du risque d'avalanche

(valable en dehors des pistes balisées et ouvertes)

MASSIF : Oisans

Rédigé le dimanche 1 février 2026 à 16h

Estimation des risques pour le : LUNDI 02 FÉVRIER

NOUVELLES INSTABILITÉS EN FORMATION DANS LES VERSANTS FROIDS, REPOSANT PARFOIS SUR DES COUCHES FRAGILES PERSISTANTES.

3

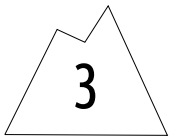

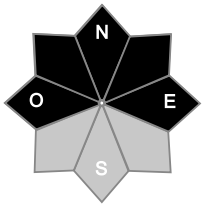

vent de Sud

Indice de risque marqué.

Départs spontanés : Rares avalanches humides en pentes "réchauffées".

Déclenchements provoqués : Nouvelles instabilités sous le vent de Sud dans les versants froids. Possibilité de grande avalanche avec déclenchement en cascade.

Indices de risque : 5 très fort - 4 fort - 3 marqué - 2 limité - 1 faible -- En noir : les pentes les plus dangereuses

Stabilité du manteau neigeux

Situation avalancheuse typique : neige ventée couche fragile persistante

Déclenchements provoqués : Risque devenant de plus en plus marqué au fil de la journée de lundi dans les versants froids d'un large Nord. De nouvelles instabilités vont se former dans la neige récente restée légère, avec le vent de Sud qui se renforce en cours de journée. D'abord assez locales et souvent peu épaisses en première partie de journée, elles se font de plus en plus nombreuses au fil des heures et notamment dans l'après-midi. Ces nouvelles plaques, souvent réactives et faciles à déclencher, sont situées dans les zones d'accumulation par le vent, à proximité des crêtes dans un premier temps, puis le risque augmente également dans les bas de pentes et plus loin des crêtes au fur et à mesure que le vent forcit. De plus, elles reposent par endroits sur des sous-couches fragiles persistantes plus enfouies qui pourraient localement favoriser des départs très volumineux par déclenchement à distance depuis un secteur moins enneigé, ou par déclenchement en cascade suite à la rupture d'une plaque de surface. Ces couches fragiles sont surtout présentes vers les Hautes Alpes (La Meije, les Ecrins, les Deux Alpes, l'Olan), et semblent plus rares vers le Taillefer. Dans ce contexte, une pente skiée n'est pas forcément un indice de stabilité. Sous 1400/1600 m environ, le risque devrait être un peu moins marqué, la neige récente s'étant davantage alourdie/humidifiée.

Départs spontanés : En journée de dimanche, de rares avalanches de neige humide de taille 1 à 2 (petites à moyennes) ne sont pas exclues dans la neige récente qui s'humidifie, notamment dans les pentes raides qui seront exposées au soleil et près des rochers. Très ponctuellement, un départ spontané linéaire (en plaque) atteignant la taille 3 ne peut toutefois être totalement exclu.

Qualité de la neige

Qualification de l'enneigement : L'enneigement s'est amélioré et est redevenu correct à bon pour la saison dès les vallées et en combes d'altitude. Les crêtes sont toutefois assez peu enneigées ainsi que les pentes Sud raides...

Limites skiables : à partir de 1100/1500 m.

Qualité de la neige lundi : Neige récente en cours de tassement, généralement encore assez légère, et parfois travaillée par le vent à l'abord des crêtes. Sous 1400/1600 m et dans les versants ensoleillés, la neige s'est davantage alourdie, et peut être parfois croûtée. En journée, outre l'humidification qui peut reprendre au soleil, la neige récente subit de plus en plus les effets du vent de Sud, travaillée puis soufflée/arrachée vers les crêtes, dont certaines pourraient redevenir dégarnies. En toute fin de journée/soirée, quelques chutes de neige remontant du Sud peuvent commencer à déposer une fine couche de fraîche (de manière très irrégulière à cause du vent fort).

Aperçu météo pour le lundi 02 février

nuit	matin	après-midi	soir

Ciel devenant voilé puis très nuageux dans l'après-midi. Chutes de neige à partir de la fin de journée/soirée. Net renforcement du vent de Sud.

Pluie-Neige				1700 m
Iso 0 °C	1700 m	2100 m	2300 m	2200 m
Vent 2500 m	15 km/h	25 km/h	60 km/h	95 km/h
Vent 3500 m	25 km/h	40 km/h	70 km/h	110 km/h

Épaisseur de neige hors-piste

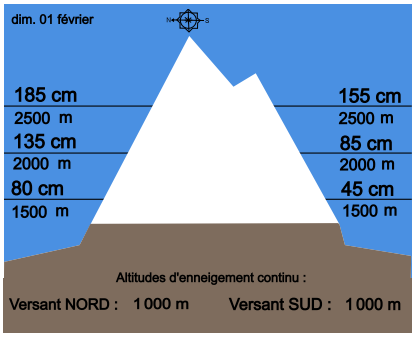

Précipitations à 1800 m

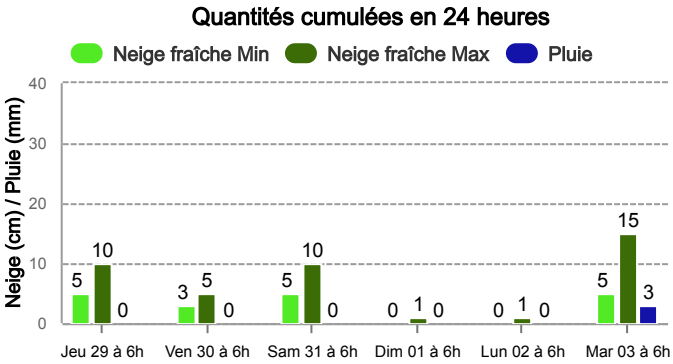

Tendance du mardi 03 février

Indice de risque fort

Mardi, risque en hausse sur le massif. Le vent de Sud et les chutes de neige auront formé et formeront de nombreuses instabilités réactives, qui pourront elles-même plus facilement solliciter les sous-couches fragiles enfouies par endroits dans le manteau neigeux.

Pour consulter la vigilance en cours, veuillez vous rendre sur le site https://vigilance.meteofrance.fr/fr

Météo-France - 73 avenue de Paris, 94165 Saint-Mandé cedex - Contact : contact@meteo.fr

Rédigé par Météo-France avec la contribution des observateurs du réseau nivo-météorologiques. Partenariat : ANMSM (Maires de Stations de Montagne), DSF (Domaines Skiables de France), ADSP (Directeurs de Pistes et de la Sécurité des Stations de Sports d'Hiver) et autres acteurs de la montagne.

Bulletin neige & avalanches par téléphone au

0 892 68 10 20 Service 0,35 € / min + prix appel

Bulletin d'estimation du risque d'avalanche

(valable en dehors des pistes balisées et ouvertes)

MASSIF : Oisans

Rédigé le dimanche 1 février 2026 à 16h

Conditions nivo-météo des 7 derniers jours

	lun. 26/01				mar. 27/01				mer. 28/01				jeu. 29/01				ven. 30/01				sam. 31/01				dim. 01/02			
	03h	09h	15h	21h	03h	09h	15h	21h	03h	09h	15h	21h	03h	09h	15h	21h	03h	09h	15h	21h	03h	09h	15h	21h	03h	09h	15h	21h
Météo																												
Vent (km/h)	30	45	45	20	35	85	100	100	15	20	45	60	45	30	30	45	45	30	30	20	20	15	15	20	20	20	25	20
à 3500m																												
Vent (km/h)	20	40	40	10	20	65	90	85	10	10	25	55	40	20	20	30	30	15	15	10	10	10	10	15	15	15	15	10
à 2500m																												

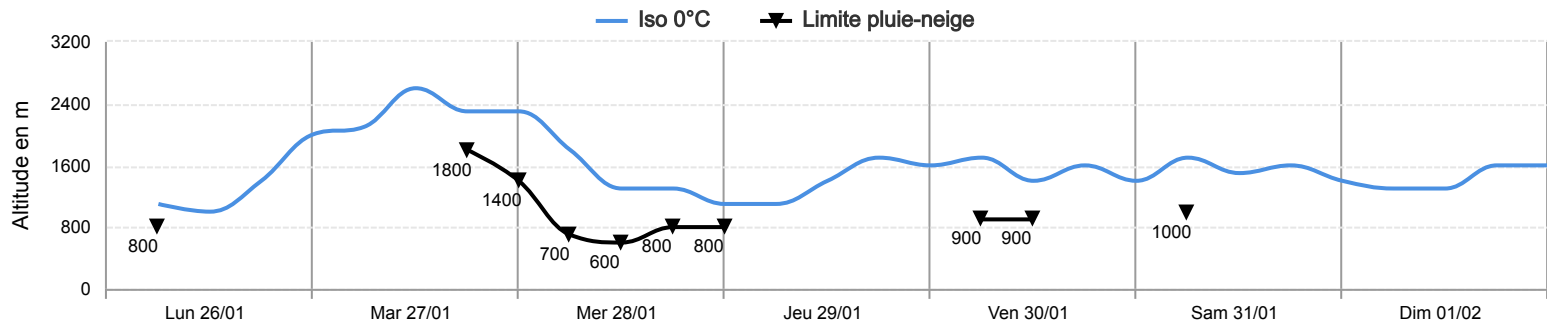

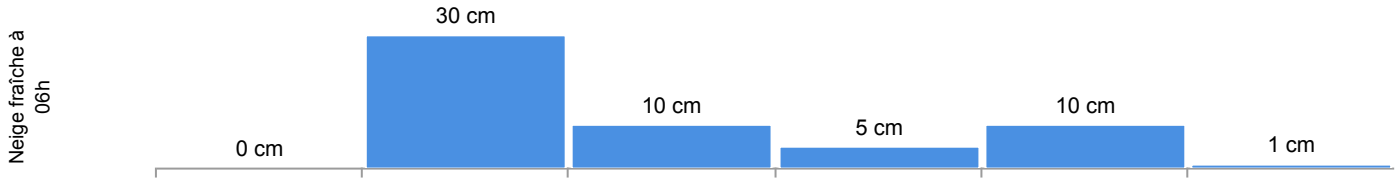

Risque d'avalanche	lun. 26/01	mar. 27/01	mer. 28/01	jeu. 29/01	ven. 30/01	sam. 31/01	dim. 01/02
	3	4	4	4	3	3	3

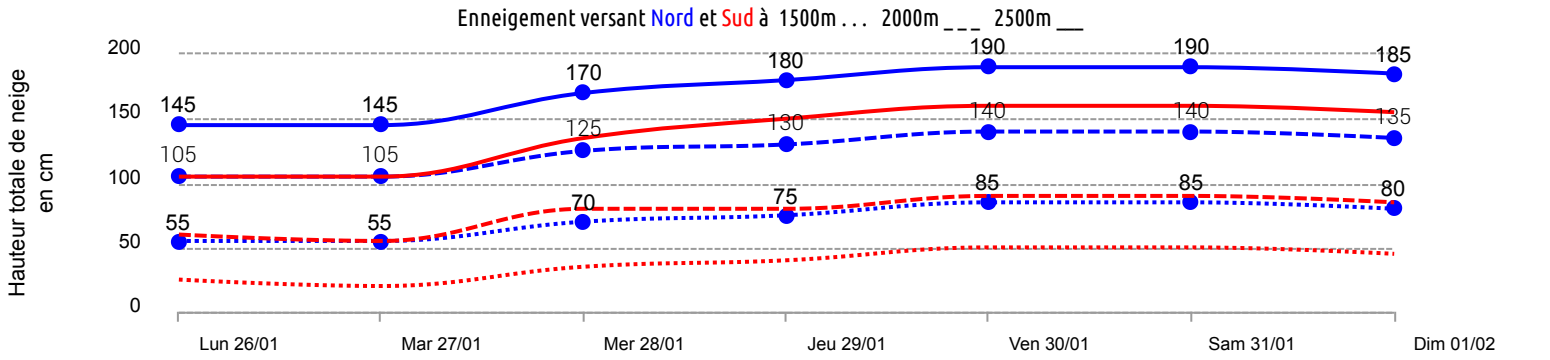

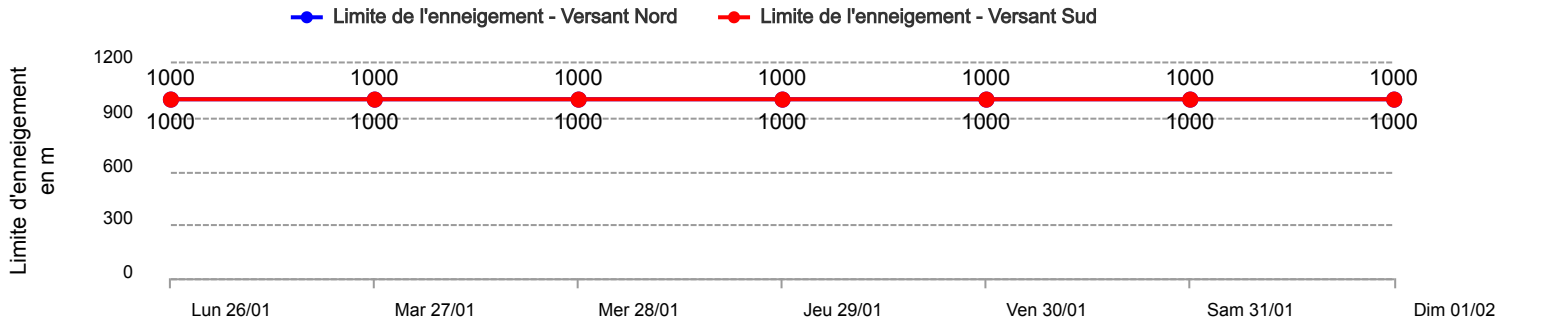

Pour consulter la vigilance en cours, veuillez vous rendre sur le site https://vigilance.meteofrance.fr/fr

Météo-France - 73 avenue de Paris, 94165 Saint-Mandé cedex - Contact : contact@meteo.fr

Bulletin neige & avalanches par téléphone au

0 892 68 10 20 Service 0,35 € / min + prix appel

Rédigé par Météo-France avec la contribution des observateurs du réseau nivo-météorologiques. Partenariat : ANMSM (Maires de Stations de Montagne), DSF (Domaines Skiables de France), ADSP (Directeurs de Pistes et de la Sécurité des Stations de Sports d'Hiver) et autres acteurs de la montagne.