# Bulletin d'estimation du risque d'avalanche
(valable en dehors des pistes balisées et ouvertes)

# MASSIF : Pays-Basque

Rédigé le dimanche 1 février 2026 à 16h

## Estimation des risques pour le : LUNDI 02 FÉVRIER

**NEIGE HUMIDE SOUS 2000 M, NEIGE VENTEE AU-DESSUS.**

3

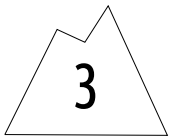


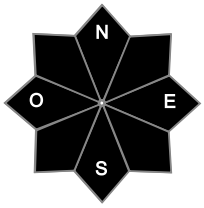


Neige ventée

Indice de risque marqué.

**Départs spontanés :** Nombreux départs linéaires et ponctuels en neige humide.

**Déclenchements provoqués :** Quelques plaques en formation lundi après-midi.

Indices de risque : 5 très fort - 4 fort - 3 marqué - 2 limité - 1 faible -- En noir : les pentes les plus dangereuses

## Stabilité du manteau neigeux

**Situation avalancheuse typique :** neige humide neige ventée

**Déclenchements provoqués :**
**Par déclenchement en cassure linéaire par un randonneur ou plusieurs, il peut résulter des avalanches de tailles petites à moyennes, rarement grandes en pentes nord d'accumulation.**
Des **plaques instables sont en place,** mais l'humidification les rend plus difficilement déclenchables cette nuit et surtout lundi. Après l'humidification jusqu'à lundi midi et avec les chutes neigeuses en après-midi, de nouvelles plaques ventées se forment lundi après-midi au-dessus de 1800 m puis 1600/1500 m, elles sont **moins facilement déclenchables que les jours précédents. Par déclenchement en cassure linéaire par un randonneur ou plusieurs, il peut résulter des avalanches de tailles petites à moyennes, rarement grandes en pentes nord d'accumulation.**

**Départs spontanés :**
L'humidification en cours se poursuit cette nuit et lundi midi jusqu'à 1900/2100 m. Des avalanches nombreuses sont à attendre cette nuit et surtout lundi, de taille petites à moyennes mais parfois grandes en versants Est à Sud. Avalanches ponctuelles en coulées en journée, mais aussi linéaires en pentes raides par glissement de fond lorsque l'humidification atteint le sol pour les plaques en place. Des coulées peuvent parfois glisser jusqu'à certaines routes de montagne en secteur basque.

## Qualité de la neige

**Enneigement** : L'enneigement est assez bon pour la saison, mais les crêtes, cols et sommets sont souvent pelés par le vent en altitude dans les expositions ouest. Sous 1800/1600 m le manteau neigeux prend la pluie et tend à se réduire fortement en après-midi ce lundi.
**Limites skiables** : Manteau neigeux skiable à partir de 1300 m le matin, 1800 m en après-midi.
**État de la neige** : Neige souvent cartonnée en pentes ouest et nord, friable à croûtée au petit matin mais probablement non portante. Neige récente sur une épaisseur moyenne de 20 à 35 cm mais s'humidifiant. Neige très ventée qui s'est accumulée sous le vent d'ouest à nord.

## Aperçu météo pour le lundi 02 février

| | nuit | matin | après-midi | soir |
|---|---|---|---|---|
| | | | | |

Ciel dégagé cette nuit puis plus nuageux avec de faibles ondées. Redoux, chutes de neige marquées lundi après-midi en frontalier au-dessus de 1800 m.

| | | | | |
|---|---|---|---|---|
| **Pluie-Neige** | 1 900 m | 2 000 m | 1 700 m | 1 500 m |
| **Iso 0 °C** | 2 600 m | 2 900 m | 2 300 m | 1 800 m |
| **Vent 1000 m** | ↑ 60 km/h | ↑ 90 km/h | ↑ 90 km/h | ↗ 55 km/h |
| **Vent 2000 m** | ↑ 95 km/h | ↑ 120 km/h | ↑ 120 km/h | ↗ 80 km/h |

## Épaisseur de neige hors-piste

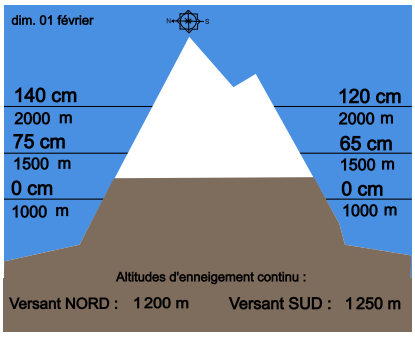


## Précipitations à 1800 m

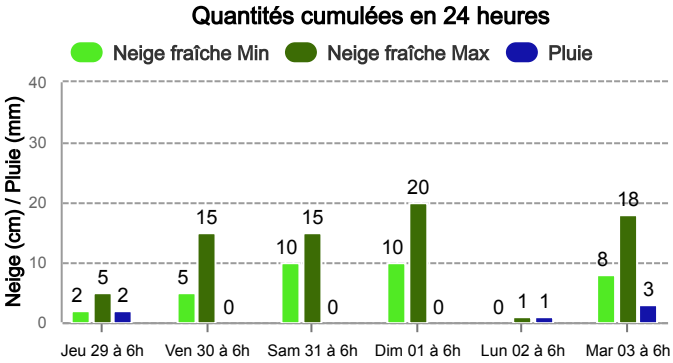


## Tendance du mardi 03 février

**Indice de risque limité**

Stabilisation par humidification sous 1800 m, quelques plaques au-dessus.

Pour consulter la vigilance en cours, veuillez vous rendre sur le site https://vigilance.meteofrance.fr/fr

Météo-France - 73 avenue de Paris, 94165 Saint-Mandé cedex - Contact : contact@meteo.fr

Rédigé par Météo-France avec la contribution des observateurs du réseau nivo-météorologiques. Partenariat : ANMSM (Maires de Stations de Montagne), DSF (Domaines Skiables de France), ADSP (Directeurs de Pistes et de la Sécurité des Stations de Sports d'Hiver) et autres acteurs de la montagne.

Bulletin neige & avalanches par téléphone au
0 892 68 10 20 Service 0,35 € / min + prix appel

# Bulletin d'estimation du risque d'avalanche

(valable en dehors des pistes balisées et ouvertes)

# MASSIF : Pays-Basque

Rédigé le dimanche 1 février 2026 à 16h

## Conditions nivo-météo des 7 derniers jours

| | lun. 26/01 | | | | mar. 27/01 | | | | mer. 28/01 | | | | jeu. 29/01 | | | | ven. 30/01 | | | | sam. 31/01 | | | | dim. 01/02 | | | |
|---|---|---|---|---|---|---|---|---|---|---|---|---|---|---|---|---|---|---|---|---|---|---|---|---|---|---|---|---|
| | 03h | 09h | 15h | 21h | 03h | 09h | 15h | 21h | 03h | 09h | 15h | 21h | 03h | 09h | 15h | 21h | 03h | 09h | 15h | 21h | 03h | 09h | 15h | 21h | 03h | 09h | 15h | 21h |
| Météo | | | | | | | | | | | | | | | | | | | | | | | | | | | | |
| Vent (km/h) | 90 | 80 | 55 | 90 | 110 | 75 | 70 | 55 | 40 | 40 | 55 | 60 | 65 | 80 | 75 | 75 | 80 | 95 | 65 | 80 | 70 | 90 | 90 | 60 | 70 | 45 | 50 | 80 |
| à 2000m | | | | | | | | | | | | | | | | | | | | | | | | | | | | |
| Vent (km/h) | 35 | 20 | 20 | 30 | 80 | 50 | 35 | 20 | 15 | 10 | 25 | 35 | 45 | 50 | 50 | 50 | 50 | 65 | 40 | 50 | 50 | 70 | 70 | 35 | 30 | 30 | 40 | 60 |
| à 1000m | | | | | | | | | | | | | | | | | | | | | | | | | | | | |

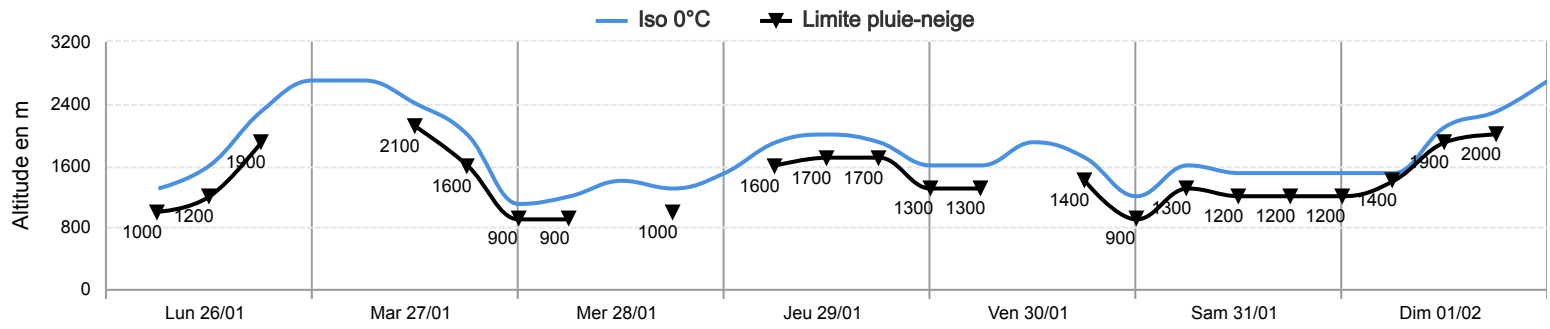


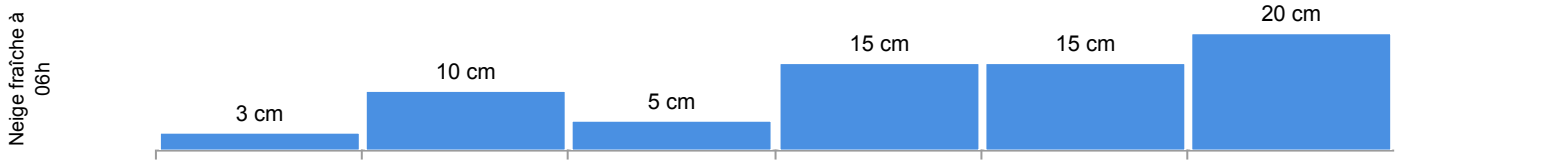


| Risque d'avalanche | lun. 26/01 | mar. 27/01 | mer. 28/01 | jeu. 29/01 | ven. 30/01 | sam. 31/01 | dim. 01/02 |
|---|---|---|---|---|---|---|---|
| | 3 | 3 | 2 | 2 | 3 | 4 | 3 |

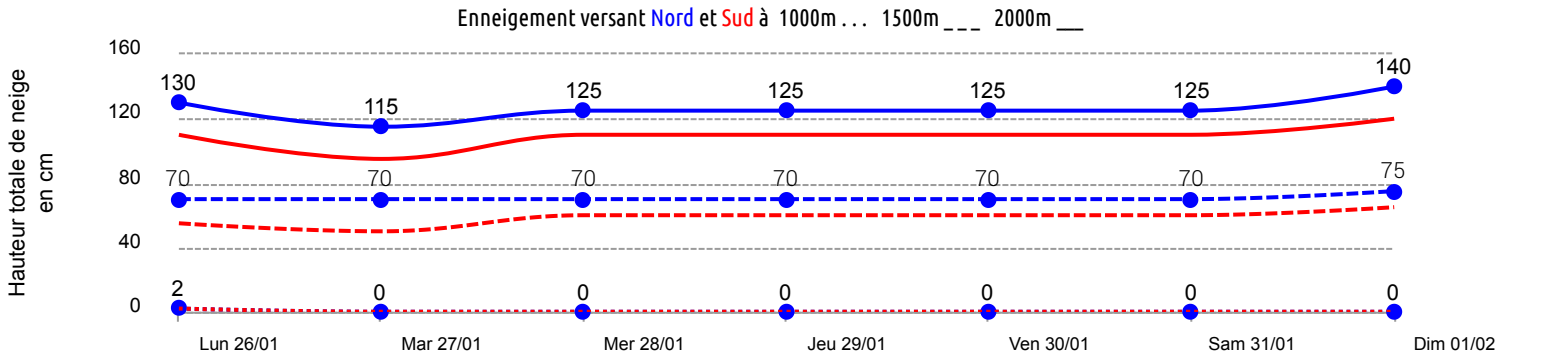


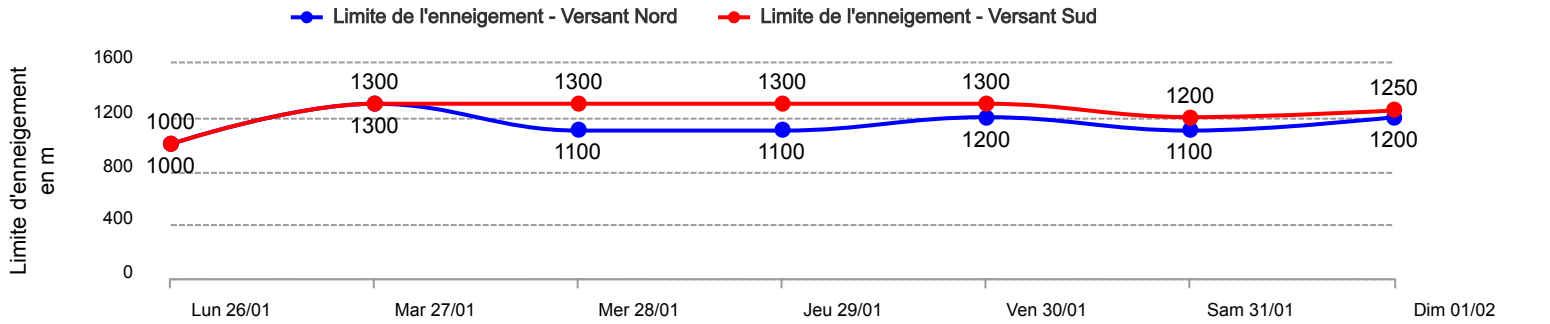


Pour consulter la vigilance en cours, veuillez vous rendre sur le site https://vigilance.meteofrance.fr/fr


Météo-France - 73 avenue de Paris, 94165 Saint-Mandé cedex - Contact : contact@meteo.fr


Rédigé par Météo-France avec la contribution des observateurs du réseau nivo-météorologiques. Partenariat : ANMSM (Maires de Stations de Montagne), DSF (Domaines Skiables de France), ADSP (Directeurs de Pistes et de la Sécurité des Stations de Sports d'Hiver) et autres acteurs de la montagne.


Bulletin neige & avalanches par téléphone au

0 892 68 10 20 Service 0,35 € / min + prix appel