Bulletin d'estimation du risque d'avalanche
(valable en dehors des pistes balisées et ouvertes)

MASSIF : Renoso Incudine

Rédigé le dimanche 1 février 2026 à 16h

Estimation des risques pour le : LUNDI 02 FÉVRIER

MANTEAU NEIGEUX QUI PEINE À SE STABILISER, PERSISTANCE DE NOMBREUSES PLAQUES ÉPAISSES EN ALTITUDE

3

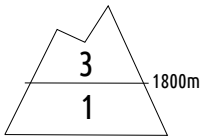

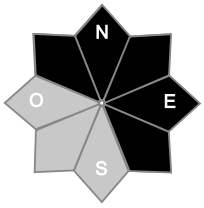

Au-dessus de 1800m indice de risque marqué, plus bas indice faible.

Départs spontanés : Rares coulées ou avalanches superficielles dans les pentes raides

Déclenchements provoqués : Au-dessus de 1800 à 2000m, persistance de nombreuses plaques, épaisses, faciles à déclencher

Indices de risque : 5 très fort - 4 fort - 3 marqué - 2 limité - 1 faible -- En noir : les pentes les plus dangereuses

Stabilité du manteau neigeux

Situation avalancheuse typique : neige ventée couche fragile persistante

Déclenchements provoqués : Au-dessus de 1800 à 2000 m, nombreuses plaques en place dans le manteau neigeux, composé de plusieurs couches fragiles (neige froide des derniers jours, présence de neige roulée et localement vieille neige sans cohésion plus enfouie). Ces plaques sont dures à cause du vent fort, friables plus à l'abri du vent. Elles sont épaisses dans les zones d'accumulation, dans les orientations Nord à Sud-Est à l'abri des vents des jours passés. Une faible sollicitation peut donc être suffisante pour déclencher des avalanches moyennes et même grandes (taille 2 à 3) dans les pentes raides, parfois loin des crêtes. Dans les autres versants, avec une neige très travaillée par les vents, les plaques sont moins épaisses et les avalanches sont plutôt moyennes (taille 2). Le tassement des couches et la hausse progressive des températures permettent un début de stabilisation.
En dessous de 1800 m, les plaques sont plus rares, peu épaisses et généralement plus difficiles à solliciter.

Départs spontanés : Sans précipitations significatives, on n'attend que de rares coulées ou avalanches superficielles, localisées dans les pentes raides en neige récente sèche, ou dans les pentes ensoleillées en neige en voie d'humidification.

Qualité de la neige

Qualification de l'enneigement : Enneigement excellent pour la saison à toutes altitudes, avec des cumuls de neige récente atteignant ponctuellement les 40/60 cm en moyenne montagne et plus de 2 mètres dans les combes abritées.
Limite d'enneigement skiable : Vers 1400/1500 m.
État de la neige : La neige récente est encore sèche et plutôt légère, localement humidifiée ou croûtée en dessous de 1800m. Mais le vent soutenu qui a accompagné les différentes chutes rend l'enneigement toujours très hétérogène. La neige est froide et poudreuse à l'abri du vent, elle devient plus compacte, voire cartonnée dans les secteurs ventés. Des anciennes surfaces, souvent dures et glacées, réapparaissent près des crêtes.

Aperçu météo pour le lundi 02 février

nuit	matin	après-midi	soir

Redoux progressif, qui tend à humidifier la neige de surface dans les orientations Sud.

Pluie-Neige				
Iso 0 °C	1 600 m	2 000 m	2 300 m	2 600 m
Vent 1500 m	→ 40 km/h	→ 20 km/h	↗ 20 km/h	↑ 25 km/h
Vent 2000 m	→ 40 km/h	→ 25 km/h	↗ 25 km/h	↑ 30 km/h

Épaisseur de neige hors-piste

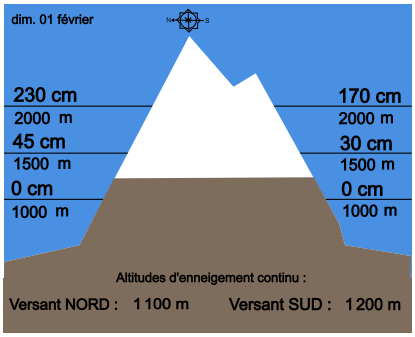

Précipitations à 1800 m

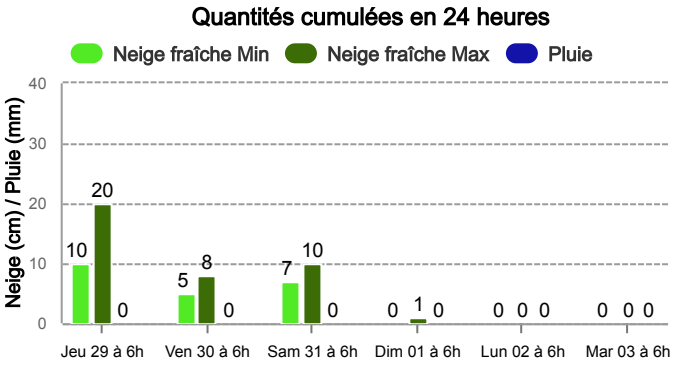

Tendance du mardi 03 février

3 **Indice de risque marqué**

Maintien d'un risque marqué. Des chutes de neige sont attendues au-dessus de 1800/2000m, engendrant de nouvelles instabilités ainsi que des coulées et avalanches de neige fraîche. Les plaques restent nombreuses, épaisses et faciles à déclencher. En moyenne montagne, le redoux et la pluie engendrent d'abord des départs en neige humide, puis une stabilisation du manteau neigeux.

Pour consulter la vigilance en cours, veuillez vous rendre sur le site https://vigilance.meteofrance.fr/fr

Météo-France - 73 avenue de Paris, 94165 Saint-Mandé cedex - Contact : contact@meteo.fr

Rédigé par Météo-France avec la contribution des observateurs du réseau nivo-météorologiques. Partenariat : ANMSM (Maires de Stations de Montagne), DSF (Domaines Skiables de France), ADSP (Directeurs de Pistes et de la Sécurité des Stations de Sports d'Hiver) et autres acteurs de la montagne.

Bulletin neige & avalanches par téléphone au 0 892 68 10 20 Service 0,35 € / min + prix appel

RÉPUBLIQUE FRANÇAISE
Liberté Égalité Fraternité

METEO FRANCE
À VOS CÔTÉS, DANS UN CLIMAT QUI CHANGE

Bulletin d'estimation du risque d'avalanche

(valable en dehors des pistes balisées et ouvertes)

MASSIF : Renoso Incudine

Rédigé le dimanche 1 février 2026 à 16h

Conditions nivo-météo des 7 derniers jours

	lun. 26/01				mar. 27/01				mer. 28/01				jeu. 29/01				ven. 30/01				sam. 31/01				dim. 01/02			
	03h	09h	15h	21h	03h	09h	15h	21h	03h	09h	15h	21h	03h	09h	15h	21h	03h	09h	15h	21h	03h	09h	15h	21h	03h	09h	15h	21h
Météo																												
Vent (km/h)	45	35	20	20	20	30	40	60	70	80	65	60	50	60	70	60	40	50	60	70	40	45	50	30	35	25	30	30
à 2000m																												
Vent (km/h)	55	45	20	15	15	20	35	60	70	70	60	50	50	60	70	45	40	40	50	60	30	40	40	25	30	20	20	20
à 1500m																												

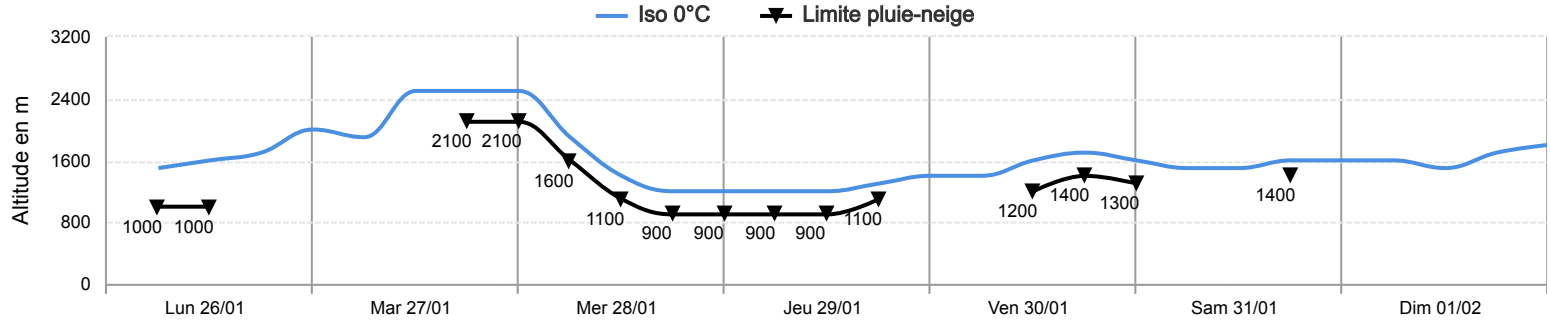

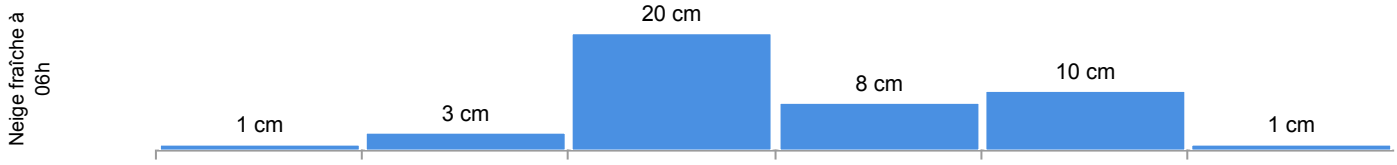

Risque d'avalanche	lun. 26/01	mar. 27/01	mer. 28/01	jeu. 29/01	ven. 30/01	sam. 31/01	dim. 01/02
	3	3	4	4	3	3	3

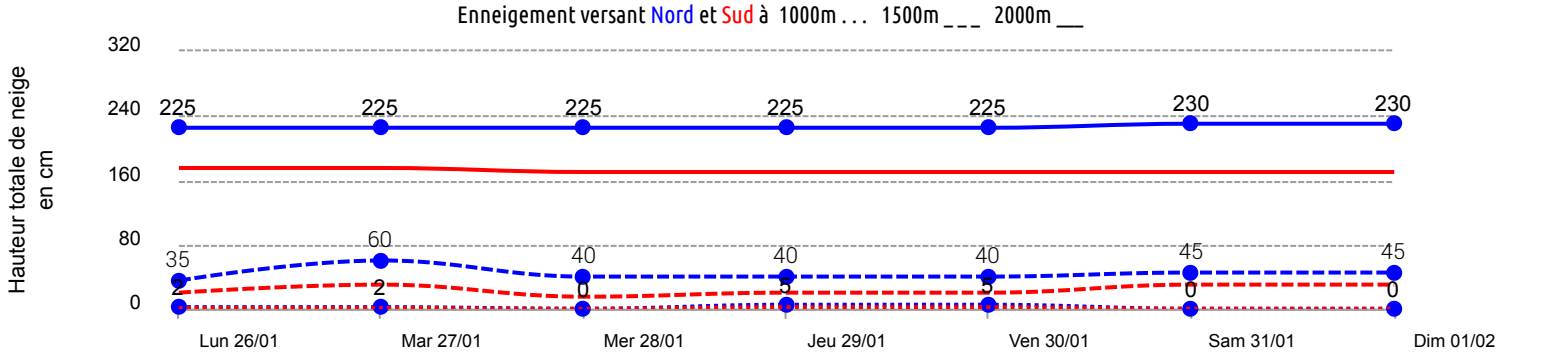

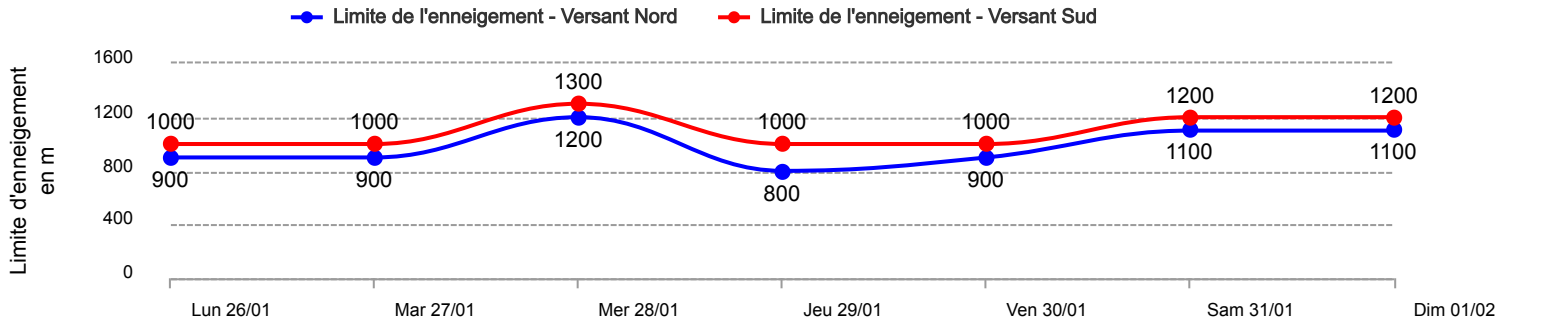

Pour consulter la vigilance en cours, veuillez vous rendre sur le site https://vigilance.meteofrance.fr/fr

Météo-France - 73 avenue de Paris, 94165 Saint-Mandé cedex - Contact : contact@meteo.fr

Rédigé par Météo-France avec la contribution des observateurs du réseau nivo-météorologiques. Partenariat : ANMSM (Maires de Stations de Montagne), DSF (Domaines Skiables de France), ADSP (Directeurs de Pistes et de la Sécurité des Stations de Sports d'Hiver) et autres acteurs de la montagne.

Bulletin neige & avalanches par téléphone au
0 892 68 10 20 Service 0,35 € / min + prix appel