Bulletin d'estimation du risque d'avalanche
(valable en dehors des pistes balisées et ouvertes)

MASSIF : Ubaye

Rédigé le dimanche 1 février 2026 à 16h

Estimation des risques pour le : LUNDI 02 FÉVRIER

RISQUE MARQUÉ DE DÉCLENCHEMENT ACCIDENTEL : NOMBREUSES INSTABILITÉS LOCALEMENT INSTABLES ET VOLUMINEUSES EN UBACS, SURTOUT EN HAUTE-UBAYE.

3

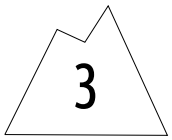

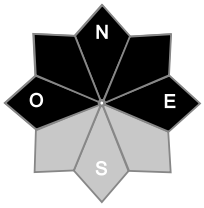

Indice de risque marqué.

Départs spontanés : rares départs en neige fraiche ventée en soirée.

Déclenchements provoqués : instabilités encore fréquentes et faciles à déclencher en ubacs

Indices de risque : 5 très fort - 4 fort - 3 marqué - 2 limité - 1 faible -- En noir : les pentes les plus dangereuses

Stabilité du manteau neigeux

Situation avalancheuse typique : couche fragile persistante — neige ventée

Déclenchements provoqués :
De nombreuses plaques sont en place dans la couche de neige récente en versant est, nord et ouest, notamment au-dessus de 1800/2000 en Haute-Ubaye, où elle repose sur des sous-couches fragiles persistantes peu enfouies.
Plaques d'aspect friables, déclenchables à distance par un seul skieur, possibles dans toutes les pentes supérieures à 30 degrés, même en forêts, et générant des avalanches de taille moyenne, rarement grande (taille 2 à 3).

D'autres parts, quelques plaques à vent sont possibles dans la neige récente en toutes orientations, notamment en fin de journée avec le retour des chutes de neige et le renforcement du vent. Avalanche de taille petite à moyenne (taille 1 à 2), rarement grande (taille 3).

Départs spontanés : quelques boulettes au soleil en matinée. Rares départs de neige fraiche ventée en fin de journée, de taille petite à moyenne.

Qualité de la neige

Enneigement globalement normale pour une fin janvier.
Données observées : 87 cm au-dessus de Larche à 2270 m, 17 cm à Barcelonnette.

Enneigement skiable dès 1200/1300 m en terrain favorable, mais peu de sous-couche sous 1600 m en général.

État de la neige en surface : épaisse couche de neige récente : 20/30 cm à 1500 m, 30/40 cm à partir de 1800 m, localement 50 cm en bordure du Verdon et de la Tinée. Cette neige est légèrement croutée en surface sous 1500/2100 m selon les orientations, souvent encore froide et légère au-dessus, localement travaillée par le vent en altitude. Corniches parfois volumineuses en place sur les crêtes.

Aperçu météo pour le lundi 02 février

	nuit	matin	après-midi	soir
Éclaircies le matin avant l'arrivée de faibles chute de neige l'après-midi, se renforçant en soirée.				
Pluie-Neige			1 300 m	1 500 m
Iso 0 °C	1 500 m	1 700 m	1 900 m	2 000 m
Vent 2000 m	10 km/h	15 km/h	20 km/h	30 km/h
Vent 3000 m	20 km/h	25 km/h	35 km/h	50 km/h

Épaisseur de neige hors-piste

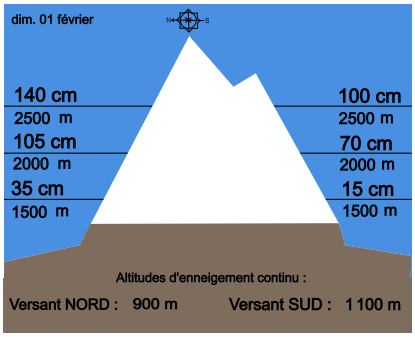

Précipitations à 1800 m

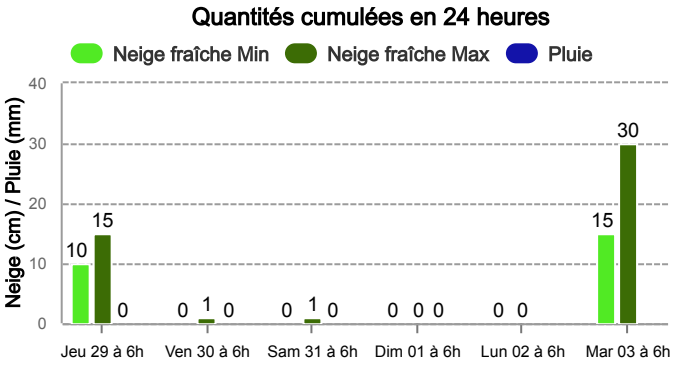

Tendance du mardi 03 février

4

Indice de risque fort

Risque devenant fort en cours de nuit de lundi à mardi avec les importantes chutes de neige. Forte instabilité du manteau neigeux et nombreux départs spontanés volumineux attendus.

Pour consulter la vigilance en cours, veuillez vous rendre sur le site https://vigilance.meteofrance.fr/fr

Météo-France - 73 avenue de Paris, 94165 Saint-Mandé cedex - Contact : contact@meteo.fr

Rédigé par Météo-France avec la contribution des observateurs du réseau nivo-météorologiques. Partenariat : ANMSM (Maires de Stations de Montagne), DSF (Domaines Skiables de France), ADSP (Directeurs de Pistes et de la Sécurité des Stations de Sports d'Hiver) et autres acteurs de la montagne.

Bulletin neige & avalanches par téléphone au
0 892 68 10 20 Service 0,35 € / min + prix appel

RÉPUBLIQUE FRANÇAISE
Liberté Égalité Fraternité

METEO FRANCE
À VOS CÔTÉS, DANS UN CLIMAT QUI CHANGE

Bulletin d'estimation du risque d'avalanche

(valable en dehors des pistes balisées et ouvertes)

MASSIF : Ubaye

Rédigé le dimanche 1 février 2026 à 16h

Conditions nivo-météo des 7 derniers jours

	lun. 26/01				mar. 27/01				mer. 28/01				jeu. 29/01				ven. 30/01				sam. 31/01				dim. 01/02			
	03h	09h	15h	21h	03h	09h	15h	21h	03h	09h	15h	21h	03h	09h	15h	21h	03h	09h	15h	21h	03h	09h	15h	21h	03h	09h	15h	21h
Météo																												
Vent (km/h)	30	30	30	20	40	55	60	60	50	35	15	30	45	40	25	20	30	40	30	20	25	15	20	15	15	15	15	20
à 3000m																												
Vent (km/h)	20	15	10	10	10	15	20	30	25	20	10	15	20	15	20	10	10	15	20	5	5	5	15	10	10	10	15	10
à 2000m																												

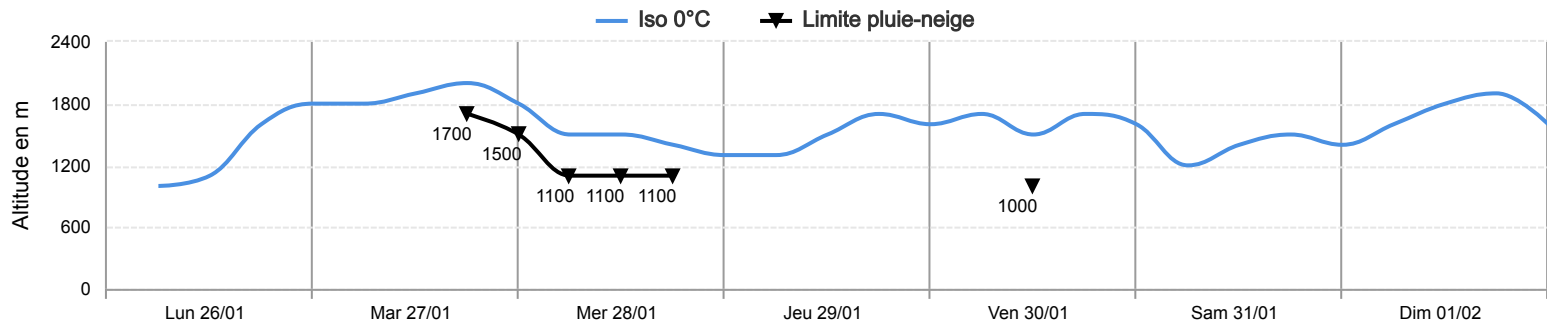

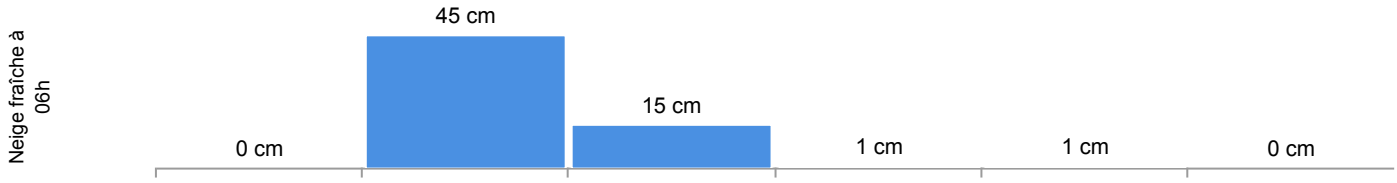

Risque d'avalanche	lun. 26/01	mar. 27/01	mer. 28/01	jeu. 29/01	ven. 30/01	sam. 31/01	dim. 01/02
	3	4	4	4	4	3	3

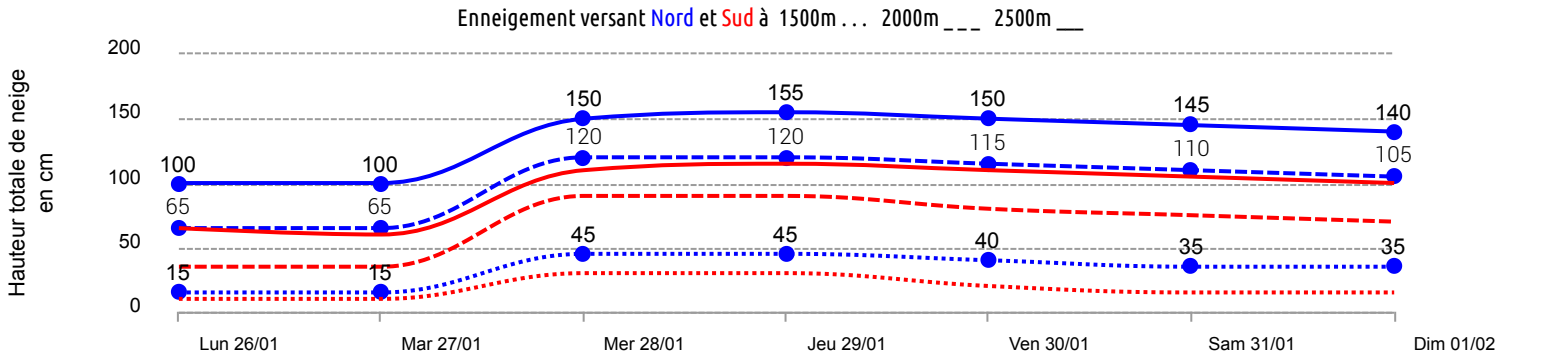

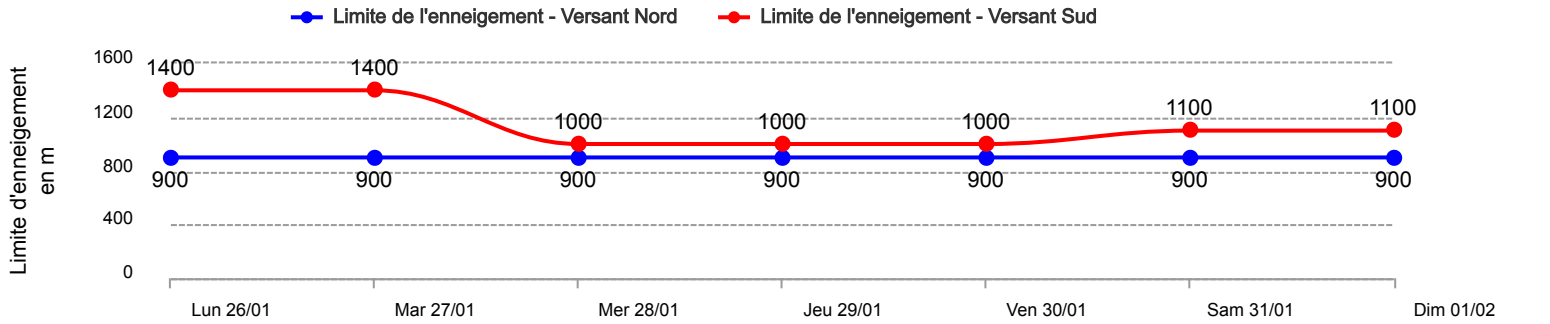

Pour consulter la vigilance en cours, veuillez vous rendre sur le site https://vigilance.meteofrance.fr/fr

Météo-France - 73 avenue de Paris, 94165 Saint-Mandé cedex - Contact : contact@meteo.fr

Rédigé par Météo-France avec la contribution des observateurs du réseau nivo-météorologiques. Partenariat : ANMSM (Maires de Stations de Montagne), DSF (Domaines Skiables de France), ADSP (Directeurs de Pistes et de la Sécurité des Stations de Sports d'Hiver) et autres acteurs de la montagne.

Bulletin neige & avalanches par téléphone au
0 892 68 10 20 Service 0,35 € / min + prix appel