Bulletin d'estimation du risque d'avalanche
(valable en dehors des pistes balisées et ouvertes)

MASSIF : Vercors

Rédigé le dimanche 1 février 2026 à 16h

Estimation des risques pour le : LUNDI 02 FÉVRIER

FORMATION DE NOUVELLES INSTABILITÉS DANS LES VERSANTS FROIDS, SOUS LE VENT DE SUD QUI SE RENFORCE CE LUNDI.

3

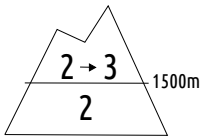

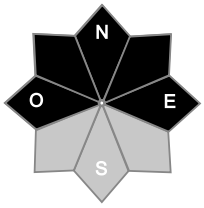

vent de Sud

Au-dessus de 1500m indice de risque limité évoluant en marqué, plus bas indice limité.

Départs spontanés : Rares avalanches humides en pentes "réchauffées".

Déclenchements provoqués : Nouvelles instabilités sous le vent de Sud dans les versants froids d'altitude, devenant plus nombreuses l'après-midi et le soir.

Indices de risque : 5 très fort - 4 fort - 3 marqué - 2 limité - 1 faible -- En noir : les pentes les plus dangereuses

Stabilité du manteau neigeux

Situation avalancheuse typique : neige ventée

Déclenchements provoqués : Risque en augmentation au fil de la journée de lundi. Dans les versants d'un large Nord, de nouvelles instabilités vont se former dans la neige récente restée légère, avec le vent de Sud qui se renforce en cours de journée. D'abord très locales et peu épaisses en première partie de journée, elles se font de plus en plus nombreuses au fil des heures et notamment dans l'après-midi. Ces nouvelles plaques sont situées dans les zones d'accumulation par le vent, à proximité des crêtes dans un premier temps, puis le risque augmente également dans les bas de pentes et plus loin des crêtes au fur et à mesure que le vent forcit. Elles peuvent être réactives et faciles à déclencher par un seul pratiquant. Sous 1400/1600 m environ, le risque devrait rester plus limité, la neige récente s'étant davantage alourdie/humidifiée.

Départs spontanés : En journée de lundi, de rares avalanches de neige humide de taille 1 à 2 (petites à moyennes) ne sont pas exclues dans la neige récente qui s'humidifie, notamment dans les pentes raides qui seront exposées au soleil et près des rochers.

Qualité de la neige

Qualification de l'enneigement : L'enneigement s'est récemment amélioré et est redevenu correct voire bon pour la saison, notamment en prairies/pistes forestières. Le vent de Sud attendu va dégrader la situation aux basses altitudes.

Limites skiables : vers 900/1200 m, hors sapins.

Qualité de la neige lundi : Neige récente en cours de tassement, encore un peu légère en pentes Nord d'altitude et s'étant alourdie/humidifiée sous 1400/1600 m et dans les versants ensoleillés, où elle est parfois croûtée. En journée, outre l'humidification qui peut reprendre au soleil, la neige récente subit de plus en plus les effets du vent de Sud, travaillée puis soufflée/arrachée vers les crêtes, dont certaines pourraient redevenir dégarnies. En toute fin de journée/soirée, des chutes de neige remontant du Sud peuvent commencer à déposer une petite couche de fraîche (de manière très irrégulière à cause du vent fort).

Aperçu météo pour le lundi 02 février

nuit	matin	après-midi	soir

Ciel devenant voilé puis très nuageux dans l'après-midi. Chutes de neige à partir de la fin de journée/soirée. Net renforcement du vent de Sud.

Pluie-Neige				1 800 m
Iso 0 °C	1 600 m	2 200 m	2 300 m	2 200 m
Vent 1500 m	↑ 15 km/h	↑ 35 km/h	↑ 65 km/h	↑ 100 km/h
Vent 2000 m	↑ 25 km/h	↑ 55 km/h	↑ 80 km/h	↑ 120 km/h

Épaisseur de neige hors-piste

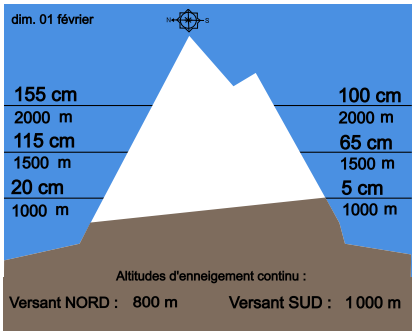

Précipitations à 1800 m

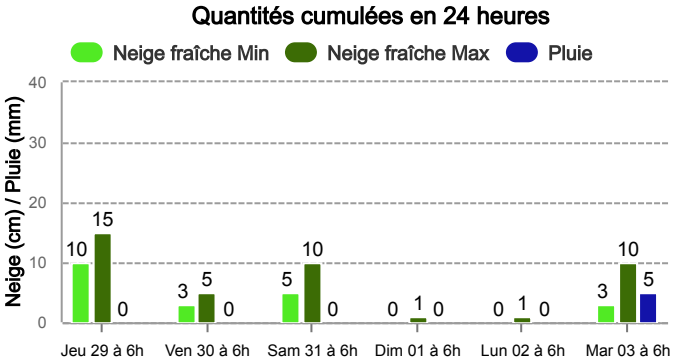

Tendance du mardi 03 février

3 **Indice de risque marqué**

Mardi, risque restant de niveau marqué. Le vent de Sud et les chutes de neige auront formé et formeront de nombreuses instabilités réactives.

Pour consulter la vigilance en cours, veuillez vous rendre sur le site https://vigilance.meteofrance.fr/fr

Météo-France - 73 avenue de Paris, 94165 Saint-Mandé cedex - Contact : contact@meteo.fr

Rédigé par Météo-France avec la contribution des observateurs du réseau nivo-météorologiques. Partenariat : ANMSM (Maires de Stations de Montagne), DSF (Domaines Skiables de France), ADSP (Directeurs de Pistes et de la Sécurité des Stations de Sports d'Hiver) et autres acteurs de la montagne.

Bulletin neige & avalanches par téléphone au
0 892 68 10 20 Service 0,35 € / min + prix appel

RÉPUBLIQUE FRANÇAISE
Liberté Égalité Fraternité

METEO FRANCE
À VOS CÔTÉS, DANS UN CLIMAT QUI CHANGE

Bulletin d'estimation du risque d'avalanche

(valable en dehors des pistes balisées et ouvertes)

MASSIF : Vercors

Rédigé le dimanche 1 février 2026 à 16h

Conditions nivo-météo des 7 derniers jours

	lun. 26/01				mar. 27/01				mer. 28/01				jeu. 29/01				ven. 30/01				sam. 31/01				dim. 01/02			
	03h	09h	15h	21h	03h	09h	15h	21h	03h	09h	15h	21h	03h	09h	15h	21h	03h	09h	15h	21h	03h	09h	15h	21h	03h	09h	15h	21h
Météo																												
Vent (km/h)	35	55	50	20	70	90	100	90	20	30	40	45	45	25	15	30	45	35	25	20	20	15	20	20	20	20	20	20
à 2000m	↘	↓	↓	↙	↑	↑	↑	↑	↑	↓	↓	↓	↓	↓	↘	→	↗	↓	↓	↑	↑	↑	↗	→	↓	↙	↓	↗
Vent (km/h)	25	45	40	10	40	75	90	80	10	15	15	15	20	5	0	15	30	20	15	15	15	10	15	10	15	15	15	15
à 1500m	↓	↓	↙	↗	↑	↑	↑	↑	↓	↙	↙	↓	↙	←	↘	→	↗	↗	↑	↑	↑	↙	↗	↘	↓	↓	↘	↑

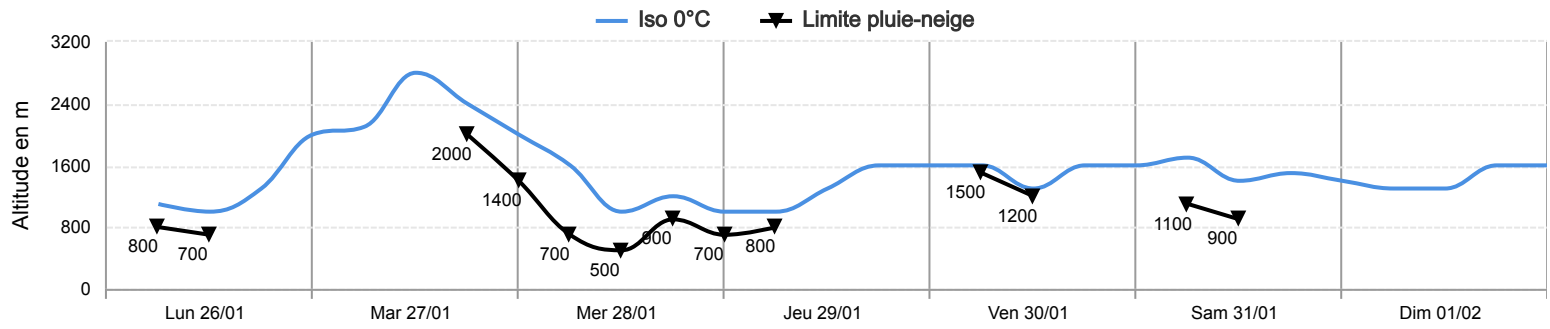

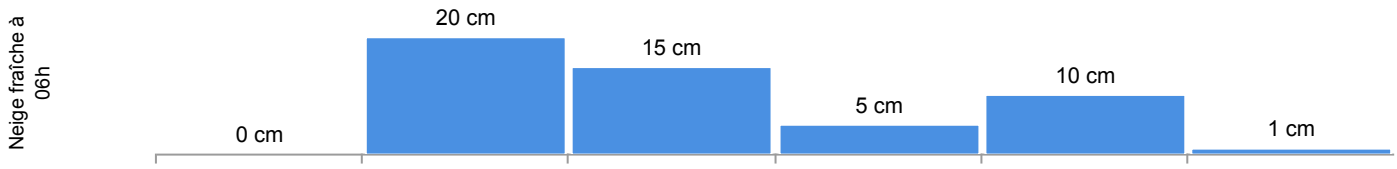

Risque d'avalanche	lun. 26/01	mar. 27/01	mer. 28/01	jeu. 29/01	ven. 30/01	sam. 31/01	dim. 01/02
	2	3	3	3	3	2	2

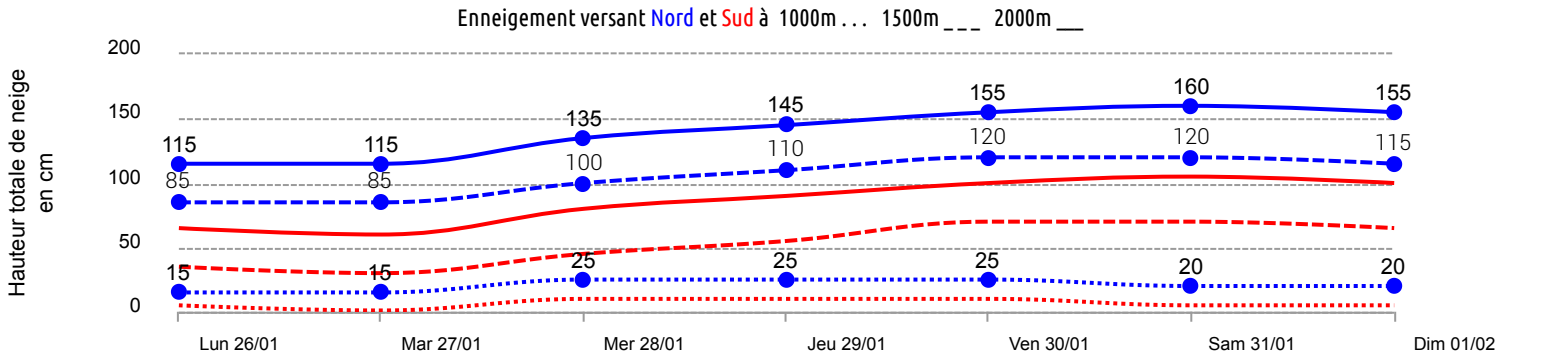

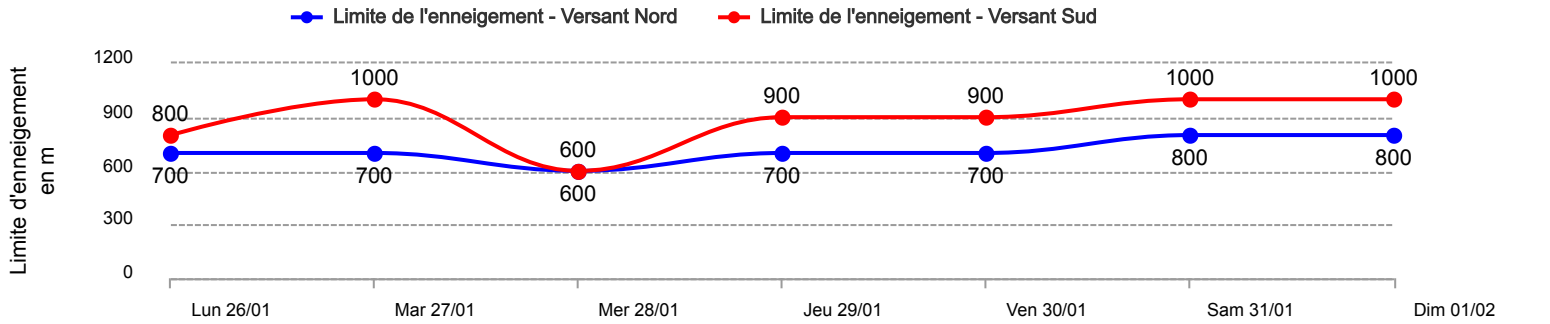

Pour consulter la vigilance en cours, veuillez vous rendre sur le site https://vigilance.meteofrance.fr/fr

Météo-France - 73 avenue de Paris, 94165 Saint-Mandé cedex - Contact : contact@meteo.fr

Bulletin neige & avalanches par téléphone au

0 892 68 10 20 Service 0,35 € / min + prix appel

Rédigé par Météo-France avec la contribution des observateurs du réseau nivo-météorologiques. Partenariat : ANMSM (Maires de Stations de Montagne), DSF (Domaines Skiables de France), ADSP (Directeurs de Pistes et de la Sécurité des Stations de Sports d'Hiver) et autres acteurs de la montagne.