Bulletin d'estimation du risque d'avalanche

(valable en dehors des pistes balisées et ouvertes)

MASSIF : Beaufortain

Rédigé le dimanche 1 février 2026 à 17h

Estimation des risques pour le : LUNDI 02 FÉVRIER

FORMATION DE NOUVELLES PLAQUES À VENT, COUCHE FRAGILE ENFOUIE DANS LES VERSANTS FROIDS.

3

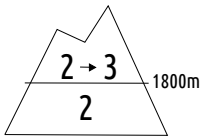

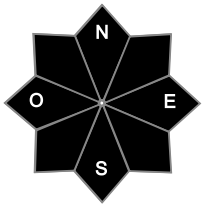

Au-dessus de 1800m indice de risque limité évoluant en marqué, plus bas indice limité.

Départs spontanés : rares départs linéaires plutôt en deuxième partie de journée.

Déclenchements provoqués : quelques plaques réactives en formation sous le foehn. Couche fragile persistante dans les versants ombragés.

Indices de risque : 5 très fort - 4 fort - 3 marqué - 2 limité - 1 faible -- En noir : les pentes les plus dangereuses

Stabilité du manteau neigeux

Situation avalancheuse typique : neige ventée couche fragile persistante

Déclenchements provoqués :

(1) **Quelques plaques friables en formation sous le foehn** qui forcit au fil de la journée. Ces plaques sont **de plus en plus réactives et épaisses**, et se retrouvent aussi bien près des crêtes qu'en pied de pentes. Tailles 2 (moyennes) avec **cassures de 20/40 cm** d'ici la fin de journée. Seules les pentes Sud raides sous 2000/2200 m d'altitude seront moins réactives car la neige y est transformée. *Observables : indices de transport, neige un peu plus ferme sous les skis.*

(2) La **couche fragile persistante (grains anguleux), enfouie** depuis plusieurs semaine, **est toujours présente dans les pentes Nord/Est/Ouest dès 1800 m.** Elle vient former une épaisse structure de plaque qui, en cas de déclenchement, entraîne l'ensemble du manteau neigeux. Déclenchement souvent difficile, encore très localement possible à distance, provoquant des avalanches de taille 3 (grandes), avec des cassures d'1 à 2 m. *Observables : woumfs, tests CT/ECT.*

Une première avalanche dans la neige ventée (1) pourrait mobiliser en cascade la couche fragile enfouie (2).

Départs spontanés : au fil de la journée et du vent qui forcit, quelques petits départs linéaires peuvent se produire spontanément. Une rare taille 2 est possible, mais il n'est alors pas exclu que cette première avalanche *moyenne* vienne mobiliser en cascade les vieilles couches fragiles enfouies, engendrant alors une taille 3.

Qualité de la neige

Enneigement : l'enneigement est désormais globalement normal. Les petites chutes de neige tout au long de la semaine ont maintenu l'enneigement dans la norme.

Limite skiable : encore à basse altitude sur l'herbe en ubac, parfois dès 900 à 1000 m. Même si la plupart des pentes sont enneigées bas, sur terrain rocheux, il vaut mieux atteindre 1300 m en N, 1800 m en Sud pour trouver un terrain plus serein.

Qualité de la neige : dans la plupart des secteurs, la neige encore d'aspect poudreuse au matin va commencer à se densifier au fil de la journée et du vent qui se lève. Il faut chercher les secteurs protégés par situation de foehn pour skier de la neige légère toute la journée. Enfin, en Sud raide sous 2000/2200 m, la neige est faiblement croutée, potentiellement pénible à skier.

Aperçu météo pour le lundi 02 février

nuit	matin	après-midi	soir

Belle matinée avec un vent encore discret, puis le foehn s'établit franchement dans l'après-midi tandis que les nuages se multiplient.

Pluie-Neige				
Iso 0 °C	1 500 m	2 100 m	2 400 m	2 400 m
Vent 2000 m	↗ 20 km/h	↖ 20 km/h	↖ 30 km/h	← 50 km/h
Vent 3000 m	→ 35 km/h	↗ 35 km/h	↗ 40 km/h	↑ 50 km/h

Épaisseur de neige hors-piste

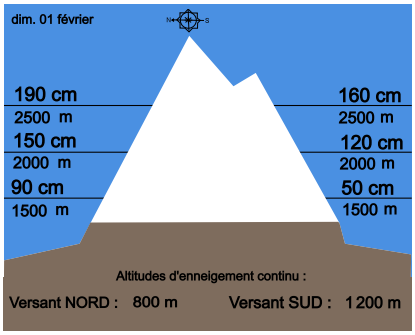

Précipitations à 1800 m

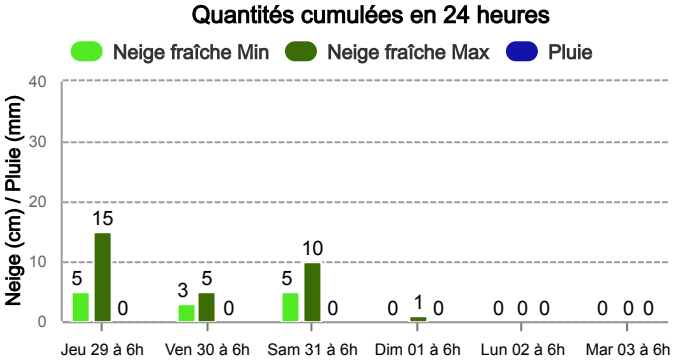

Tendance du mardi 03 février

3

Indice de risque marqué

Tempête de foehn dans la nuit de lundi à mardi : le risque reste marqué avec de nombreuses plaques réactives mardi, et toujours le risque de déclencher une grande avalanche en cas de départ en cascade...

Pour consulter la vigilance en cours, veuillez vous rendre sur le site https://vigilance.meteofrance.fr/fr

Météo-France - 73 avenue de Paris, 94165 Saint-Mandé cedex - Contact : contact@meteo.fr

Rédigé par Météo-France avec la contribution des observateurs du réseau nivo-météorologiques. Partenariat : ANMSM (Maires de Stations de Montagne), DSF (Domaines Skiables de France), ADSP (Directeurs de Pistes et de la Sécurité des Stations de Sports d'Hiver) et autres acteurs de la montagne.

Bulletin neige & avalanches par téléphone au

0 892 68 10 20 Service 0,35 € / min + prix appel

RÉPUBLIQUE FRANÇAISE
Liberté Égalité Fraternité

METEO FRANCE
À VOS CÔTÉS, DANS UN CLIMAT QUI CHANGE

Bulletin d'estimation du risque d'avalanche

(valable en dehors des pistes balisées et ouvertes)

MASSIF : Beaufortain

Rédigé le dimanche 1 février 2026 à 17h

Conditions nivo-météo des 7 derniers jours

	lun. 26/01				mar. 27/01				mer. 28/01				jeu. 29/01				ven. 30/01				sam. 31/01				dim. 01/02			
	03h	09h	15h	21h	03h	09h	15h	21h	03h	09h	15h	21h	03h	09h	15h	21h	03h	09h	15h	21h	03h	09h	15h	21h	03h	09h	15h	21h
Météo																												
Vent (km/h)	20	20	20	15	20	30	45	55	50	30	25	30	30	20	15	20	40	35	25	25	25	20	15	15	10	10	15	20
à 3000m																												
Vent (km/h)	10	10	10	5	10	15	30	40	35	15	10	10	15	10	10	10	10	15	15	10	15	10	10	10	5	5	10	10
à 2000m																												

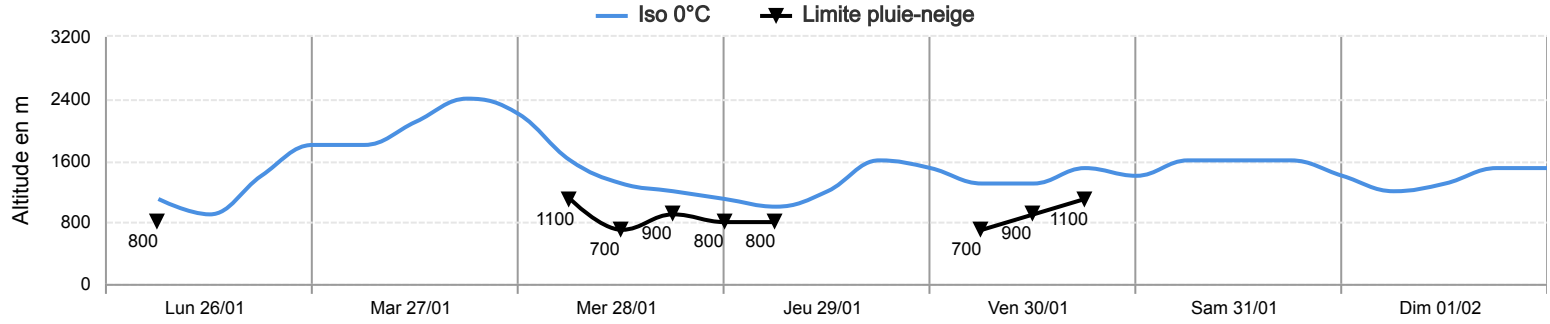

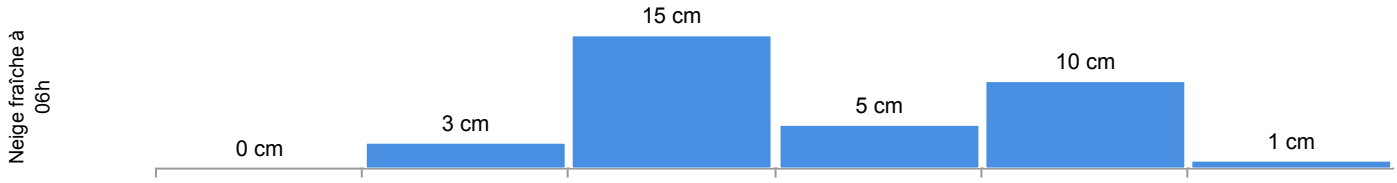

Risque d'avalanche	lun. 26/01	mar. 27/01	mer. 28/01	jeu. 29/01	ven. 30/01	sam. 31/01	dim. 01/02
	2	3	3	3	3	3	3

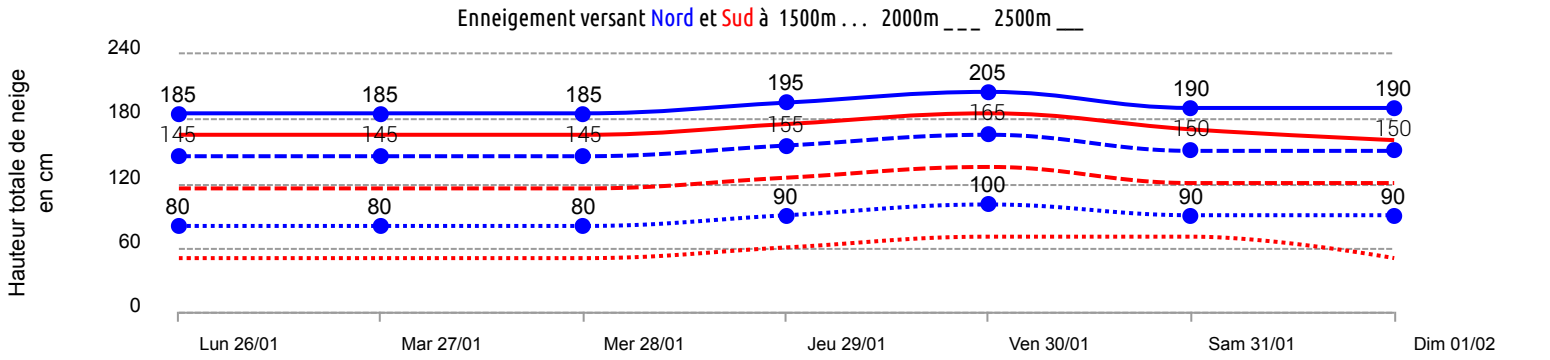

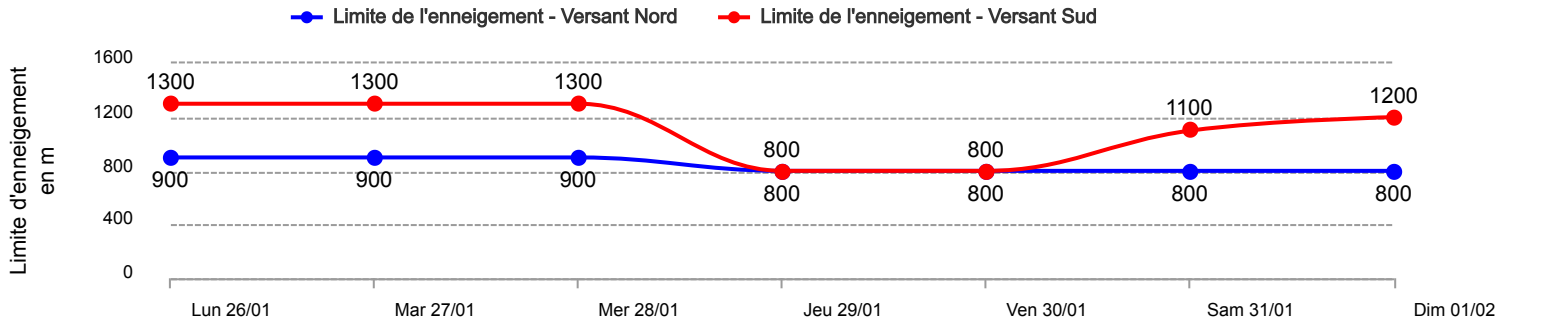

Pour consulter la vigilance en cours, veuillez vous rendre sur le site https://vigilance.meteofrance.fr/fr

Météo-France - 73 avenue de Paris, 94165 Saint-Mandé cedex - Contact : contact@meteo.fr

Rédigé par Météo-France avec la contribution des observateurs du réseau nivo-météorologiques. Partenariat : ANMSM (Maires de Stations de Montagne), DSF (Domaines Skiables de France), ADSP (Directeurs de Pistes et de la Sécurité des Stations de Sports d'Hiver) et autres acteurs de la montagne.

Bulletin neige & avalanches par téléphone au
0 892 68 10 20 Service 0,35 € / min + prix appel