Bulletin d'estimation du risque d'avalanche

(valable en dehors des pistes balisées et ouvertes)

MASSIF : Haute-Tarentaise

Rédigé le dimanche 1 février 2026 à 17h

Estimation des risques pour le : LUNDI 02 FÉVRIER

FORMATION DE NOUVELLES PLAQUES SUPERFICIELLES SOUS LE FOEHN QUI S'ÉTABLIT EN JOURNÉE.
TOUJOURS UN RISQUE DE GROS DÉPART EN CAS DE MOBILISATION DE LA COUCHE FRAGILE ENFOUIE.

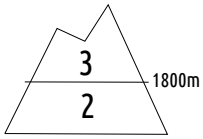

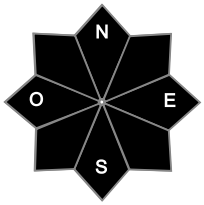

Au-dessus de 1800m indice de risque marqué, plus bas indice limité.

Départs spontanés : rares départs linéaires plutôt en deuxième partie de journée.

Déclenchements provoqués : quelques plaques réactives en formation sous le foehn. Couche fragile persistante généralisée.

Indices de risque : 5 très fort - 4 fort - 3 marqué - 2 limité - 1 faible -- En noir : les pentes les plus dangereuses

Stabilité du manteau neigeux

Situation avalancheuse typique : neige ventée couche fragile persistante

Déclenchements provoqués :
(1) **Quelques plaques friables en formation sous le foehn** qui forcit au fil de la journée. Ces plaques sont **de plus en plus réactives et épaisses**, et se retrouvent aussi bien près des crêtes qu'en pied de pentes. Tailles 2 (moyennes) avec **cassures de 20/40 cm** d'ici la fin de journée. Seules les pentes Sud raides sous 2000/2200 m d'altitude seront moins réactives car la neige y est transformée. *Observables : indices de transport, neige un peu plus ferme sous les skis.*
(2) La **couche fragile persistante (grains anguleux), enfouie** depuis plusieurs semaine, reste **généralisée dès 1800 m.** Présente essentiellement dans les pentes **Nord**, **Est** et **Ouest** mais **aussi en Sud à haute altitude**, elle vient former une épaisse structure de plaque qui, en cas de déclenchement, entraîne l'ensemble du manteau neigeux. Déclenchement aléatoire, souvent difficile, encore parfois possible à distance, provoquant des avalanches de taille 3 (grandes), avec des cassures d'1 à 2 m. *Observables : woumfs, tests CT/ECT.*
Une première avalanche dans la neige ventée (1) pourrait mobiliser en cascade la couche fragile enfouie (2).

Départs spontanés : au fil de la journée et du vent qui forcit, quelques petits départs linéaires peuvent se produire spontanément. Une rare taille 2 est possible, mais il n'est alors pas exclu que cette première avalanche *moyenne* vienne mobiliser en cascade les vieilles couches fragiles enfouies, engendrant alors une taille 3.

Qualité de la neige

Enneigement : tout à fait correct pour la saison.

Limite skiable : à basse altitude sur l'herbe. Sur terrain rocheux, gare à l'absence de sous-couche en-dessous de 1500 m en N, 2000 m en Sud.

Qualité de la neige : dans la plupart des secteurs, la neige encore d'aspect poudreuse au matin va commencer à se densifier au fil de la journée et du vent qui se lève. Il faut chercher les secteurs protégés par situation de foehn pour skier de la neige légère toute la journée. Enfin, en Sud raide sous 2000/2200 m, la neige est faiblement croutée, potentiellement pénible à skier.

Aperçu météo pour le lundi 02 février

nuit	matin	après-midi	soir

Belle matinée avec un vent encore discret, puis le foehn s'établit franchement dans l'après-midi tandis que les nuages se multiplient.

Pluie-Neige				
Iso 0 °C	1 600 m	2 100 m	2 300 m	2 300 m
Vent 2500 m	→ 10 km/h	↗ 20 km/h	← 30 km/h	↙ 50 km/h
Vent 3500 m	→ 40 km/h	↗ 40 km/h	↗ 40 km/h	↗ 60 km/h

Épaisseur de neige hors-piste

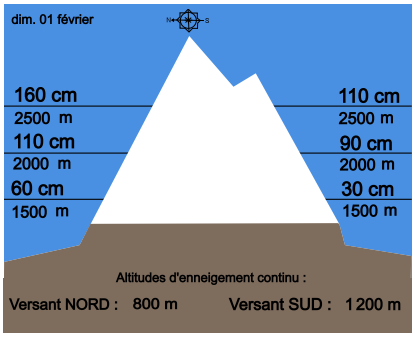

Précipitations à 1800 m

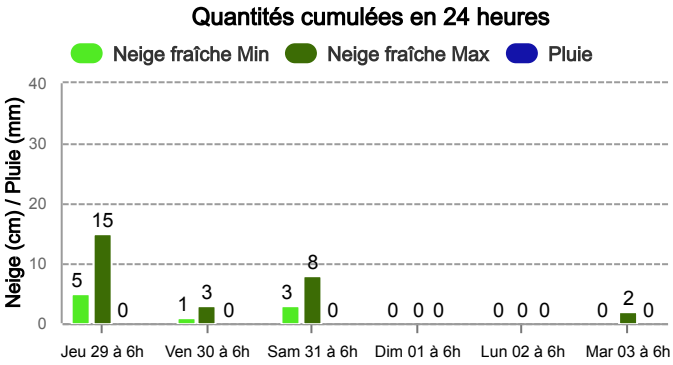

Tendance du mardi 03 février

Indice de risque fort

Tempête de foehn dans la nuit de lundi à mardi : risque en hausse avec de nombreuses plaques réactives, et toujours le risque de déclencher "un monstre" en cas de départ en cascade...

Pour consulter la vigilance en cours, veuillez vous rendre sur le site https://vigilance.meteofrance.fr/fr

Météo-France - 73 avenue de Paris, 94165 Saint-Mandé cedex - Contact : contact@meteo.fr

Rédigé par Météo-France avec la contribution des observateurs du réseau nivo-météorologiques. Partenariat : ANMSM (Maires de Stations de Montagne), DSF (Domaines Skiables de France), ADSP (Directeurs de Pistes et de la Sécurité des Stations de Sports d'Hiver) et autres acteurs de la montagne.

Bulletin neige & avalanches par téléphone au **0 892 68 10 20** Service 0,35 € / min + prix appel

Bulletin d'estimation du risque d'avalanche

(valable en dehors des pistes balisées et ouvertes)

MASSIF : Haute-Tarentaise

Rédigé le dimanche 1 février 2026 à 17h

Conditions nivo-météo des 7 derniers jours

	lun. 26/01				mar. 27/01				mer. 28/01				jeu. 29/01				ven. 30/01				sam. 31/01				dim. 01/02			
	03h	09h	15h	21h	03h	09h	15h	21h	03h	09h	15h	21h	03h	09h	15h	21h	03h	09h	15h	21h	03h	09h	15h	21h	03h	09h	15h	21h
Météo																												
Vent (km/h)	20	25	20	20	25	35	50	60	45	30	30	35	45	25	20	30	40	40	35	30	30	20	20	20	20	20	30	30
à 3500m																												
Vent (km/h)	10	15	15	5	10	20	35	45	35	20	15	20	20	15	15	10	10	15	20	10	10	10	10	10	10	10	10	10
à 2500m																												

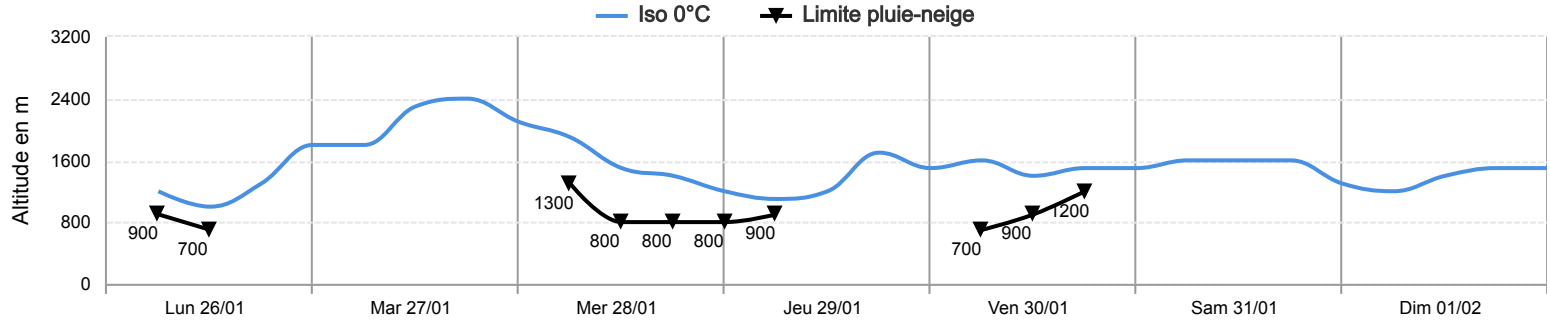

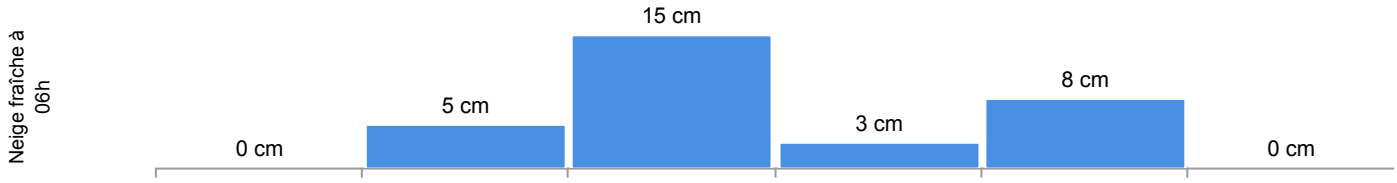

Risque d'avalanche	lun. 26/01	mar. 27/01	mer. 28/01	jeu. 29/01	ven. 30/01	sam. 31/01	dim. 01/02
	3	3	3	3	3	3	3

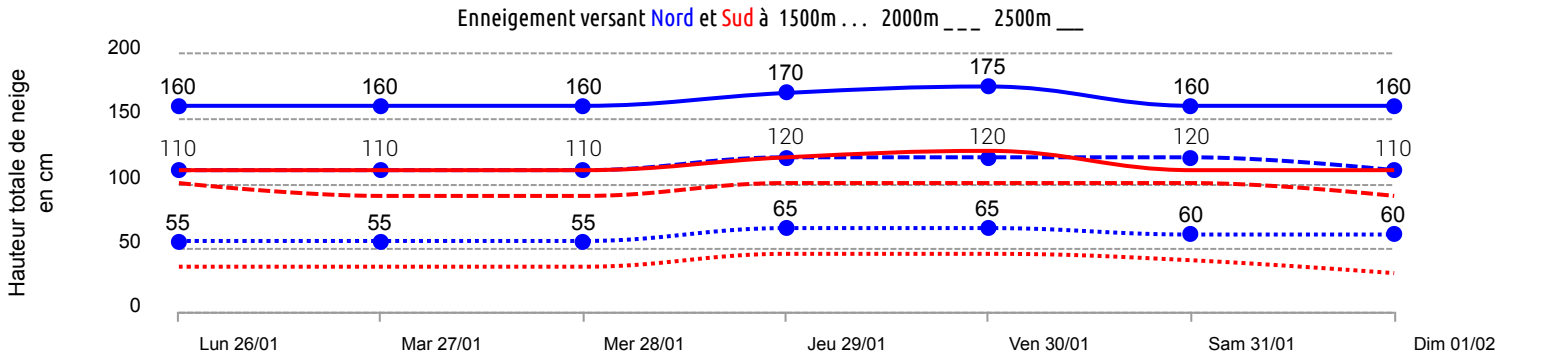

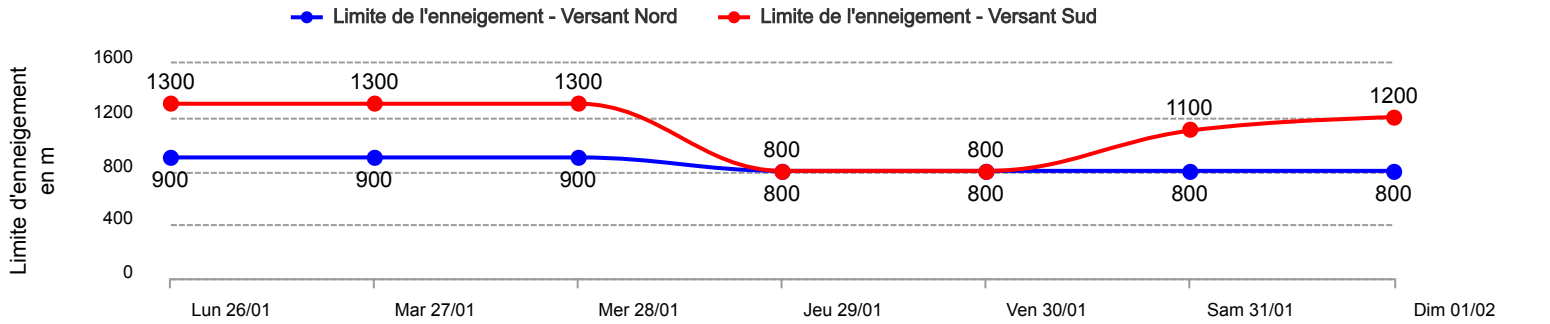

Pour consulter la vigilance en cours, veuillez vous rendre sur le site https://vigilance.meteofrance.fr/fr

Météo-France - 73 avenue de Paris, 94165 Saint-Mandé cedex - Contact : contact@meteo.fr

Bulletin neige & avalanches par téléphone au

0 892 68 10 20 Service 0,35 € / min + prix appel

Rédigé par Météo-France avec la contribution des observateurs du réseau nivo-météorologiques. Partenariat : ANMSM (Maires de Stations de Montagne), DSF (Domaines Skiables de France), ADSP (Directeurs de Pistes et de la Sécurité des Stations de Sports d'Hiver) et autres acteurs de la montagne.