GOBIERNO DE ESPAÑA
VICEPRESIDENCIA TERCERA DEL GOBIERNO
MINISTERIO PARA LA TRANSICIÓN ECOLÓGICA Y EL RETO DEMOGRÁFICO

Boletín de información nivológica y de peligro de aludes

Pirineo Catalán

aemet Agencia Estatal de Meteorología

lunes, 2 de febrero de 2026

Pronóstico hasta las 24 horas del martes, día 3 de febrero

(Válido fuera de pistas de esquí balizadas y abiertas)

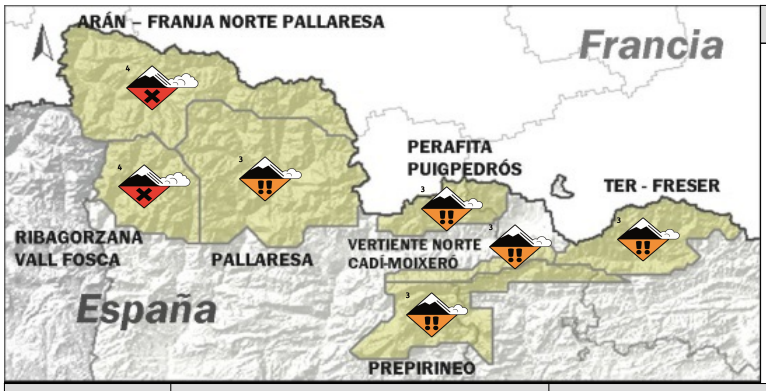

Problemas de aludes

Placas de viento

Nieve reciente

Macizo	Peligro	Problemas de aludes, cota, orientación, tamaño	Innivación observada (m)
Arán - Franja norte Pallaresa	4 / 4 / 3 / 2100 Fuerte	Placas de viento: 2100, N O E S, 3 Nieve reciente: 1700, N O E S, 2	2026-02-02 N S Cotas bajas
Ribagorzana - Vall Fosca	4 / 4 / 3 / 2100 Fuerte	Placas de viento: 2100, N O E S, 3 Nieve reciente: 1700, N O E S, 2	2026-02-02 N S Cotas bajas
Pallaresa	3 / 3 Notable	Placas de viento: 2100, N O E S, 2 Nieve reciente: 1700, N O E S, 2	2026-02-02 N S Cotas bajas

AEMET. Se autoriza la reproducción de su contenido citando la fuente.

Boletín de información nivológica y de peligro de aludes

Pirineo Catalán

Perafita - Puigpedrós	3 **Notable**	**Placas de viento** 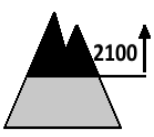 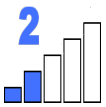 **Nieve reciente** 	2026-02-02 Cotas bajas
Ter - Freser	3 **Notable**	**Placas de viento** 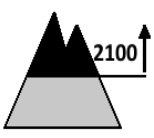 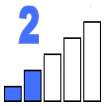 **Nieve reciente** 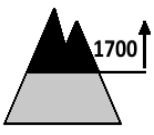 	2026-02-02 Cotas bajas
Vertiente norte Cadí - Moixeró	3 **Notable**	**Placas de viento** 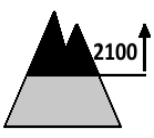 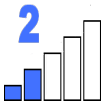 **Nieve reciente** 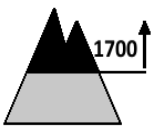 	2026-02-02 Cotas bajas
Prepirineo	3 **Notable**	**Placas de viento** 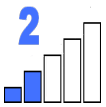 **Nieve reciente** 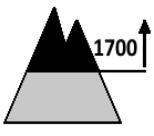 	2026-02-02 Cotas bajas

Estado del manto y observaciones recientes

A las 8 UTC del día de hoy se habían registrado algunas precipitaciones, generalmente poco significativas, del entorno de 1-5 l/m2, generalmente en forma de lluvia por debajo de los 2000 metros. Durante el día de hoy se espera que las precipitaciones continúen de manera más significativa, con una cota de nieve que irá descendiendo, hasta alcanzar los 1300-1100 metros a últimas horas.

AEMET. Se autoriza la reproducción de su contenido citando la fuente.

La cubierta de nieve comienza en cotas bajas y los espesores de gran parte de la red de observación están en máximos para la época. Estos se sitúan en torno a 120-150 cm por encima de 2100 metros, valores que pueden ser muy superiores conforme ganamos altitud, así como en ventisqueros u otras áreas de acumulación.

En cotas altas, la nieve presenta muy grandes acumulaciones, manteniéndose seca y muy venteada en superficie, al tiempo que, en umbrías, se observan estratos débiles internos así como una antigua capa débil persistente en la base del manto. En cotas inferiores, la nieve está más humedecida y estable, presentando generalmente una estructura superficial de nieve reciente sobre costra de rehielo.

Evolución del manto y peligro de aludes para el martes, día 3

Problemas de placas de viento y capas débiles persistentes en cotas altas. Problema de nieve reciente. Problema de nieve húmeda y deslizamientos basales en cotas medias y bajas.

A lo largo del día de hoy se esperan precipitaciones significativas, con una cota de nieve que irá descendiendo progresivamente hasta alcanzar cotas bajas. De esta manera, por encima de los 1900 metros se podrán alcanzar nuevos acumulados de unos 10-20 cm, localmente superiores, y que disminuirán conforme descendamos en altitud. Así mismo se espera que las precipitaciones continúen a lo largo de la jornada de mañana, aunque de manera más débil y ocasional. En este contexto, son probables las purgas espontáneas de nieve reciente, de tamaño 1 (pequeño, capaz de desestabilizar a una persona) ó 2 (mediano, capaz de enterrar a una persona), preferentemente en cotas medias y altas, donde las acumulaciones serán más significativas.

El mayor peligro tendrá lugar en cotas altas, donde los fuertes vientos, generalmente del oeste y sudoeste, ventearán la nieve y favorecerán a la formación de placas de viento en todas las orientaciones, aunque con preferencia en las vertientes norte y este. Estas estructuras se añadirán a otras ya existentes de formación antigua, todavía activas. También podrán aparecer en cotas medias, aunque con tamaños más bien pequeños. Todas estas placas se mantendrán inestables, y bastará el paso de un solo esquiador para colapsarlas. En las umbrías, no se descarta que las capas débiles persistentes antiguas sigan activas, siendo susceptibles de colapsar en zonas de manto delgado. Ambos tipos de problemas podrán dar lugar a aludes de tamaño 2 ó 3 (grande, capaz de destruir un vehículo), incluso en zonas ya transitadas.

En cotas medias y bajas, el problema de nieve húmeda que ha estado presente durante el día de hoy, tenderá a estabilizarse con el descenso de las temperaturas y las cotas de nieve, depositándose nuevos centímetros de nieve reciente sobre él. Así, durante las últimas horas del día de hoy y las primeras de mañana, todavía podrán producirse este tipo de aludes, que fácilmente podrán alcanzar el tamaño 2 (mediano), sin descartar alguno 3 (grande). Cabe destacar que, en aquellas zonas de manto delgado donde las lluvias hayan sido muy copiosas, el agua podría haber percolado hasta los niveles inferiores pudiendo producir deslizamientos basales. Esto podrá suceder con preferencia en zonas de manto delgado y en cotas bajas, donde las lluvias han durado más. Es por esto que se espera que este tipo de aludes sean generalmente de tamaño 1 (pequeño) ó 2 (mediano), y raramente puedan alcanzar el tamaño 3 (grande).

AEMET. Se autoriza la reproducción de su contenido citando la fuente.

Predicción meteorológica para el martes, día 3

Predominio de nuboso o intervalos nubosos, con abundante nubosidad baja, tendiendo a muy nuboso o cubierto a últimas horas. Precipitaciones débiles y ocasionales, más probables en el extremo occidental, donde no se descarta que puedan ser localmente moderadas. Cota de nieve en torno a 1000-1100 metros. Temperaturas en ligero o moderado descenso. Heladas débiles, moderadas en cotas altas. Viento moderado o fuerte del oeste y suroeste, acompañado de rachas muy fuertes en cotas altas y zonas expuestas.

Datos en la atmósfera libre:

Altitud de la isoterma de 0 ºC: 1500 m
Altitud de la isoterma de -10 ºC: 3000 m

Viento a 1500 m: SW 20 km/h
Viento a 3000 m: SW 50 km/h

Evolución para el miércoles día 4

Nivel de peligro con pocos cambios.

Escala europea de peligro de aludes

Débil | Limitado | Notable | Fuerte | Muy Fuerte

Problemas de aludes

Nieve reciente | Placas de viento | Capas débiles persistentes | Nieve húmeda | Deslizamientos basales | Sin problema evidente

Nota1: Se recuerda que, siempre que haya nieve, la ausencia total de peligro no existe. Hay que tener presente que en circunstancias desfavorables, con aludes de tamaño 1 (alud pequeño o colada) y tamaño 2 (alud mediano), se pueden sufrir severos daños personales.

Nota2: Los BPA se elaboran en base a información meteorológica así como al estado del manto nivoso a través de sondeos puntuales. Se advierte a los usuarios de la variabilidad de esta información al extrapolarla a zonas extensas de montaña. Por ello, AEMET no se hace responsable de su uso para la toma de decisiones que conciernen a la seguridad personal, ni de los riesgos físicos o materiales de ellas derivadas.

AEMET. Se autoriza la reproducción de su contenido citando la fuente.