GOBIERNO DE ESPAÑA
VICEPRESIDENCIA TERCERA DEL GOBIERNO
MINISTERIO PARA LA TRANSICIÓN ECOLÓGICA Y EL RETO DEMOGRÁFICO

Boletín de información nivológica y de peligro de aludes

Pirineo Navarro y Aragonés

aemet Agencia Estatal de Meteorología

lunes, 2 de febrero de 2026

Pronóstico hasta las 24 horas del martes, día 3 de febrero

(Válido fuera de pistas de esquí balizadas y abiertas)

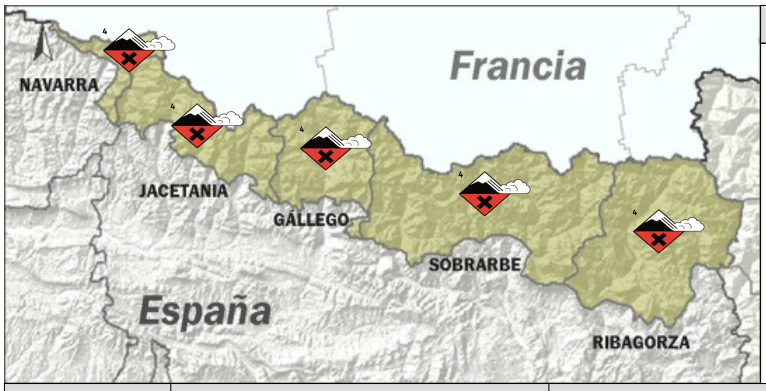

Problemas de aludes

Placas de viento

Nieve reciente

Macizo	Peligro	Problemas de aludes, cota, orientación, tamaño	Innivación observada (m)
Navarra	4 / 4 / 3 / 2100 Fuerte	Placas de viento: 2100; N O E S; 3 Nieve reciente: N O E S; 2	2026-02-02 N S Cotas bajas
Jacetania	4 / 4 / 3 / 2100 Fuerte	Placas de viento: 2100; N O E S; 3 Nieve reciente: N O E S; 2	2026-02-02 N S Cotas bajas
Gállego	4 / 4 / 3 / 2100 Fuerte	Placas de viento: 2100; N O E S; 3 Nieve reciente: N O E S; 2	2026-02-02 N S Cotas bajas

AEMET. Se autoriza la reproducción de su contenido citando la fuente.

Sobrarbe	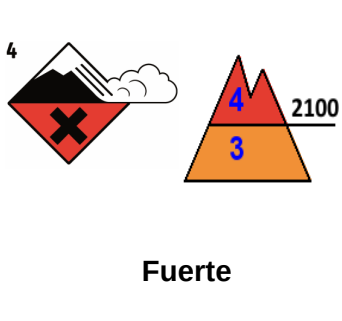 **Fuerte**	**Placas de viento** 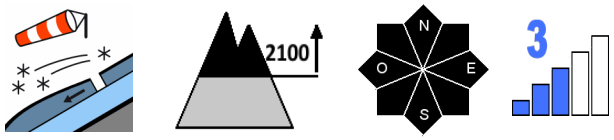 **Nieve reciente** 	2026-02-02 Cotas bajas
Ribagorza	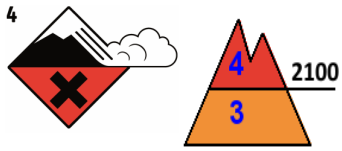 **Fuerte**	**Placas de viento** 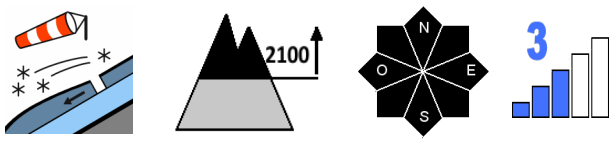 **Nieve reciente** 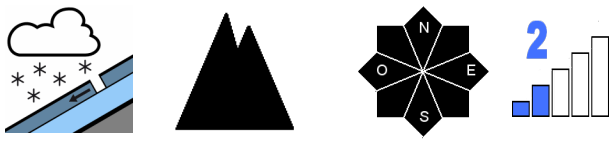	2026-02-02 Cotas bajas

Estado del manto y observaciones recientes

A las 8 UTC del día de hoy se han reportado algunas precipitaciones, generalmente en torno a 5-10 l/m2, aunque en los macizos occidentales han sido localmente más significativas, alcanzando los 15-25 l/m2 en algunos enclaves. Estas han sido en forma de nieve por encima de los 2000 metros, dejando nuevos centímetros de nieve reciente en cotas altas. Por debajo, se han registrado pérdidas de espesor significativas debido al efecto de la lluvia sobre el manto nivoso. Durante el día de hoy se espera que las precipitaciones continúen de manera significativa, con una cota de nieve que irá descendiendo, hasta alcanzar los 1300-1100 metros a últimas horas.

El manto comienza en cotas bajas, con espesores muy variables a causa del efecto del viento, pero que superan los 100-120 cm en torno a 1800 metros y los 150-200 cm por encima de 2100, notablemente más en ventisqueros y otras zonas de acumulación. Los espesores superan el percentil 80 de la serie histórica en la mayor parte de la red de observación.

En cotas altas, la nieve presenta muy grandes acumulaciones, manteniéndose seca y muy venteada en superficie mientras que, internamente y principalmente en umbrías, se observan niveles débiles de facetas, además de las antiguas capas débiles persistentes que siguen mostrando reactividad, como así confirman algunos de los últimos sondeos y aludes. En cotas inferiores la nieve se encuentra muy humedecida debido a las recientes lluvias, que han resultado muy copiosas, así como al ascenso de las temperaturas y la insolación.

En las últimas 24 horas se han reportado varios aludes pequeños de nieve húmeda por debajo de los 2300 metros, así como algunas coladas de nieve reciente por encima de los 2500 metros. También cabe recordar que se han reportado numerosos aludes en los últimos días, a destacar tres de tamaño grande, dos de ellos naturales en el área de Panticosa, y un tercero accidental en el Pico Cibollés (Cerler), todos con estructura de placa sobre capa débil persistente y con salidas por encima de los 2300 metros.

AEMET. Se autoriza la reproducción de su contenido citando la fuente.

Evolución del manto y peligro de aludes para el martes, día 3

Problemas de placas de viento y capas débiles persistentes en cotas altas. Problema de nieve reciente. Problema de nieve húmeda y deslizamientos basales en cotas medias y bajas.

A lo largo del día de hoy se esperan precipitaciones significativas, con una cota de nieve que irá descendiendo progresivamente hasta alcanzar cotas bajas. De esta manera, por encima de los 1800 metros se podrán alcanzar nuevos acumulados de unos 20-30 cm, localmente superiores, y que disminuirán conforme descendamos en altitud, pudiendo alcanzar los 5 cm en cotas bajas. Así mismo se espera que las precipitaciones continúen a lo largo de la jornada de mañana, aunque estas serán generalmente débiles, pudiendo añadir algunos nuevos centímetros. En este contexto, son probables las purgas espontáneas de nieve reciente, de tamaño 1 (pequeño, capaz de desestabilizar a una persona) ó 2 (mediano, capaz de enterrar a una persona), preferentemente en cotas medias y altas, donde las acumulaciones serán más significativas.

El mayor peligro tendrá lugar en cotas altas, donde los fuertes vientos, generalmente del sur y sudoeste, ventearán la nieve y favorecerán la formación de placas de viento en todas las orientaciones, aunque con preferencia en las vertientes norte y este. Estas estructuras se añadirán a otras ya existentes de formación antigua, todavía activas. También podrán aparecer en cotas medias, aunque con tamaños más bien pequeños. Todas estas placas se mantendrán inestables, y bastará el paso de un solo esquiador para colapsarlas. En las umbrías, las capas débiles persistentes antiguas siguen dando muestras de reactividad, siendo susceptibles de colapsar en zonas de manto delgado. Ambos tipos de problemas podrán dar lugar a aludes de tamaño 2 ó 3 (grande, capaz de destruir un vehículo), incluso en zonas ya transitadas, y no se descarta que localmente alcancen el tamaño 4 (muy grande, capaz de destruir un camión o vagón de tren). Por último, cabe mencionar la proliferación de cornisas y la posibilidad de desencadenamiento de aludes bajo estas en caso de ruptura.

En cotas medias y bajas, el problema de nieve húmeda que ha estado presente durante el día de hoy, tenderá a estabilizarse con el descenso de las temperaturas y las cotas de nieve, depositándose nuevos centímetros de nieve reciente sobre él. Así, durante las últimas horas del día de hoy y las primeras de mañana, todavía podrán producirse este tipo de aludes, que fácilmente podrán alcanzar el tamaño 2 (mediano), sin descartar alguno 3 (grande). Cabe destacar que, en aquellas zonas de manto delgado donde las lluvias hayan sido muy copiosas, el agua podría haber percolado hasta los niveles inferiores pudiendo producir deslizamientos basales. Esto podrá suceder con preferencia en zonas de manto delgado y en cotas bajas, donde las lluvias han durado más. Es por esto que se espera que este tipo de aludes sean generalmente de tamaño 1 (pequeño) ó 2 (mediano), y raramente puedan alcanzar el tamaño 3 (grande).

Predicción meteorológica para el martes, día 3

Pirineo navarro:
Nuboso con nubes bajas, tendiendo a aumentar la nubosidad en la segunda mitad del día. Precipitaciones débiles y ocasionales, preferentemente en la segunda mitad del día. Cota de nieve en torno a 900-1100 metros. Temperaturas en ligero descenso, o moderado de las máximas. Heladas débiles, moderadas en cotas altas. Viento moderado o fuerte del sur y sudoeste, con rachas muy fuertes en cotas altas y zonas expuestas.

AEMET. Se autoriza la reproducción de su contenido citando la fuente.

Pirineo aragonés:
Nuboso o muy nuboso con abundantes nubes bajas. Precipitaciones débiles o localmente moderadas, preferentemente en el área occidental. Cota de nieve en torno a 900-1100 metros. Temperaturas en ligero o moderado descenso. Heladas débiles o moderadas, localmente fuertes y persistentes en la alta montaña. Viento flojo o moderado de componentes sur y oeste, con intervalos de fuerte. Más intenso en cotas altas y zonas expuestas, donde soplará generalmente fuerte con probables rachas muy fuertes.

Datos en la atmósfera libre:

Altitud de la isoterma de 0 ºC: 1300 m
Altitud de la isoterma de -10 ºC: 2800 m

Viento a 1500 m: S 20 km/h
Viento a 3000 m: SW 50 km/h

Evolución para el miércoles día 4

Nivel de peligro con pocos cambios.

(Información elaborada a partir de los datos recibidos de los refugios de Linza, Lizara, Panticosa, Bachimaña, Góriz, Pineta, Estós, Angel Orús, La Renclusa, Cap de Llauset y Belagua, de las estaciones de esquí de Formigal y Panticosa (lagos), de la estación de esquí de fondo de Llanos del Hospital y de Ordesa Pradera)

Escala europea de peligro de aludes

Débil Limitado Notable Fuerte Muy Fuerte

Problemas de aludes

Nieve reciente Placas de viento Capas débiles persistentes Nieve húmeda Deslizamientos basales Sin problema evidente

Nota1: Se recuerda que, siempre que haya nieve, la ausencia total de peligro no existe. Hay que tener presente que en circunstancias desfavorables, con aludes de tamaño 1 (alud pequeño o colada) y tamaño 2 (alud mediano), se pueden sufrir severos daños personales.

Nota2: Los BPA se elaboran en base a información meteorológica así como al estado del manto nivoso a través de sondeos puntuales. Se advierte a los usuarios de la variabilidad de esta información al extrapolarla a zonas extensas de montaña. Por ello, AEMET no se hace responsable de su uso para la toma de decisiones que conciernen a la seguridad personal, ni de los riesgos físicos o materiales de ellas derivadas.

AEMET. Se autoriza la reproducción de su contenido citando la fuente.