Montag 02.02.2026

Aktualisiert am 02.02.2026 um 08:00

Vormittag

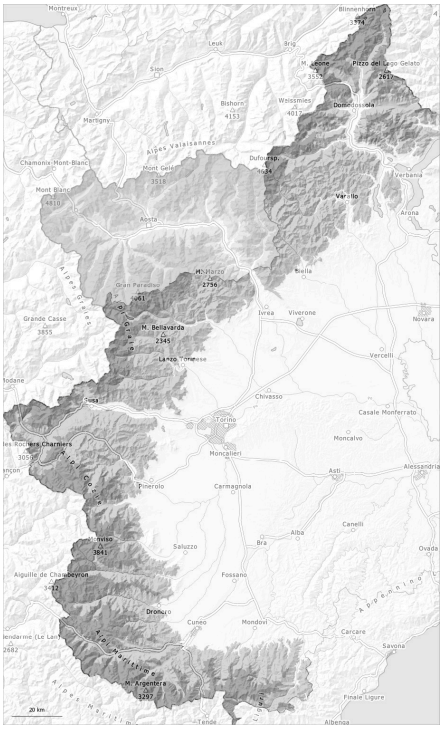

Nachmittag

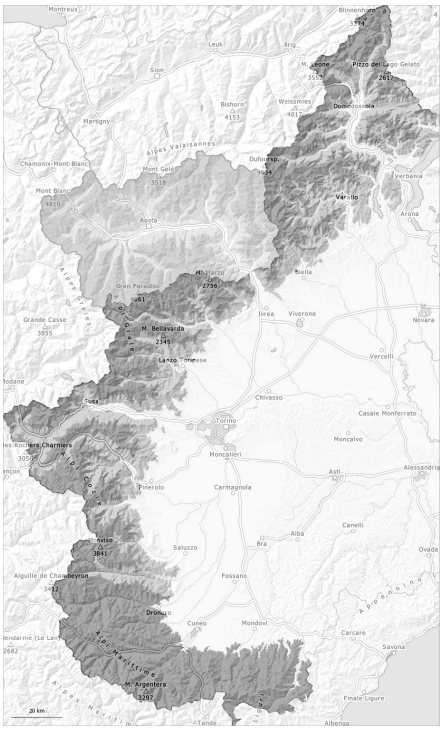

1	2	3	4	5
gering	mäßig	erheblich	groß	sehr groß

Gefahrenstufe 3 - Erheblich

AM:

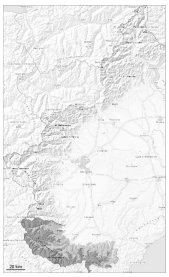

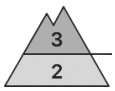

Waldgrenze

Tendenz: Lawinengefahr steigt
am Dienstag, den 03.02.2026

Triebschnee

Waldgrenze

Neuschnee

PM:

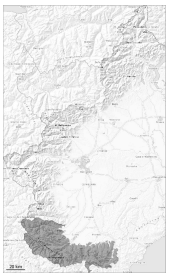

Tendenz: Lawinengefahr steigt
am Dienstag, den 03.02.2026

Triebschnee

Mit dem teils starken Wind nehmen die Gefahrenstellen zu.

Mit mäßigem bis starkem Südwestwind entstehen im Tagesverlauf weitere Triebschneeansammlungen. Sie können von einzelnen Wintersportlern ausgelöst werden und groß werden. Dies vor allem an steilen Hängen oberhalb der Waldgrenze sowie in Rinnen, Mulden und hinter Geländekanten.
Ab dem Nachmittag fällt Schnee bis in tiefe Lagen. Die Gefahrenstellen sind bei der schlechten Sicht kaum zu erkennen. Skitouren, Variantenabfahrten und Schneeschuhwanderungen erfordern Vorsicht und Zurückhaltung.

Schneedecke

Gefahrenmuster gm.6: lockerer schnee und wind

Ab dem Nachmittag fällt Schnee bis in tiefe Lagen. Mit mäßigem bis starkem Südwestwind entstehen frische Triebschneeansammlungen.
Die Schneedecke ist weich, mit einer Oberfläche aus lockerem Schnee. Dies in schattigen, windgeschützten Lagen in tiefen und mittleren Lagen.

Tendenz

Anstieg der Lawinengefahr mit Neuschnee und Wind.

Gefahrenstufe 3 - Erheblich

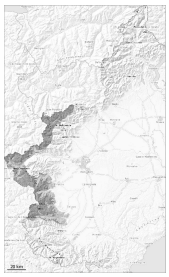

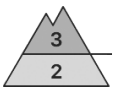

Waldgrenze

Tendenz: Lawinengefahr bleibt gleich
am Dienstag, den 03.02.2026

Triebschnee

Waldgrenze

Altschnee

In der Höhe erhebliche Lawinengefahr. Mit dem teils mäßigen Wind nehmen die Gefahrenstellen zu.

Am Nachmittag fällt etwas Schnee. Die Gefahrenstellen sind bei der schlechten Sicht kaum zu erkennen. Triebschneeansammlungen können stellenweise von einzelnen Wintersportlern ausgelöst werden und groß werden. Dies vor allem an steilen Hängen auch oberhalb der Waldgrenze sowie in Rinnen, Mulden und hinter Geländekanten in mittleren und hohen Lagen.
Lawinen können v.a. an steilen Schattenhängen in tieferen Schichten ausgelöst werden. Wummgeräusche und Risse beim Betreten der Schneedecke sowie spontane Lawinenabgänge sind deutliche Zeichen eines schwachen Schneedeckenaufbaus.
Eine vorsichtige Routenwahl und Entlastungsabstände werden empfohlen.

Schneedecke

Gefahrenmuster gm.6: lockerer schnee und wind | gm.1: bodennahe schwachschicht

Mit Wind entstehen weitere Triebschneeansammlungen. Neu- und Triebschnee werden vor allem an windgeschützten Schattenhängen auf weiche Schichten abgelagert.

Mittlere und hohe Lagen: Im unteren Teil der Schneedecke sind vor allem an sehr steilen Schattenhängen vereinzelt störanfällige Schwachschichten vorhanden.

Gefahrenstufe 3 - Erheblich

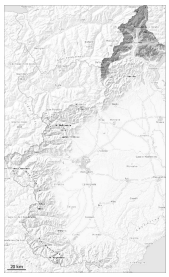

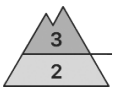

Waldgrenze

Tendenz: Lawinengefahr bleibt gleich
am Dienstag, den 03.02.2026

Triebschnee

Waldgrenze

Altschnee

In der Höhe erhebliche Lawinengefahr. Mit dem mäßigen bis starken Wind nehmen die Gefahrenstellen im Tagesverlauf zu.

V.a. an steilen Hängen und in Kamm- und Passlagen sind mit dem mäßigen Wind mittlere und vereinzelt große Schneebrettlawinen möglich.
Die störanfälligen Triebschneeansammlungen können teilweise von einzelnen Wintersportlern ausgelöst werden.
Die Lawinen können v.a. an sehr steilen Schattenhängen in tiefen Schichten anreißen und groß werden.
Ab dem Nachmittag fällt etwas Schnee.

Schneedecke

Gefahrenmuster gm.6: lockerer schnee und wind | gm.1: bodennahe schwachschicht

Der mäßige Wind verfrachtet den Schnee. Die frischen Triebschneeansammlungen werden auf eine ungünstige Altschneeoberfläche abgelagert.

In der Schneedecke sind an steilen Schattenhängen kantig aufgebaute Schwachschichten vorhanden.

Gefahrenstufe 3 - Erheblich

AM:

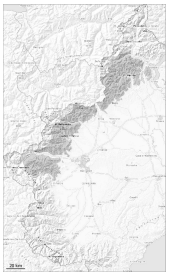

Tendenz: Lawinengefahr bleibt gleich
am Dienstag, den 03.02.2026

Triebschnee

PM:

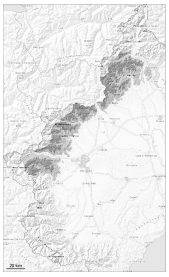

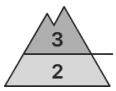

Waldgrenze

Tendenz: Lawinengefahr bleibt gleich
am Dienstag, den 03.02.2026

Triebschnee

Waldgrenze

Triebschnee

Waldgrenze

Mit dem teils starken Wind nehmen die Gefahrenstellen im Tagesverlauf zu.

Mit teils mäßigem Wind entstehen im Tagesverlauf weitere Triebschneeansammlungen. Sie können vereinzelt schon mit geringer Belastung ausgelöst werden und gefährlich groß werden. Dies vor allem an steilen Hängen oberhalb der Waldgrenze sowie in Rinnen, Mulden und hinter Geländekanten.
Am Nachmittag fällt etwas Schnee. Die Gefahrenstellen sind bei der schlechten Sicht kaum zu erkennen. Skitouren, Variantenabfahrten und Schneeschuhwanderungen erfordern eine defensive Routenwahl.

Schneedecke

Gefahrenmuster gm.6: lockerer schnee und wind | gm.1: bodennahe schwachschicht

Der mäßige Wind verfrachtet den Schnee. Die frischen Triebschneeansammlungen werden auf ungünstige Schichten abgelagert.

Die Schneedecke ist weich, mit einer Oberfläche aus lockerem Schnee. Dies in schattigen, windgeschützten Lagen auch in tiefen und mittleren Lagen.
In der Schneedecke sind an steilen Schattenhängen kantig aufgebaute Schwachschichten vorhanden.