Lundi 02.02.2026

Update du 02 02 2026, 08:00

Matin

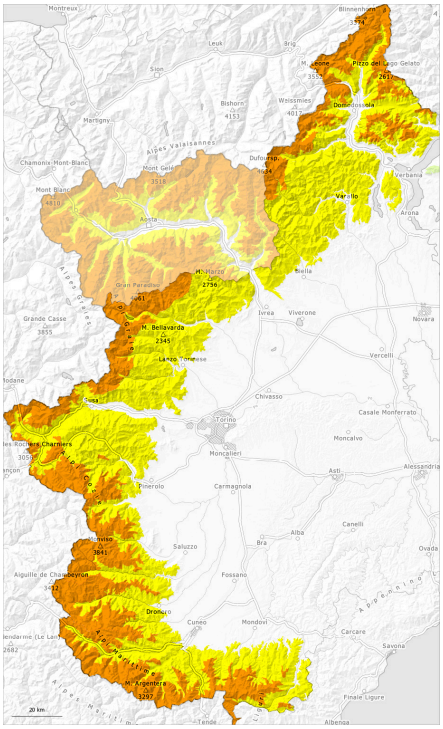

Après-midi

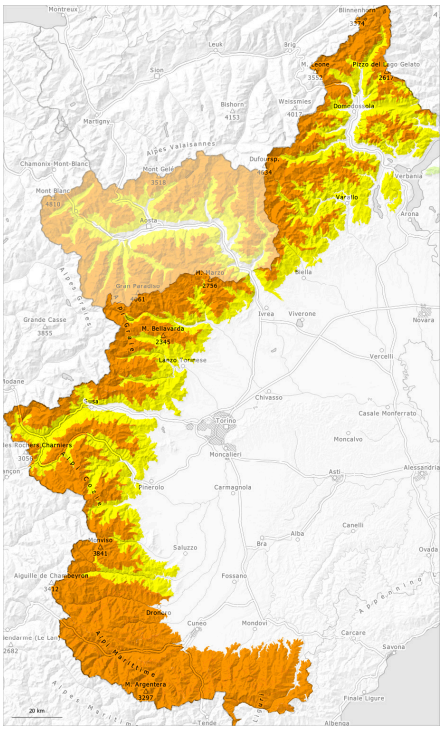

1	2	3	4	5
faible	limité	marqué	fort	très fort

Degré de danger 3 - Marqué

AM:

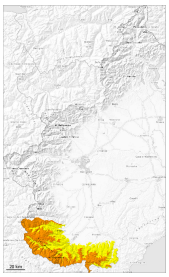

Limite de la forêt

Tendance: Augmentation du danger d'avalanche
leMardi 03 02 2026

Neige soufflée
(Neige ventée)

Limite de la forêt

Neige fraîche

PM:

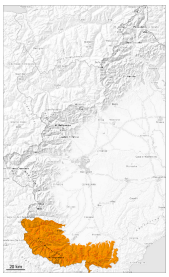

Tendance: Augmentation du danger d'avalanche
leMardi 03 02 2026

Neige soufflée
(Neige ventée)

Avec le vent parfois fort les endroits dangereux se multiplient.

Des accumulations de neige soufflée supplémentaires se forment avec le vent de sud-ouest modéré à fort en cours de journée. Elles peuvent être déclenchées par un seul amateur de sports d'hiver et atteindre une grande taille. Ceci surtout sur les pentes raides au-dessus de la limite de la forêt comme dans les combes, couloirs et derrière les ruptures de terrain.
À partir de l'après-midi il tombera de la neige jusqu'à basse altitude. Les endroits dangereux sont à peine identifiables par mauvaise visibilité. Les randonnées à ski, descentes hors-piste et randonnées en raquettes demandent prudence et retenue.

Manteau neigeux

Modèles de danger md.6: froid, neige légère et vent

À partir de l'après-midi il tombera de la neige jusqu'à basse altitude. Avec le vent de sud-ouest modéré à fort, de nouvelles accumulations de neige soufflée se forment.
Le manteau neigeux est meuble, avec une surface de neige meuble. Ceci aux endroits à l'ombre et abrités du vent à basse et moyenne altitude.

Tendance

Augmentation du danger d'avalanches avec la neige fraîche et le vent.

Degré de danger 3 - Marqué

Limite de la forêt

Tendance: danger d'avalanche constant
leMardi 03 02 2026

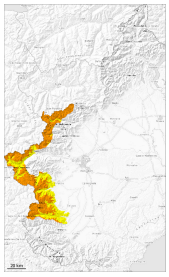

Neige soufflée
(Neige ventée)

Limite de la forêt

Neige
ancienne
(Sous-couche
fragile
persistante)

En altitude danger d'avalanches marqué. Avec le vent parfois modéré les endroits dangereux se multiplient.

L'après-midi il tombera un peu de neige. Les endroits dangereux sont à peine identifiables par mauvaise visibilité. Les accumulations de neige soufflée peuvent par endroits être déclenchées par un seul amateur de sports d'hiver et atteindre une grande taille. Ceci surtout sur les pentes raides aussi au-dessus de la limite de la forêt comme dans les combes, couloirs et derrière les ruptures de terrain à moyenne et haute altitude.
Des avalanches peuvent être déclenchées surtout sur les pentes raides à l'ombre dans les couches plus profondes du manteau neigeux. Des bruits sourds et des fissures lors du passage sur le manteau neigeux ainsi que des départs spontanés d'avalanches sont des signes nets d'une structure fragile du manteau neigeux.
Un choix prudent d'itinéraire et des distances de délestage sont recommandés.

Manteau neigeux

Modèles de danger md.6: froid, neige légère et vent | md.1: sous-couche fragile persistante

Des accumulations de neige soufflée supplémentaires se forment avec le vent. La neige fraîche et la neige soufflée se déposeront sur des couches meubles surtout sur les pentes protégées du vent à l'ombre.

Aux altitudes moyennes et élevées: Dans la partie inférieure du manteau neigeux des couches fragiles isolées susceptibles d'être déclenchées sont présentes, surtout sur les pentes très raides à l'ombre.

Degré de danger 3 - Marqué

Limite de la forêt

Tendance: danger d'avalanche constant
leMardi 03 02 2026

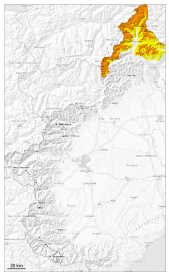

Neige soufflée
(Neige ventée)

Limite de la forêt

Neige
ancienne
(Sous-couche
fragile
persistante)

En altitude danger d'avalanches marqué. Avec le vent modéré à fort les endroits dangereux se multiplient en cours de journée.

Avec le vent modéré des avalanches de plaque de neige de moyenne et rarement grande taille sont possibles surtout sur les pentes raides et à proximité des crêtes et des cols.
Les accumulations de neige soufflée fragiles peuvent être parfois déclenchées par un seul amateur de sports d'hiver.
Les avalanches peuvent se déclencher dans les couches profondes surtout sur les pentes très raides à l'ombre et atteindre une grande taille.
À partir de l'après-midi il tombera un peu de neige.

Manteau neigeux

Modèles de danger md.6: froid, neige légère et vent | md.1: sous-couche fragile persistante

Le vent modéré transporte la neige. Les accumulations de neige soufflée fraîches se déposeront sur une surface de neige ancienne défavorable.

Dans le manteau neigeux des couches fragiles ayant subi une métamorphose constructive à grains anguleux sont présentes sur les pentes raides à l'ombre.

Degré de danger 3 - Marqué

AM:

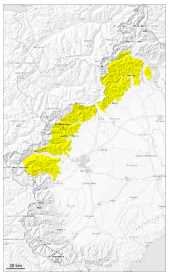

Tendance: danger d'avalanche constant
leMardi 03 02 2026

Neige soufflée
(Neige ventée)

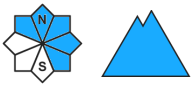

PM:

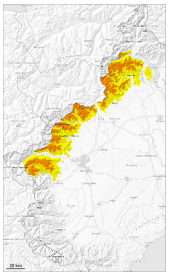

Limite de la forêt

Tendance: danger d'avalanche constant
leMardi 03 02 2026

Neige soufflée
(Neige ventée)

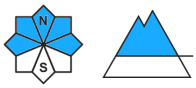

Limite de la forêt

Neige soufflée
(Neige ventée)

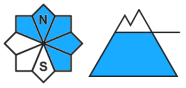

Limite de la forêt

Avec le vent parfois fort les endroits dangereux se multiplient en cours de journée.

Des accumulations de neige soufflée supplémentaires se forment avec le vent partiellement modéré en cours de journée. Elles peuvent être déjà déclenchées de manière isolée avec une surcharge faible et atteindre une taille dangereuse. Ceci surtout sur les pentes raides au-dessus de la limite de la forêt comme dans les combes, couloirs et derrière les ruptures de terrain.
L'après-midi il tombera un peu de neige. Les endroits dangereux sont à peine identifiables par mauvaise visibilité. Les randonnées à ski, descentes hors-piste et randonnées en raquettes demandent un choix très prudent d'itinéraires.

Manteau neigeux

Modèles de danger md.6: froid, neige légère et vent | md.1: sous-couche fragile persistante

Le vent modéré transporte la neige. Les accumulations de neige soufflée fraîches se déposeront sur des couches défavorables.

Le manteau neigeux est meuble, avec une surface de neige meuble. Ceci aux endroits à l'ombre et abrités du vent aussi à basse et moyenne altitude.
Dans le manteau neigeux des couches fragiles ayant subi une métamorphose constructive à grains anguleux sont présentes sur les pentes raides à l'ombre.