Lunedì 02.02.2026

Aggiornato02.02.2026 alle ore 08:00

Mattina

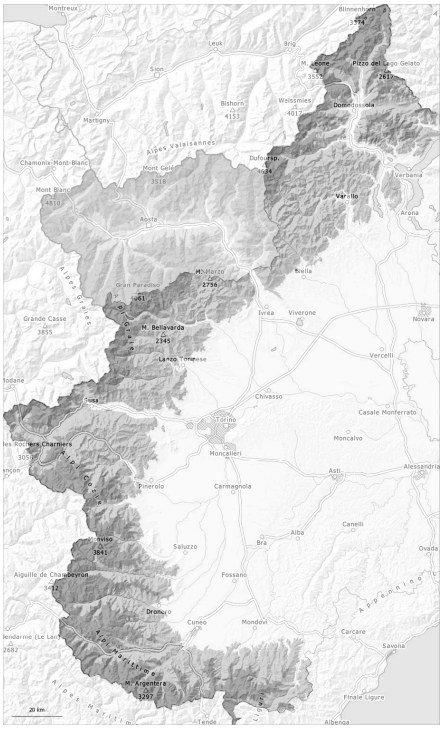

pomeriggio

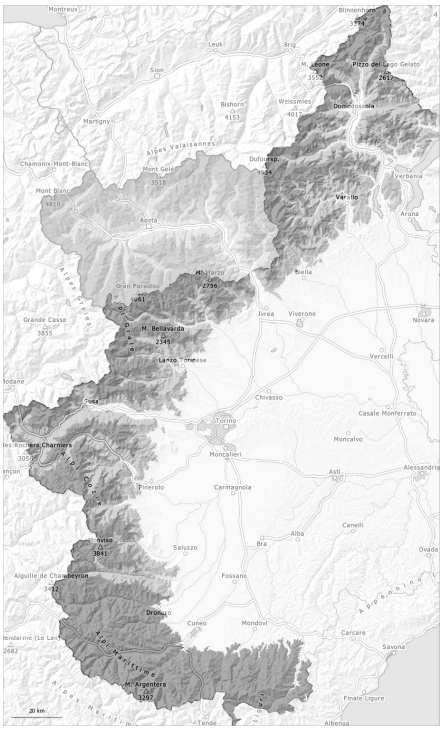

1	2	3	4	5
debole	moderato	marcato	forte	molto forte

Grado di pericolo 3 - Marcato

AM:

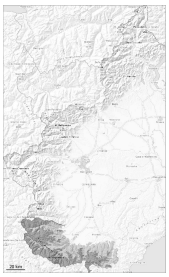

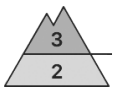

Limite del bosco

Tendenza: pericolo valanghe in aumento
per Martedì il 03.02.2026

Lastrone da vento

Limite del bosco

Neve fresca

PM:

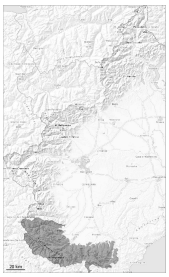

Tendenza: pericolo valanghe in aumento
per Martedì il 03.02.2026

Lastrone da vento

Con il vento a tratti forte, i punti pericolosi aumenteranno.

Con vento da moderato a forte proveniente da sud ovest nel corso della giornata si formeranno ulteriori accumuli di neve ventata. Essi possono distaccarsi in seguito al passaggio di un singolo appassionato di sport invernali e raggiungere grandi dimensioni. Ciò soprattutto sui pendii ripidi al di sopra del limite del bosco, come pure nelle conche, nei canaloni e dietro ai cambi di pendenza.
A partire dal pomeriggio cadrà neve sino a bassa quota. I punti pericolosi sono con il cattivo tempo appena individuabili. Le escursioni con gli sci e le racchette da neve, così come le discese fuori pista richiedono attenzione e prudenza.

Manto nevoso

Situazione tipo st.6: neve a debole coesione e vento

A partire dal pomeriggio cadrà neve sino a bassa quota. Con il vento da moderato a forte proveniente da sud ovest, si formeranno nuovi accumuli di neve ventata.
Il manto nevoso è soffice, con una superficie formata da neve a debole coesione. Ciò nelle zone ombreggiate e riparate dal vento alle quote di bassa e media montagna.

Tendenza

Con neve fresca e vento, aumento del pericolo di valanghe.

Grado di pericolo 3 - Marcato

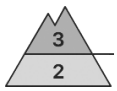

Limite del bosco

Tendenza: pericolo valanghe stabile
per Martedì il 03.02.2026

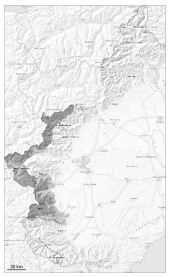

Lastrone da vento

Limite del bosco

Strati deboli persistenti

In quota marcato pericolo di valanghe. Con il vento a tratti moderato, i punti pericolosi aumenteranno.

Durante il pomeriggio cadrà un po' di neve. I punti pericolosi sono con il cattivo tempo appena individuabili. Gli accumuli di neve ventata possono in alcuni punti distaccarsi in seguito al passaggio di un singolo appassionato di sport invernali e raggiungere grandi dimensioni. Ciò soprattutto sui pendii ripidi anche al di sopra del limite del bosco, come pure nelle conche, nei canaloni e dietro ai cambi di pendenza alle quote medie e alte.
Le valanghe possono subire un distacco negli strati più profondi del manto nevoso specialmente sui pendii ripidi ombreggiati. I rumori di "whum" e la formazione di fessure quando si calpesta la coltre di neve così come i distacchi spontanei di valanghe sono i tipici indizi di una debole struttura del manto nevoso.
Si consiglia una prudente scelta dell'itinerario e di mantenere le distanze di scarico.

Manto nevoso

Situazione tipo st.6: neve a debole coesione e vento | st.1: strato debole persistente basale

Con vento si formeranno ulteriori accumuli di neve ventata. La neve fresca e la neve ventata si depositeranno su strati soffici soprattutto sui pendii riparati dal vento ombreggiati.

Alle quote medie e alte: Soprattutto sui pendii ombreggiati molto ripidi, nella parte basale del manto nevoso si trovano, a livello isolato, strati fragili instabili.

Grado di pericolo 3 - Marcato

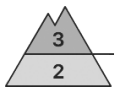

Limite del bosco

Tendenza: pericolo valanghe stabile
per Martedì il 03.02.2026

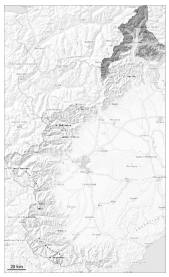

Lastrone da vento

Limite del bosco

Strati deboli persistenti

In quota marcato pericolo di valanghe. Con il vento da moderato a forte, nel corso della giornata i punti pericolosi aumenteranno.

Con il vento di moderata intensità, specialmente sui pendii ripidi e nelle zone in prossimità delle creste e dei passi sono possibili valanghe di neve a lastroni di medie e, a livello isolato, di grandi dimensioni.
Gli accumuli di neve ventata instabili possono in parte subire un distacco in seguito al passaggio di un singolo appassionato di sport invernali.
Specialmente sui pendii ombreggiati molto ripidi le valanghe possono coinvolgere gli strati più profondi del manto nevoso e raggiungere grandi dimensioni.
A partire dal pomeriggio cadrà un po' di neve.

Manto nevoso

Situazione tipo st.6: neve a debole coesione e vento | st.1: strato debole persistente basale

Il vento moderato causerà il trasporto della neve. Gli accumuli di neve ventata di più recente formazione verranno depositati su una sfavorevole superficie del manto di neve vecchia.

Sui pendii ombreggiati ripidi, all'interno del manto nevoso si trovano strati fragili a cristalli angolari.

Grado di pericolo 3 - Marcato

AM:

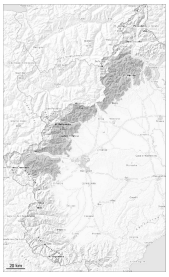

Tendenza: pericolo valanghe stabile
per Martedì il 03.02.2026

Lastrone da vento

PM:

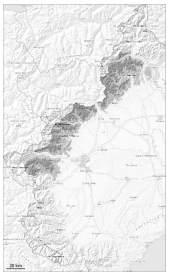

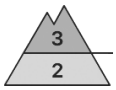

Limite del bosco

Tendenza: pericolo valanghe stabile
per Martedì il 03.02.2026

Lastrone da vento

Limite del bosco

Lastrone da vento

Limite del bosco

Con il vento a tratti forte, nel corso della giornata i punti pericolosi aumenteranno.

Con vento in parte moderato nel corso della giornata si formeranno ulteriori accumuli di neve ventata. Essi possono distaccarsi a livello isolato già con un debole sovraccarico e raggiungere dimensioni pericolosamente grandi. Ciò soprattutto sui pendii ripidi al di sopra del limite del bosco, come pure nelle conche, nei canaloni e dietro ai cambi di pendenza.
Durante il pomeriggio cadrà un po' di neve. I punti pericolosi sono con il cattivo tempo appena individuabili. Le escursioni con gli sci e le racchette da neve, così come le discese fuori pista richiedono una prudente scelta dell'itinerario.

Manto nevoso

Situazione tipo st.6: neve a debole coesione e vento | st.1: strato debole persistente basale

Il vento moderato causerà il trasporto della neve. Gli accumuli di neve ventata di più recente formazione si depositeranno su strati sfavorevoli.

Il manto nevoso è soffice, con una superficie formata da neve a debole coesione. Ciò nelle zone ombreggiate e riparate dal vento anche alle quote di bassa e media montagna.
Sui pendii ombreggiati ripidi, all'interno del manto nevoso si trovano strati fragili a cristalli angolari.