Montag 02.02.2026

Aktualisiert am 02.02.2026 um 08:00

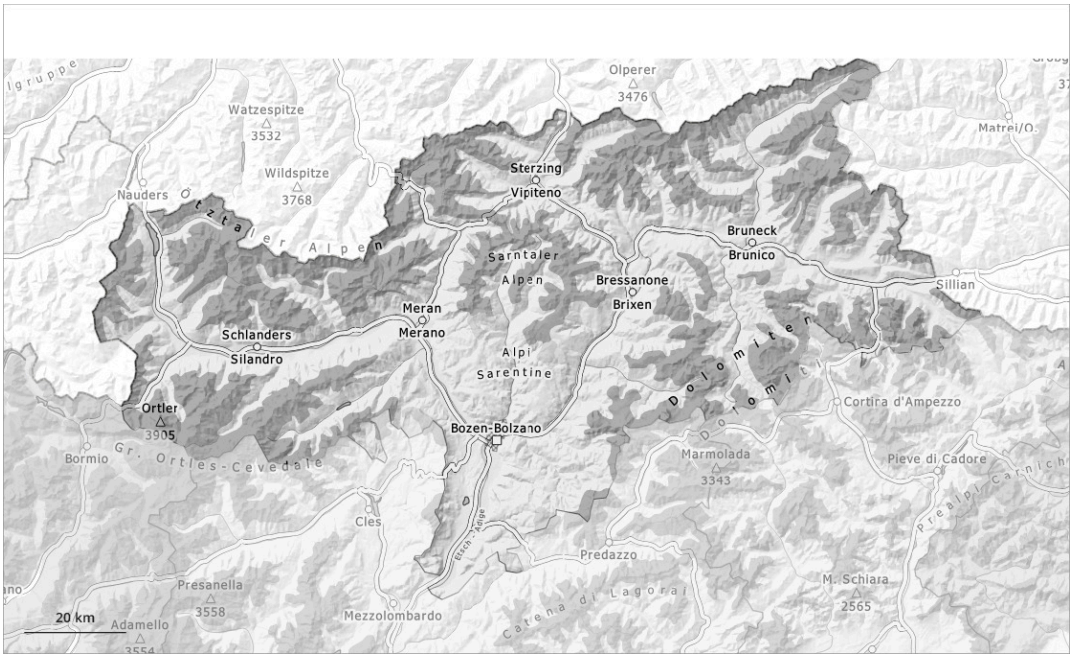

1	2	3	4	5
gering	mäßig	erheblich	groß	sehr groß

Gefahrenstufe 3 - Erheblich

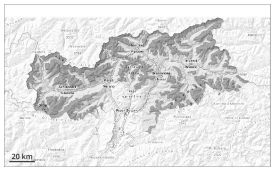

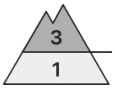

Waldgrenze

Tendenz: Lawinengefahr steigt
am Dienstag, den 03.02.2026

Altschnee

Waldgrenze

Weiterhin heimtückische Lawinensituation. Schwacher Altschnee ist die Hauptgefahr.

Der Neuschnee sowie die verbreitet vorhandenen Triebschneeansammlungen überlagern vor allem an West-, Nord- und Osthängen oberhalb der Waldgrenze eine schwache Altschneedecke, vereinzelt auch im Bereich der Waldgrenze und an steilen Sonnenhängen in der Höhe. Lawinen können leicht ausgelöst werden und mittlere Größe erreichen. Fernauslösungen sind möglich.

Die Gefahrenstellen sind weit verbreitet und kaum zu erkennen. Anzahl und Größe der Gefahrenstellen nehmen mit der Höhe zu. Vorsicht in Kammlagen, Rinnen und Mulden. Wummgeräusche und Risse beim Betreten der Schneedecke sowie frische Lawinen sind Alarmzeichen und weisen auf die Gefahr hin.

Beobachtungen im Gelände und frische Lawinen bestätigen die heimtückische Lawinensituation. Vorsicht und Zurückhaltung sind empfohlen.

Schneedecke

Gefahrenmuster gm.1: bodennahe schwachschicht | gm.8: eingeschneiter oberflächenreif

Neu- und Triebschnee überlagern eine schwache Altschneedecke. In der Altschneedecke sind ausgeprägte Schwachschichten vorhanden. Dies besonders an West-, Nord- und Osthängen.

An steilen Sonnenhängen gefriert die Schneedecke nicht tragfähig, vor allem unterhalb von rund 2400 m.

Tendenz

Schwachschichten im Altschnee können weiterhin von einzelnen Wintersportlern ausgelöst werden. Es fallen vor allem im Süden bis zu 15 cm Schnee. Der teilweise stürmische Wind verfrachtet Neu- und Altschnee intensiv. Die Lawinenaktivität nimmt zu.

Gefahrenstufe 2 - Mäßig

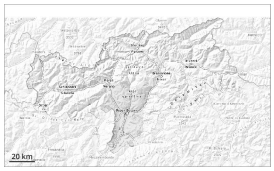

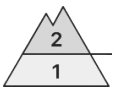

Waldgrenze

Tendenz: Lawinengefahr bleibt gleich
am Dienstag, den 03.02.2026

Triebschnee

Waldgrenze

Lawinen können vereinzelt ausgelöst werden, sind aber meist klein.

Lawinen können vereinzelt ausgelöst werden, sind aber meist klein. Vorsicht vor allem an sehr steilen Schattenhängen sowie in Kammlagen, Rinnen und Mulden oberhalb der Waldgrenze.

Nebst der Verschüttungsgefahr sollte vor allem die Mitreiß- und Absturzgefahr beachtet werden.

Schneedecke

Die eher kleinen Triebschneeansammlungen der letzten Tage liegen in der Höhe auf einer ungünstigen Altschneeoberfläche. Die Altschneedecke ist aufbauend umgewandelt.

Die Schneedecke ist allgemein kleinräumig sehr unterschiedlich.

Tendenz

Vorsicht vor Triebschnee.