Lunedì 02.02.2026

Aggiornato02.02.2026 alle ore 08:00

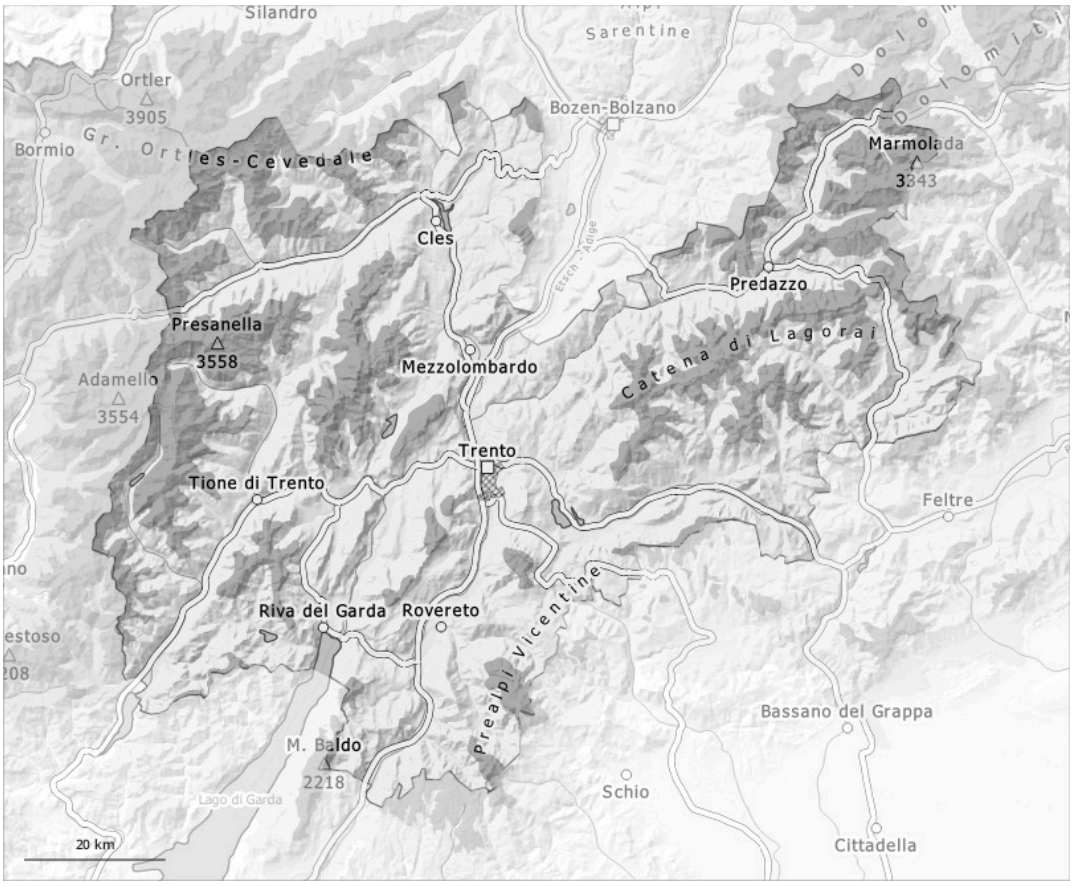

1	2	3	4	5
debole	moderato	marcato	forte	molto forte

Grado di pericolo 3 - Marcato

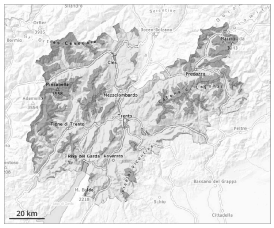

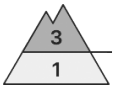

Limite del bosco

Tendenza: pericolo valanghe in aumento
per Martedì il 03.02.2026

Strati deboli persistenti

Limite del bosco

Al di fuori delle piste assicurate, la situazione valanghiva è molto delicata.

La neve fresca così come gli accumuli di neve ventata presenti in molti punti ricoprono un debole manto di neve vecchia soprattutto sui pendii esposti a ovest, nord ed est al di sopra del limite del bosco. Le valanghe possono facilmente subire un distacco e raggiungere dimensioni medie. Sono possibili distacchi a distanza.

I punti pericolosi sono molto diffusi e facilmente individuabili dall'escursionista esperto. Il numero e le dimensioni dei punti pericolosi aumenteranno con l'altitudine. Attenzione nelle conche, nei canaloni e dietro ai cambi di pendenza. I rumori di "whum" e la formazione di fessure quando si calpesta la coltre di neve così come i distacchi spontanei di valanghe sono campanelli di allarme che rimandano a questo pericolo.
Le osservazioni sul territorio e gli esiti positivi dei distacchi programmati di valanghe confermano la struttura instabile del manto nevoso. Sono raccomandate attenzione e prudenza.
Con le precipitazioni, leggero aumento del pericolo di valanghe.

Manto nevoso

Situazione tipo st.6: neve a debole coesione e vento

La neve fresca e la neve ventata ricoprono un debole manto di neve vecchia. All'interno del manto di neve vecchia si trovano pronunciati strati fragili. Ciò specialmente sui pendii esposti a ovest, nord ed est.

Tendenza

Con le nevicate, leggero aumento del pericolo di valanghe. Le valanghe possono ancora distaccarsi già in seguito al passaggio di un singolo appassionato di sport invernali. Il manto nevoso rimane instabile.