ICGC Institut Cartogràfic i Geològic de Catalunya

Servei Meteorològic de Catalunya meteo.cat

Boletín de peligro de aludes para el Pirineo de Catalunya
Del 02/02/2026 al 03/02/2026

(Válido fuera pistas de esquí y zonas no controladas)

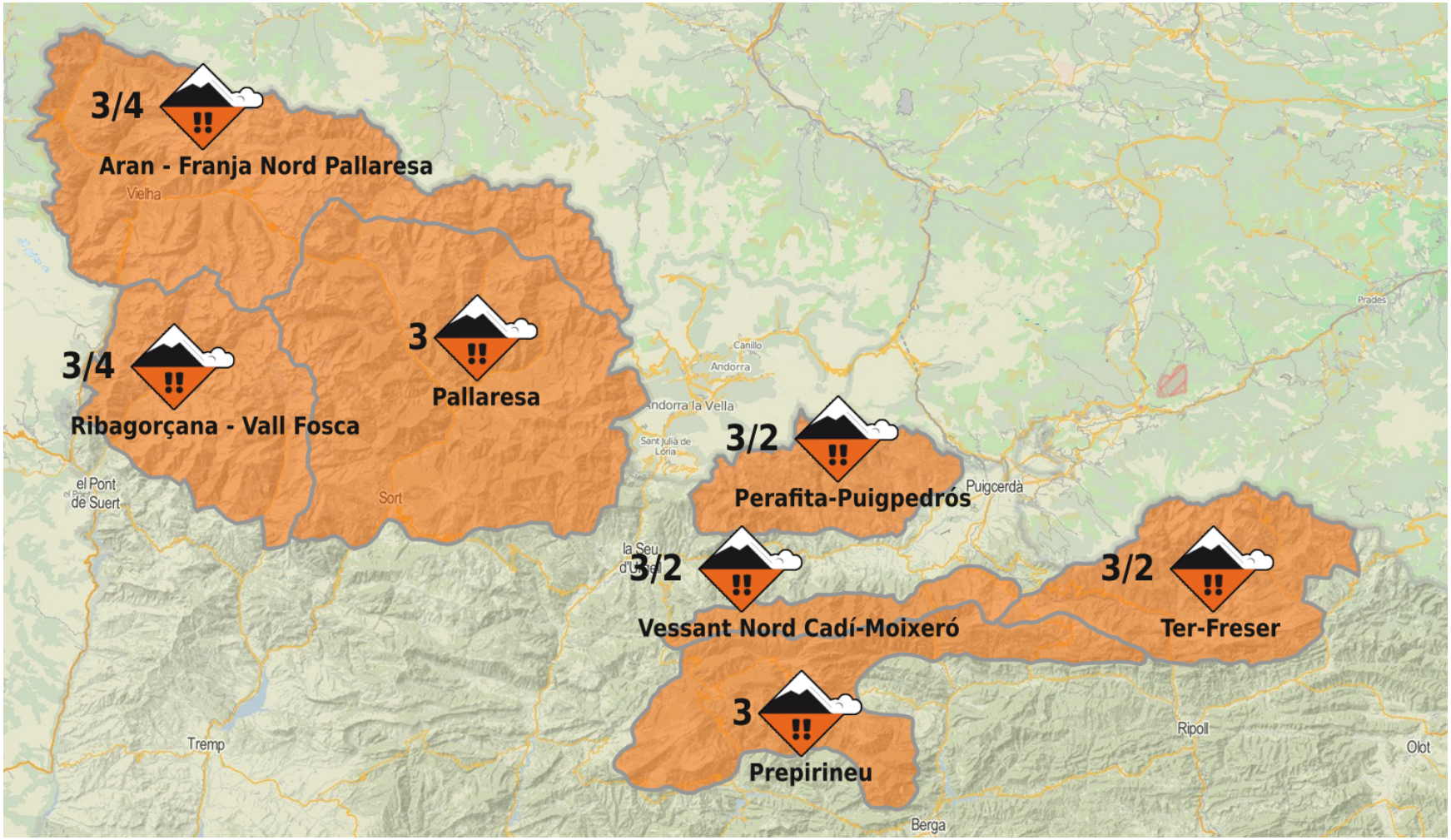

5 MUY FUERTE	4 FUERTE	3 NOTABLE	2 LIMITADO	1 DÉBIL

ICGC Institut Cartogràfic i Geològic de Catalunya

Servei Meteorològic de Catalunya meteo.cat

Boletín de peligro de aludes Aran - Franja Nord Pallaresa Del 02/02/2026 al 03/02/2026

(Válido fuera pistas de esquí y zonas no controladas)

NOTABLE (3) martes. FUERTE (4) lunes extremo S Aran y Franja N Pallaresa.

Situación primaria

Nieve venteada

Distribución

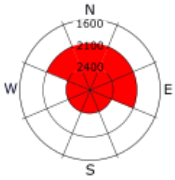

Tamaño

Origen

Tendencia

Situación secundaria

Nieve húmeda

Distribución

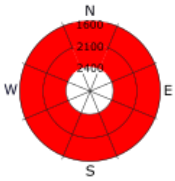

Tamaño

Origen

Tendencia

Estado del manto nivoso

La nevada del lunes con lluvia hasta 2.300 m (aprox 25 cm en cotas altas del extremo sur del Aran y en la Franja Norte de la Pallaresa) mantendrá el manto húmedo hasta la noche del lunes-madrugada del martes. Serán muy probables aludes naturales de nieve húmeda de tamaño 2, mediano, a cualquier orientación por debajo de 2.300 m. El descenso de la cota de nieve hasta fondo de valle durante la noche del lunes, por enfriamiento eliminará este problema de cara al martes. Con el viento fuerte de S y W, se habrán formado placas de viento frágiles; lunes y martes se esperan aludes naturales de placa de viento en orientaciones NW, N, NE y E, por lo general de tamaño 3, grande, suficiente para cubrir un grupo de personas. El lunes se han reactivado los deslizamientos basales, de tamaño 2. El lunes se recomienda no realizar actividades cerca de terreno alaboso. El martes habrá aludes de nieve reciente especialmente cuando salga el sol, de tamaño 2, menos probables en la mitad norte del Aran.

Distribución del manto nivoso

Hay nieve en el suelo a 800 m. El manto es esquiable por encima de unos 1.500 m. Los espesores a unos 2.200 m rondan los 100-130 cm en el norte del Arán y 120-170 cm en la Franja Norte Pallaresa y en el sur del Aran, y son superiores a los normales por estas fechas.

Tendencia para las próximas 48-72h

Se mantendrá la fragilidad de las placas de viento en cotas altas, ya que el viento del W continuará transportando nieve. Habrá un progresivo asentamiento interno en laderas soleadas a cotas medias y bajas. Peligro EN LIGERO DESCENSO.

El próximo boletín será emitido el día 2026-02-03

5 MUY FUERTE	4 FUERTE	3 NOTABLE	2 LIMITADO	1 DÉBIL

EAWS EUROPEAN AVALANCHE WARNING SERVICES

ICGC Institut Cartogràfic i Geològic de Catalunya

Servei Meteorològic de Catalunya meteo.cat

Boletín de peligro de aludes Ribagorçana - Vall Fosca Del 02/02/2026 al 03/02/2026

(Válido fuera pistas de esquí y zonas no controladas)

NOTABLE (3) el martes.
FUERTE (4) el lunes.

Situación primaria

Nieve venteada

Distribución

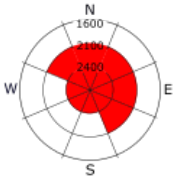

Tamaño

Origen

Tendencia

Situación secundaria

Nieve húmeda

Distribución

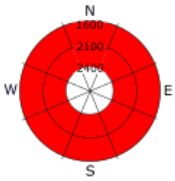

Tamaño

Origen

Tendencia

Estado del manto nivoso

La nevada del lunes con lluvia hasta 2.200-2.300 m (aprox 30 cm en cotas altas) mantendrá el manto húmedo hasta la noche del lunes-madrugada del martes. En este período serán muy probables aludes naturales de nieve húmeda de tamaño 2, mediano, a cualquier orientación por debajo de 2.300 m. El descenso de la cota de nieve hasta fondo de valle durante la noche del lunes, por enfriamiento eliminará este problema cara al martes. Con el viento fuerte de S y W, se habrán formando placas de viento frágiles; lunes y martes se esperan aludes naturales de placa de viento en orientaciones NW, N, NE y E, por lo general de tamaño 3, grande, suficiente para cubrir un grupo de personas. Se recomienda el lunes no realizar actividades cerca de terreno avalanchoso.

Distribución del manto nivoso

Hay nieve en el suelo a 1.300 m. El manto es esquiable por encima de unos 1.500 m. Los grosores alcanzan los 110-140 cm. Estos valores son muy superiores a los normales en la época.

Tendencia para las próximas 48-72h

Se mantendrá la fragilidad de las placas de viento en cotas altas, ya que el viento del W continuará transportando nieve. Habrá un progresivo asentamiento interno en laderas soleadas en cotas medias y bajas. Peligro EN LIGERO DESCENSO.

El próximo boletín será emitido el día 2026-02-03

5 MUY FUERTE	4 FUERTE	3 NOTABLE	2 LIMITADO	1 DÉBIL

EAWS EUROPEAN AVALANCHE WARNING SERVICES

ICGC Institut Cartogràfic i Geològic de Catalunya

Servei Meteorològic de Catalunya

Boletín de peligro de aludes Pallaresa
Del 02/02/2026 al 03/02/2026

(Válido fuera pistas de esquí y zonas no controladas)

NOTABLE (3).

Situación primaria

Nieve venteada

Distribución

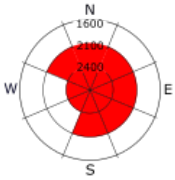

Tamaño

Origen

Tendencia

Situación secundaria

Nieve húmeda

Distribución

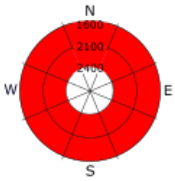

Tamaño

Origen

Tendencia

Estado del manto nivoso

La nevada del lunes con lluvia hasta 2.200-2.300 m (20-30 cm en cotas altas) mantendrá el manto húmedo hasta la noche del lunes-madrugada del martes. En este período serán muy probables aludes naturales de nieve húmeda de tamaño 2, media, a cualquier orientación por debajo de 2.200 m. El descenso de la cota de nieve hasta fondo de valle durante la noche del lunes, por enfriamiento eliminará este problema cara al martes. Con el viento fuerte de S y W, se están formando placas de viento frágiles; lunes y martes se esperan aludes naturales de placa de viento en orientaciones NW, N, NE y E, por lo general de tamaño 2, medio, suficiente para cubrir una persona; puntualmente en las cotas más altas de hasta tamaño 3, grande, suficiente para cubrir a un grupo de personas.

Distribución del manto nivoso

Hay nieve desde 1.300 m, esquiable a 1.500 m. Los espesores en cotas altas y medias rondan o superan los 130 cm. Estos valores son superiores a los normales para la época.

Tendencia para las próximas 48-72h

Se mantendrá la fragilidad de las placas de viento en cotas altas, ya que el viento del W continuará transportando nieve. Habrá un progresivo asentamiento interno en laderas soleadas a cotas medias y bajas. Peligro EN LIGERO DESCENSO.

El próximo boletín será emitido el día 2026-02-03

5 MUY FUERTE	4 FUERTE	3 NOTABLE	2 LIMITADO	1 DÉBIL

EAWS EUROPEAN AVALANCHE WARNING SERVICES

ICGC Institut Cartogràfic i Geològic de Catalunya

Servei Meteorològic de Catalunya

Boletín de peligro de aludes Perafita-Puigpedrós Del 02/02/2026 al 03/02/2026

(Válido fuera pistas de esquí y zonas no controladas)

NOTABLE (3) por encima de 2.300 m.
LIMITADO (2) por debajo.

Situación primaria

Nieve venteada

Distribución

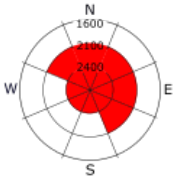

Tamaño

Origen

Tendencia

Situación secundaria

Nieve húmeda

Distribución

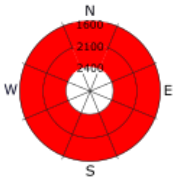

Tamaño

Origen

Tendencia

Estado del manto nivoso

La nevada del lunes con lluvia hasta 2.200-2.300 m (5-10 cm en cotas altas) mantendrá el manto húmedo hasta la noche del lunes-madrugada del martes. En este período serán muy probables aludes naturales de nieve húmeda de tamaño 1, pequeño, a cualquier orientación por debajo de 2.300 m. El descenso de la cota de nieve hasta fondo de valle durante la noche del lunes, por enfriamiento eliminará este problema cara al martes. Con el viento fuerte de S y W, se están formando placas de viento frágiles; lunes y martes por encima de 2.300 m se esperan aludes naturales de placa de viento en orientaciones NW, N, NE y E, por lo general de tamaño 2, mediano, suficiente para cubrir una persona; puntualmente bajo amplios collados en las cotas más altas de hasta tamaño 3, grande, suficiente para cubrir un grupo de personas.

Distribución del manto nivoso

Hay nieve en el suelo por encima de 1.300 m. Sin embargo, el manto es esquiable por encima de 1.500-1.600 m. Los grosores alcanzan los 110-130 cm a 2.200 m. Son grosores muy por encima de los habituales por la época.

Tendencia para las próximas 48-72h

Se mantendrá la fragilidad de las placas de viento en cotas altas, ya que el viento del W continuará transportando nieve. Habrá un progresivo encostramiento y estabilización en laderas soleadas en cotas medias y bajas. Peligro EN LIGERO DESCENSO.

El próximo boletín será emitido el día 2026-02-03

5 MUY FUERTE	4 FUERTE	3 NOTABLE	2 LIMITADO	1 DÉBIL

EAWS EUROPEAN AVALANCHE WARNING SERVICES

ICGC Institut Cartogràfic i Geològic de Catalunya

Servei Meteorològic de Catalunya

Boletín de peligro de aludes Vessant Nord Cadí-Moixeró Del 02/02/2026 al 03/02/2026

(Válido fuera pistas de esquí y zonas no controladas)

NOTABLE (3) por encima de 2.300 m.
LIMTADO (2) por debajo.

Situación primaria

Nieve venteada

Distribución

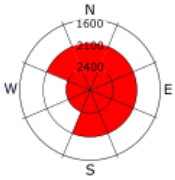

Tamaño

Origen

Tendencia

Situación secundaria

Nieve húmeda

Distribución

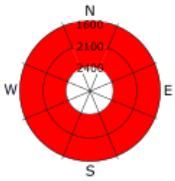

Tamaño

Origen

Tendencia

Estado del manto nivoso

La nevada del lunes con lluvia hasta 2.200-2.300 m (5-10 cm en cotas altas) mantendrá el manto húmedo hasta la noche del lunes-madrugada del martes. En este período serán muy probables aludes naturales de nieve húmeda de tamaño 1, pequeño, a cualquier orientación por debajo de 2.300 m. El descenso de la cota de nieve hasta fondo de valle durante la noche del lunes, por enfriamiento eliminará este problema cara al martes. Con el viento fuerte de S y W, se están formando placas de viento frágiles; lunes y martes por encima de 2.300 m se esperan aludes naturales de placa de viento en orientaciones NW, N, NE y E, por lo general de tamaño 2, medio, suficiente para cubrir una persona; puntualmente en la parte superior de las canales de hasta tamaño 3, grande, suficiente para cubrir a un grupo de personas.

Distribución del manto nivoso

Hay nieve desde 1.200 a 1.300 m, esquiable por encima de unos 1.500 m. Los grosores están alrededor de 100-140 cm a 2.200 m, valores muy excedentarios para la época del año.

Tendencia para las próximas 48-72h

Se mantendrá la fragilidad de las placas de viento en cotas altas, ya que el viento del W continuará transportando nieve. Habrá un progresivo encostramiento y estabilización en laderas soleadas en cotas medias y bajas. Peligro EN LIGERO DESCENSO.

El próximo boletín será emitido el día 2026-02-03

5 MUY FUERTE	4 FUERTE	3 NOTABLE	2 LIMITADO	1 DÉBIL

EAWS EUROPEAN AVALANCHE WARNING SERVICES

ICGC Institut Cartogràfic i Geològic de Catalunya

Servei Meteorològic de Catalunya

Boletín de peligro de aludes Prepirineu
Del 02/02/2026 al 03/02/2026

(Válido fuera pistas de esquí y zonas no controladas)

NOTABLE (3).

Situación primaria

Nieve venteada

Distribución

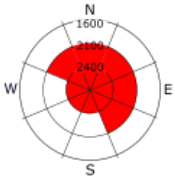

Tamaño

Origen

Tendencia

Situación secundaria

Nieve húmeda

Distribución

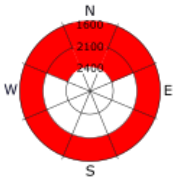

Tamaño

Origen

Tendencia

Estado del manto nivoso

La nevada del lunes con lluvia hasta 2.200 m (15-20 cm en cotas altas) mantendrá el manto húmedo hasta la noche del lunes-madrugada del martes. En este período serán muy probables aludes naturales de nieve húmeda de tamaño 2, media, a cualquier orientación por debajo de 2.200 m. El descenso de la cota de nieve hasta fondo de valle durante la noche del lunes, por enfriamiento eliminará este problema cara al martes. Con el viento fuerte de S y W, se están formando placas de viento frágiles; lunes y martes se esperan aludes naturales de placa de viento en orientaciones NW, N, NE y E, por lo general de tamaño 2, mediano, suficiente para cubrir una persona; puntualmente en las cotas más altas de hasta tamaño 3, grande, suficiente para cubrir a un grupo de personas.

Distribución del manto nivoso

Hay nieve desde 1.300 m. El manto es esquiable a partir de 1.600 m. Los grosores están alrededor de 90-110 cm a unos 2.200 m; son superiores a los habituales.

Tendencia para las próximas 48-72h

Se mantendrá la fragilidad de las placas de viento en cotas altas, ya que el viento del W continuará transportando nieve. Habrá un progresivo encostramiento y estabilización en laderas soleadas en cotas medias y bajas. Peligro EN LIGERO DESCENSO.

El próximo boletín será emitido el día 2026-02-03

5 MUY FUERTE	4 FUERTE	3 NOTABLE	2 LIMITADO	1 DÉBIL

EAWS EUROPEAN AVALANCHE WARNING SERVICES

ICGC Institut Cartogràfic i Geològic de Catalunya

meteo.cat Servei Meteorològic de Catalunya

Boletín de peligro de aludes Ter-Freser
Del 02/02/2026 al 03/02/2026

(Válido fuera pistas de esquí y zonas no controladas)

NOTABLE (3) por encima de 2.300 m.
LIMITADO (2) por debajo.

Situación primaria

Nieve venteada

Distribución

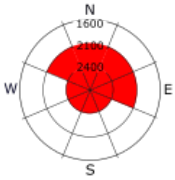

Tamaño

Origen

Tendencia

Situación secundaria

Nieve húmeda

Distribución

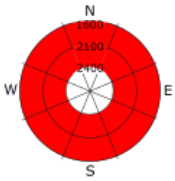

Tamaño

Origen

Tendencia

Estado del manto nivoso

La nevada del lunes con lluvia hasta 2.200-2.300 m (1-5 cm en cotas altas) mantendrá el manto húmedo hasta la noche del lunes-madrugada del martes. En este período serán muy probables aludes naturales de nieve húmeda de tamaño 1, pequeño, a cualquier orientación por debajo de 2.300 m. El descenso de la cota de nieve hasta fondo de valle durante la noche del lunes, por enfriamiento eliminará este problema cara al martes. Con el viento fuerte de S y W, se están formando placas de viento frágiles; lunes y martes por encima de 2.300 m se esperan aludes naturales de placa de viento en orientaciones NW, N, NE y E, por lo general de tamaño 2, medio, suficiente para cubrir una persona; puntualmente bajo amplios collados en las cotas más altas de hasta tamaño 3, grande, suficiente para cubrir un grupo de personas.

Distribución del manto nivoso

Hay nieve desde 1.300 m, esquiable por encima de 1.500 a 1.600 m. Los espesores rondan los 90-130 cm a unos 2.000 my son muy excedentarios para la época del año.

Tendencia para las próximas 48-72h

Se mantendrá la fragilidad de las placas de viento en cotas altas, ya que el viento del W continuará transportando nieve. Habrá un progresivo encostramiento y estabilización en laderas soleadas en cotas medias y bajas. Peligro EN LIGERO DESCENSO.

El próximo boletín será emitido el día 2026-02-03

5 MUY FUERTE	4 FUERTE	3 NOTABLE	2 LIMITADO	1 DÉBIL

EAWS EUROPEAN AVALANCHE WARNING SERVICES