MINISTERO DELLA DIFESA

meteomont Servizio Nazionale di previsione neve e valanghe

EAWS EUROPEAN AVALANCHE WARNING SERVICES

CARABINIERI

In collaborazione con: arpav

DOLOMITI SETTENTRIONALI

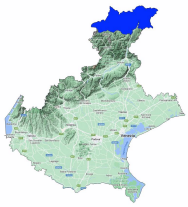

Bollettino Valanghe N. 333/2026 del 02/02/2026 ore 14.00
Validità 48 ore prossima emissione 03/02/2026

A cura del Servizio METEOMONT dell'ARMA dei CARABINIERI
In collaborazione con Servizio Meteorologico dell'Aeronautica militare

SITUAZIONE alle 14:00 del 02/02/2026

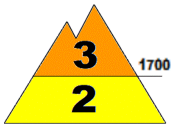

SITUAZIONE TIPO: nevicata dopo un lungo periodo di freddo.

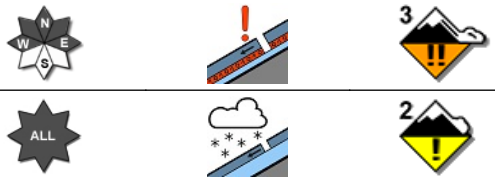

SITUAZIONE TIPO: nessuna situazione tipo evidente.

Quota neve (mslm)	Nord	Sud
	900 - 1100	900 - 1100

Altezza Neve (cm)	Neve al suolo	Neve Fresca	Quota (mslm)
	74	00	1930
	50	00	1530

VALANGHE OSSERVATE: Valanghe di piccole dimensioni, Valanghe di neve a debole coesione di superficie.

PREVISIONI 03/02/2026

GRADO DI PERICOLO: MARCATO 3

SITUAZIONE TIPO: neve a debole coesione e vento.



SITUAZIONE TIPO: neve a debole coesione e vento.

MANTO NEVOSO: La stabilità del manto nevoso è molto scarsa su alcuni punti (aree) per tutte le esposizioni al di sopra di 1700 mslm, possibili valanghe di dimensioni medie.
La stabilità del manto nevoso è molto scarsa su pochi punti (aree) per tutte le esposizioni al di sotto di 1700 mslm, possibili valanghe di dimensioni medie.

AVVERTENZE

In considerazione dei recenti apporti di neve fresca, è richiesta un'ottima valutazione locale della stabilità ed individuazione dell'itinerario.

SCALA EUROPEA DEL GRADO DI PERICOLO VALANGHE

LEGENDA PROBLEMA

Bollettino realizzato su scala sinottica-regionale (standard EAWS). La sua valutazione non può escludere in alcun modo la necessità di una seria e capace valutazione locale del pericolo (singolo pendio) che può essere anche sensibilmente diverso. Le previsioni meteorologiche sono relative all'orario UTC (per l'Italia +1 in inverno e +2 in estate).

MINISTERO DELLA DIFESA

meteomont
Servizio Nazionale di previsione neve e valanghe

EAWS EUROPEAN AVALANCHE WARNING SERVICES

CARABINIERI

In collaborazione con: arpav

DOLOMITI SETTENTRIONALI

PREVISIONE METEO

Quota		03/02/2026 h6:00	03/02/2026 h12:00	03/02/2026 h18:00
1000	Venti	02 Nodi da Sud	02 Nodi da Sud	01 Nodi da S-Est
	Temperature	-04 °C	-01 °C	-02 °C
	Temp.percepita	-4 °C	-1 °C	-2 °C
2000	Venti	05 Nodi da Sud	04 Nodi da Sud	02 Nodi da S-Est
	Temperature	-05 °C	-03 °C	-03 °C
	Temp.percepita	-9 °C	-6 °C	-3 °C
3000	Venti	17 Nodi da S-Ovest	11 Nodi da S-Ovest	07 Nodi da S-Ovest
	Temperature	-08 °C	-09 °C	-09 °C
	Temp.percepita	-17 °C	-17 °C	-15 °C
Zero termico		0700-0900 m.	1600-1800 m.	1400-1600 m.
Fenomeno				—
Stato del cielo				

LEGENDA FENOMENI

— Assenza Fenomeni · Nebbia · Foschia · Pioggia debole · Pioggia moderata · Pioggia forte · Temporali

Nevicata debole · Nevicata moderata · Nevicata forte

STATO DEL CIELO

Sereno · Poco nuvoloso · Nuvoloso · Molto nuvoloso · Coperto

Parametri meteonivometrici registrati presso i campi di rilevamento il 02/02/2026.

Località	Comune	Quota (m.s.l.m.)	Altezza neve (cm)	Neve caduta nelle 24 ore (cm)	Temp. Min (°C)	Temp. Max (°C)	Condizioni del tempo
MISURINA	Auronzo di Cadore (BL)	1759	50	0	-15	+17	Assenza di precipitazioni
MONTE AGUDO	Auronzo di Cadore (BL)	1530	50	0	-8	0	Assenza di precipitazioni
COL DELLA TENDA	Comelico Superiore (BL)	1930	74	0	-10	+8	Assenza di precipitazioni
PIAN DEI FIACCONI *	Canazei (TN)	2423	80	0	N.P.	N.P.	Assenza di precipitazioni

(*) Rilievi fuori campo

L'INFORMAZIONE E' PREVENZIONE - LEGGI L'ATTUALE GRADO DI PERICOLO VALANGHE!

IL CAPO DEL CENTRO NAZIONALE METEOMONT
(Ten. Col. RFI Emanuela Gini)
FIRMA AUTOGRAFA OMESSA AI SENSI
DELL'ART.3 DEL D.LGS N.39/1993