MINISTERO DELLA DIFESA

meteomont Servizio Nazionale di previsione neve e valanghe

EAWS EUROPEAN AVALANCHE WARNING SERVICES

CARABINIERI

PREALPI LOMBARDE

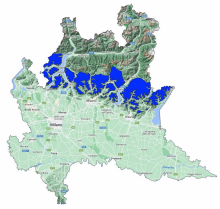

Bollettino Valanghe N. 332/2026 del 02/02/2026 ore 14.00
Validità 48 ore prossima emissione 03/02/2026

A cura del Servizio METEOMONT dell'ARMA dei CARABINIERI
In collaborazione con Servizio Meteorologico dell'Aeronautica militare

SITUAZIONE alle 14:00 del 02/02/2026

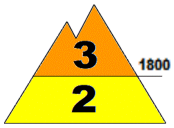

SITUAZIONE TIPO: passaggio da poca a molta neve.

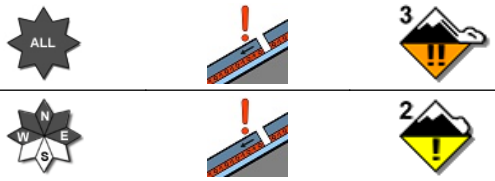

SITUAZIONE TIPO: passaggio da poca a molta neve.

Quota neve (mslm)	Nord	Sud
	1200 - 1300	1400 - 1600

Altezza Neve (cm)	Neve al suolo	Neve Fresca	Quota (mslm)
	60	0	2000
	057	0	1782

VALANGHE OSSERVATE: Valanghe di piccole dimensioni, Valanghe di neve a debole coesione di fondo.

PREVISIONI 03/02/2026

GRADO DI PERICOLO: FORTE 4

SITUAZIONE TIPO: brina di superficie sepolta.

SITUAZIONE TIPO: brina di superficie sepolta.

MANTO NEVOSO: La stabilità del manto nevoso è molto scarsa su molti punti (aree) per tutte le esposizioni al di sopra di 1800 mslm, possibili valanghe di dimensioni grandi.
La stabilità del manto nevoso è scarsa su alcuni punti (aree) per tutte le esposizioni al di sotto di 1800 mslm, possibili valanghe di dimensioni medie.

AVVERTENZE

In considerazione delle avverse condizioni meteorologiche in atto, le attività al di fuori delle piste battute e segnalate sono limitate. Se effettuate, richiedono ottime capacità di valutazione del pericolo locale.

SCALA EUROPEA DEL GRADO DI PERICOLO VALANGHE

LEGENDA PROBLEMA

Bollettino realizzato su scala sinottica-regionale (standard EAWS). La sua valutazione non può escludere in alcun modo la necessità di una seria e capace valutazione locale del pericolo (singolo pendio) che può essere anche sensibilmente diverso. Le previsioni meteorologiche sono relative all'orario UTC (per l'Italia +1 in inverno e +2 in estate).

PREALPI LOMBARDE

PREVISIONE METEO

Quota		03/02/2026 h6:00	03/02/2026 h12:00	03/02/2026 h18:00
1000	Venti	04 Nodi da Sud	03 Nodi da S-Est	02 Nodi da S-Est
	Temperature	-02 °C	-03 °C	-02 °C
	Temp.percepita	-5 °C	-5 °C	-2 °C
2000	Venti	09 Nodi da S-Est	05 Nodi da Sud	03 Nodi da Sud
	Temperature	-04 °C	-04 °C	-04 °C
	Temp.percepita	-10 °C	-8 °C	-6 °C
3000	Venti	24 Nodi da Sud	13 Nodi da S-Ovest	06 Nodi da S-Ovest
	Temperature	-07 °C	-09 °C	-10 °C
	Temp.percepita	-17 °C	-17 °C	-16 °C
Zero termico		1300-1500 m.	1300-1500 m.	1300-1500 m.
Fenomeno			—	—
Stato del cielo				

LEGENDA FENOMENI

— Assenza Fenomeni · Nebbia · Foschia · Pioggia debole · Pioggia moderata · Pioggia forte · Temporali

Nevicata debole · Nevicata moderata · Nevicata forte

STATO DEL CIELO

Sereno · Poco nuvoloso · Nuvoloso · Molto nuvoloso · Coperto

Parametri meteonivometrici registrati presso i campi di rilevamento il 02/02/2026.

Località	Comune	Quota (m.s.l.m.)	Altezza neve (cm)	Neve caduta nelle 24 ore (cm)	Temp. Min (°C)	Temp. Max (°C)	Condizioni del tempo
PIANI DI BOBBIO	Barzio (LC)	1724	50	0	-7	+3	Assenza di precipitazioni
BASSINALE	Artogne (BS)	1782	57	0	N.P.	N.P.	Assenza di precipitazioni
PASSO MANIVA	Collio (BS)	1751	25	0	-8	+4	Assenza di precipitazioni
PIAN DELLE BETULLE	Margno (LC)	1445	30	0	-6	+6	Assenza di precipitazioni

(*) Rilievi fuori campo

L'INFORMAZIONE E' PREVENZIONE - LEGGI L'ATTUALE GRADO DI PERICOLO VALANGHE!

IL CAPO DEL CENTRO NAZIONALE METEOMONT
(Ten. Col. RFI Emanuela Gini)
FIRMA AUTOGRAFA OMESSA AI SENSI
DELL'ART.3 DEL D.LGS N.39/1993