ALPI LEPONTINE

Bollettino Valanghe N. 340/2026 del 02/02/2026 ore 14.00
Validità 48 ore prossima emissione 03/02/2026

A cura del Servizio METEOMONT dell'ARMA dei CARABINIERI
In collaborazione con Servizio Meteorologico dell'Aeronautica militare

SITUAZIONE alle 14:00 del 02/02/2026

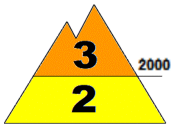

SITUAZIONE TIPO: neve a debole coesione e vento.



SITUAZIONE TIPO: nessuna situazione tipo evidente.

Quota neve (mslm)	Nord	Sud
	700	800

Altezza Neve (cm)	Neve al suolo	Neve Fresca	Quota (mslm)
	121	000	2453
	063	000	1634

VALANGHE OSSERVATE: Valanghe di piccole dimensioni, Valanghe di neve a debole coesione di superficie.

PREVISIONI 03/02/2026

GRADO DI PERICOLO: MARCATO 3

SITUAZIONE TIPO: nessuna situazione tipo evidente.

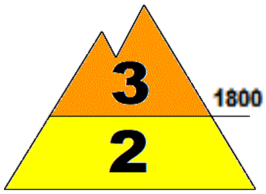

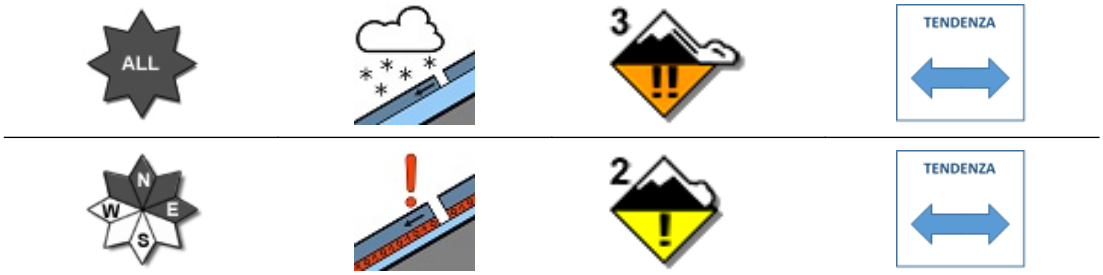

SITUAZIONE TIPO: nessuna situazione tipo evidente.

MANTO NEVOSO: La stabilità del manto nevoso è scarsa su molti punti (aree) per tutte le esposizioni al di sopra di 1800 mslm, possibili valanghe di dimensioni medie.
La stabilità del manto nevoso è scarsa su alcuni punti (aree) per versanti in ombra al di sotto di 1800 mslm, possibili valanghe di dimensioni medie.

AVVERTENZE

In considerazione delle avverse condizioni meteorologiche previste, e della scarsa visibilità, risulterà difficoltosa l'individuazione dell'itinerario e della valutazione del singolo pendio.

SCALA EUROPEA DEL GRADO DI PERICOLO VALANGHE

LEGENDA PROBLEMA

Bollettino realizzato su scala sinottica-regionale (standard EAWS). La sua valutazione non può escludere in alcun modo la necessità di una seria e capace valutazione locale del pericolo (singolo pendio) che può essere anche sensibilmente diverso. Le previsioni meteorologiche sono relative all'orario UTC (per l'Italia +1 in inverno e +2 in estate).

MINISTERO DELLA DIFESA

meteomont
Servizio Nazionale di previsione neve e valanghe

EAWS EUROPEAN AVALANCHE WARNING SERVICES

CARABINIERI

ALPI LEPONTINE

PREVISIONE METEO

Quota		03/02/2026 h6:00	03/02/2026 h12:00	03/02/2026 h18:00
1000	Venti	02 Nodi da S-Ovest	01 Nodi da S-Est	01 Nodi da S-Est
	Temperature	-05 °C	-04 °C	-04 °C
	Temp.percepita	-5 °C	-4 °C	-4 °C
2000	Venti	05 Nodi da S-Ovest	02 Nodi da S-Est	02 Nodi da S-Est
	Temperature	-06 °C	-06 °C	-05 °C
	Temp.percepita	-10 °C	-6 °C	-5 °C
3000	Venti	17 Nodi da Sud	06 Nodi da Sud	07 Nodi da Sud
	Temperature	-12 °C	-12 °C	-11 °C
	Temp.percepita	-22 °C	-18 °C	-17 °C
Zero termico		0900-1100 m.	1100-1300 m.	1000-1200 m.
Fenomeno				—
Stato del cielo				

LEGENDA FENOMENI

— Assenza Fenomeni
Nebbia
Foschia
Pioggia debole
Pioggia moderata
Pioggia forte
Temporali
Nevicata debole
Nevicata moderata
Nevicata forte

STATO DEL CIELO

Sereno
Poco nuvoloso
Nuvoloso
Molto nuvoloso
Coperto

Parametri meteonivometrici registrati presso i campi di rilevamento il 02/02/2026.

Località	Comune	Quota (m.s.l.m.)	Altezza neve (cm)	Neve caduta nelle 24 ore (cm)	Temp. Min (°C)	Temp. Max (°C)	Condizioni del tempo
VALLE LOANA	Malesco (VB)	1245	43	0	-7	+4	Assenza di precipitazioni
RIALE	Formazza (VB)	1736	78	0	N.P.	N.P.	Assenza di precipitazioni
SOPRA LAGO NERO *	Baceno (VB)	2116	130	0	N.P.	N.P.	Assenza di precipitazioni

(*) Rilievi fuori campo

L'INFORMAZIONE E' PREVENZIONE - LEGGI L'ATTUALE GRADO DI PERICOLO VALANGHE!

IL CAPO DEL CENTRO NAZIONALE METEOMONT
(Ten. Col. RFI Emanuela Gini)
FIRMA AUTOGRAFA OMESSA AI SENSI
DELL'ART.3 DEL D.LGS N.39/1993

Bollettino realizzato su scala sinottica-regionale (standard EAWS). La sua valutazione non può escludere in alcun modo la necessità di una seria e capace valutazione locale del pericolo (singolo pendio) che può essere anche sensibilmente diverso. Le previsioni meteorologiche sono relative all'orario UTC (per l'Italia +1 in inverno e +2 in estate).