## ALPI PENNINE

Bollettino Valanghe N. 334/2026 del 02/02/2026 ore 14.00
Validità 48 ore prossima emissione 03/02/2026

**A cura del Servizio METEOMONT dell'ARMA dei CARABINIERI**
**In collaborazione con Servizio Meteorologico dell'Aeronautica militare**

## SITUAZIONE alle 14:00 del 02/02/2026

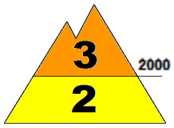


**SITUAZIONE TIPO: neve a debole coesione e vento.**




**SITUAZIONE TIPO: nessuna situazione tipo evidente.**

| Quota neve (mslm) | Nord | Sud |
|---|---|---|
| | 800 | 900 |

| Altezza Neve (cm) | Neve al suolo | Neve Fresca | Quota (mslm) |
|---|---|---|---|
| | 065 | 000 | 2820 |
| | 050 | 000 | 1360 |

**VALANGHE OSSERVATE: Valanghe di piccole dimensioni, Valanghe a lastroni di superficie.**

## PREVISIONI 03/02/2026

# GRADO DI PERICOLO: MARCATO 3

## SITUAZIONE TIPO: nessuna situazione tipo evidente.

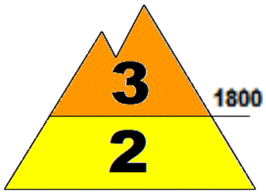


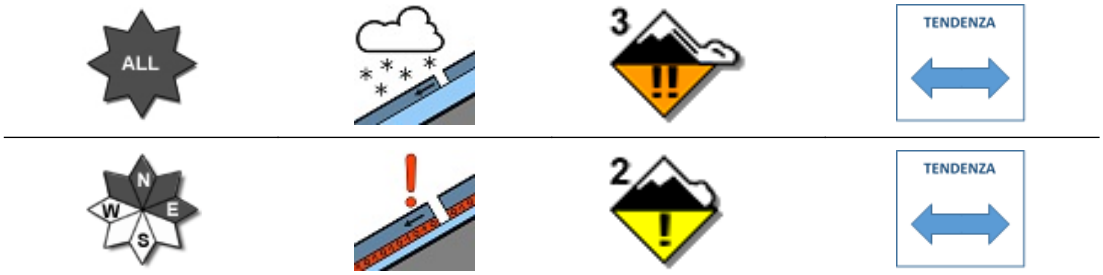


## SITUAZIONE TIPO: nessuna situazione tipo evidente.

**MANTO NEVOSO: La stabilità del manto nevoso è scarsa su molti punti (aree) per tutte le esposizioni al di sopra di 1800 mslm, possibili valanghe di dimensioni medie.**
**La stabilità del manto nevoso è scarsa su alcuni punti (aree) per versanti in ombra al di sotto di 1800 mslm, possibili valanghe di dimensioni medie.**

## AVVERTENZE

In considerazione delle avverse condizioni meteorologiche previste, e della scarsa visibilità, risulterà difficoltosa l'individuazione dell'itinerario e della valutazione del singolo pendio.

## SCALA EUROPEA DEL GRADO DI PERICOLO VALANGHE

## LEGENDA PROBLEMA

**Bollettino realizzato su scala sinottica-regionale (standard EAWS). La sua valutazione non può escludere in alcun modo la necessità di una seria e capace valutazione locale del pericolo (singolo pendio) che può essere anche sensibilmente diverso. Le previsioni meteorologiche sono relative all'orario UTC (per l'Italia +1 in inverno e +2 in estate).**

MINISTERO DELLA DIFESA

meteomont
Servizio Nazionale di previsione neve e valanghe

EAWS EUROPEAN AVALANCHE WARNING SERVICES

CARABINIERI

# ALPI PENNINE

## PREVISIONE METEO

| Quota | | 03/02/2026 h6:00 | 03/02/2026 h12:00 | 03/02/2026 h18:00 |
|---|---|---|---|---|
| 1000 | Venti | 02 Nodi da N-Est | 02 Nodi da N-Est | 02 Nodi da N-Est |
| | Temperature | -04 °C | -03 °C | -03 °C |
| | Temp.percepita | -4 °C | -3 °C | -3 °C |
| 2000 | Venti | 04 Nodi da N-Est | 03 Nodi da N-Est | 03 Nodi da N-Est |
| | Temperature | -06 °C | -06 °C | -06 °C |
| | Temp.percepita | -10 °C | -9 °C | -9 °C |
| 3000 | Venti | 07 Nodi da Sud | 13 Nodi da S-Ovest | 06 Nodi da Sud |
| | Temperature | -10 °C | -09 °C | -11 °C |
| | Temp.percepita | -16 °C | -17 °C | -17 °C |
| Zero termico | | 0800-1000 m. | 1000-1200 m. | 1000-1200 m. |
| Fenomeno | | | — | — |
| Stato del cielo | | | | |

## LEGENDA FENOMENI

Assenza Fenomeni — Nebbia — Foschia — Pioggia debole — Pioggia moderata — Pioggia forte — Temporali

Nevicata debole — Nevicata moderata — Nevicata forte

## STATO DEL CIELO

Sereno — Poco nuvoloso — Nuvoloso — Molto nuvoloso — Coperto

## Parametri meteonivometrici registrati presso i campi di rilevamento il 02/02/2026.

| Località | Comune | Quota (m.s.l.m.) | Altezza neve (cm) | Neve caduta nelle 24 ore (cm) | Temp. Min (°C) | Temp. Max (°C) | Condizioni del tempo |
|---|---|---|---|---|---|---|---|
| ALPE LUSENTINO | Domodossola (VB) | 1184 | 25 | 0 | -1 | +6 | Assenza di precipitazioni |
| OPACO DI PECETTO | Macugnaga (VB) | 1330 | 59 | N.P. | N.P. | N.P. | Assenza di precipitazioni |
| PIANALUNGA | Alagna Valsesia (VC) | 2025 | 70 | 0 | -12 | -7 | Assenza di precipitazioni |

**(*) Rilievi fuori campo**

**L'INFORMAZIONE E' PREVENZIONE - LEGGI L'ATTUALE GRADO DI PERICOLO VALANGHE!**

**IL CAPO DEL CENTRO NAZIONALE METEOMONT**
**(Ten. Col. RFI Emanuela Gini)**
**FIRMA AUTOGRAFA OMESSA AI SENSI**
**DELL'ART.3 DEL D.LGS N.39/1993**

**Bollettino realizzato su scala sinottica-regionale (standard EAWS). La sua valutazione non può escludere in alcun modo la necessità di una seria e capace valutazione locale del pericolo (singolo pendio) che può essere anche sensibilmente diverso. Le previsioni meteorologiche sono relative all'orario UTC (per l'Italia +1 in inverno e +2 in estate).**