MINISTERO DELLA DIFESA

meteomont
Servizio Nazionale di previsione neve e valanghe

EAWS EUROPEAN AVALANCHE WARNING SERVICES

CARABINIERI

ALPI GRAIE

Bollettino Valanghe N. 332/2026 del 01/02/2026 ore 14.00
Validità 48 ore prossima emissione 02/02/2026

A cura del Servizio METEOMONT dell'ARMA dei CARABINIERI
In collaborazione con Servizio Meteorologico dell'Aeronautica militare

SITUAZIONE alle 14:00 del 01/02/2026

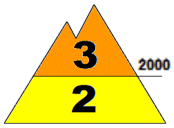

SITUAZIONE TIPO: neve a debole coesione e vento.



SITUAZIONE TIPO: nessuna situazione tipo evidente.

Quota neve (mslm)	Nord	Sud
	800	1000

Altezza Neve (cm)	Neve al suolo	Neve Fresca	Quota (mslm)
	090	000	2650
	067	000	1581

VALANGHE OSSERVATE: Nessuna valanga.

PREVISIONI 02/02/2026

GRADO DI PERICOLO: MARCATO 3

SITUAZIONE TIPO: neve a debole coesione e vento.

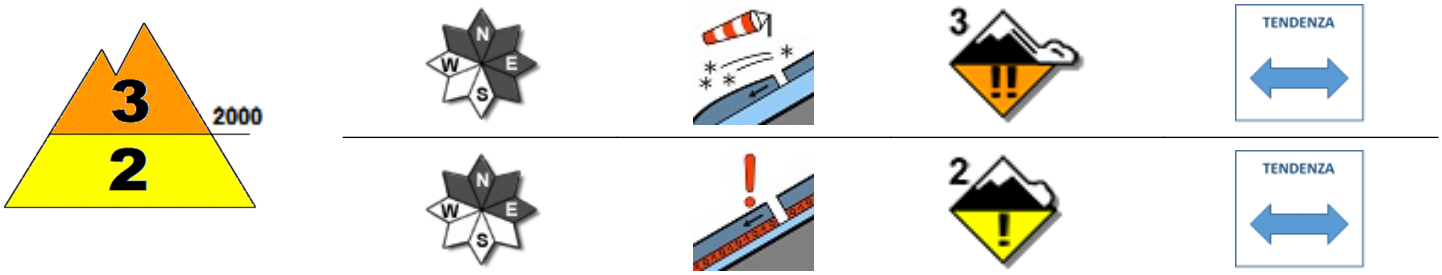

SITUAZIONE TIPO: nessuna situazione tipo evidente.

MANTO NEVOSO: La stabilità del manto nevoso è scarsa su alcuni punti (aree) per versanti da nord ovest a sud est compresi al di sopra di 2000 mslm, possibili valanghe di dimensioni grandi.
La stabilità del manto nevoso è scarsa su alcuni punti (aree) per versanti in ombra al di sotto di 2000 mslm, possibili valanghe di dimensioni medie.

AVVERTENZE

Viste le condizioni del manto nevoso, le attività al di fuori delle piste battute e segnalate richiedono buone capacità di valutazione del pericolo locale.

SCALA EUROPEA DEL GRADO DI PERICOLO VALANGHE

LEGENDA PROBLEMA

Bollettino realizzato su scala sinottica-regionale (standard EAWS). La sua valutazione non può escludere in alcun modo la necessità di una seria e capace valutazione locale del pericolo (singolo pendio) che può essere anche sensibilmente diverso. Le previsioni meteorologiche sono relative all'orario UTC (per l'Italia +1 in inverno e +2 in estate).

MINISTERO DELLA DIFESA

meteomont
Servizio Nazionale di previsione neve e valanghe

EAWS EUROPEAN AVALANCHE WARNING SERVICES

CARABINIERI

ALPI GRAIE

PREVISIONE METEO

Quota		02/02/2026 h6:00	02/02/2026 h12:00	02/02/2026 h18:00
1000	Venti	01 Nodi da Sud	00 Calma	00 Calma
	Temperature	-08 °C	-07 °C	-06 °C
	Temp.percepita	-8 °C	-7 °C	-6 °C
2000	Venti	01 Nodi da S-Est	00 Calma	00 Calma
	Temperature	-07 °C	-08 °C	-07 °C
	Temp.percepita	-7 °C	-8 °C	-7 °C
3000	Venti	05 Nodi da Ovest	03 Nodi da S-Ovest	07 Nodi da S-Ovest
	Temperature	-08 °C	-05 °C	-07 °C
	Temp.percepita	-13 °C	-8 °C	-13 °C
Zero termico		0400-0600 m.	0800-1000 m.	0900-1100 m.
Fenomeno		—	—	
Stato del cielo				

LEGENDA FENOMENI

Assenza Fenomeni · Nebbia · Foschia · Pioggia debole · Pioggia moderata · Pioggia forte · Temporali · Nevicata debole · Nevicata moderata · Nevicata forte

STATO DEL CIELO

Sereno · Poco nuvoloso · Nuvoloso · Molto nuvoloso · Coperto

Parametri meteonivometrici registrati presso i campi di rilevamento il 01/02/2026.

Località	Comune	Quota (m.s.l.m.)	Altezza neve (cm)	Neve caduta nelle 24 ore (cm)	Temp. Min (°C)	Temp. Max (°C)	Condizioni del tempo
CORNETTI	Balme (TO)	1410	82	0	N.P.	N.P.	Assenza di precipitazioni

(*) Rilievi fuori campo

L'INFORMAZIONE E' PREVENZIONE - LEGGI L'ATTUALE GRADO DI PERICOLO VALANGHE!

IL CAPO DEL CENTRO NAZIONALE METEOMONT
(Ten. Col. RFI Emanuela Gini)
FIRMA AUTOGRAFA OMESSA AI SENSI
DELL'ART.3 DEL D.LGS N.39/1993