MINISTERO DELLA DIFESA

meteomont
Servizio Nazionale di previsione neve e valanghe

EAWS EUROPEAN AVALANCHE WARNING SERVICES

CARABINIERI

AERONAUTICA MILITARE SERVIZIO METEOROLOGICO

# ALPI COZIE NORD

Bollettino Valanghe N. 332/2026 del 01/02/2026 ore 14.00
Validità 48 ore prossima emissione 02/02/2026

**A cura del Servizio METEOMONT dell'ARMA dei CARABINIERI**
**In collaborazione con Servizio Meteorologico dell'Aeronautica militare**

## SITUAZIONE alle 14:00 del 01/02/2026

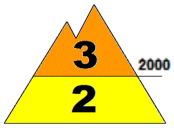


**SITUAZIONE TIPO: neve a debole coesione e vento.**




**SITUAZIONE TIPO: nessuna situazione tipo evidente.**

| Quota neve (mslm) | Nord | Sud |
|---|---|---|
| | 1000 | 1200 |

| Altezza Neve (cm) | Neve al suolo | Neve Fresca | Quota (mslm) |
|---|---|---|---|
| | 122 | 000 | 2280 |
| | 077 | 000 | 1840 |

**VALANGHE OSSERVATE: Nessuna valanga.**

## PREVISIONI 02/02/2026

# GRADO DI PERICOLO: MARCATO 3

## SITUAZIONE TIPO: neve a debole coesione e vento.

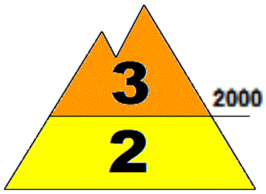


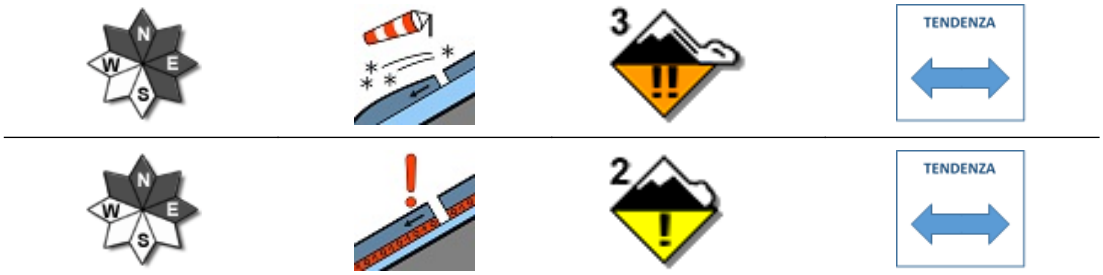


## SITUAZIONE TIPO: nessuna situazione tipo evidente.

**MANTO NEVOSO: La stabilità del manto nevoso è scarsa su molti punti (aree) per versanti da nord ovest a sud est compresi al di sopra di 2000 mslm, possibili valanghe di dimensioni medie.**
**La stabilità del manto nevoso è scarsa su alcuni punti (aree) per versanti in ombra al di sotto di 2000 mslm, possibili valanghe di dimensioni medie.**

## AVVERTENZE

Viste le condizioni del manto nevoso, le attività al di fuori delle piste battute e segnalate richiedono buone capacità di valutazione del pericolo locale.

## SCALA EUROPEA DEL GRADO DI PERICOLO VALANGHE

## LEGENDA PROBLEMA

**Bollettino realizzato su scala sinottica-regionale (standard EAWS). La sua valutazione non può escludere in alcun modo la necessità di una seria e capace valutazione locale del pericolo (singolo pendio) che può essere anche sensibilmente diverso. Le previsioni meteorologiche sono relative all'orario UTC (per l'Italia +1 in inverno e +2 in estate).**

MINISTERO DELLA DIFESA

meteomont
Servizio Nazionale di previsione neve e valanghe

EAWS EUROPEAN AVALANCHE WARNING SERVICES

CARABINIERI

# ALPI COZIE NORD

## PREVISIONE METEO

| Quota | | 02/02/2026 h6:00 | 02/02/2026 h12:00 | 02/02/2026 h18:00 |
|---|---|---|---|---|
| 1000 | Venti | 01 Nodi da Sud | 01 Nodi da Est | 00 Calma |
| | Temperature | -05 °C | -04 °C | -05 °C |
| | Temp.percepita | -5 °C | -4 °C | -5 °C |
| 2000 | Venti | 01 Nodi da Sud | 01 Nodi da S-Est | 02 Nodi da S-Est |
| | Temperature | -06 °C | -07 °C | -07 °C |
| | Temp.percepita | -6 °C | -7 °C | -7 °C |
| 3000 | Venti | 07 nodi da Ovest | 07 Nodi da Ovest | 08 Nodi da S-Ovest |
| | Temperature | -08 °C | -05 °C | -06 °C |
| | Temp.percepita | -14 °C | -10 °C | -12 °C |
| Zero termico | | 0300-0500 m. | 1000-1200 m. | 0800-1000 m. |
| Fenomeno | | — | — | |
| Stato del cielo | | | | |

## LEGENDA FENOMENI

Assenza Fenomeni — Nebbia — Foschia — Pioggia debole — Pioggia moderata — Pioggia forte — Temporali

Nevicata debole — Nevicata moderata — Nevicata forte

## STATO DEL CIELO

Sereno — Poco nuvoloso — Nuvoloso — Molto nuvoloso — Coperto

## Parametri meteonivometrici registrati presso i campi di rilevamento il 01/02/2026.

| Località | Comune | Quota (m.s.l.m.) | Altezza neve (cm) | Neve caduta nelle 24 ore (cm) | Temp. Min (°C) | Temp. Max (°C) | Condizioni del tempo |
|---|---|---|---|---|---|---|---|
| PRAGELATO | Pragelato (TO) | 1550 | 72 | 0 | -9 | +4 | Assenza di precipitazioni |

**(*) Rilievi fuori campo**

**L'INFORMAZIONE E' PREVENZIONE - LEGGI L'ATTUALE GRADO DI PERICOLO VALANGHE!**

**IL CAPO DEL CENTRO NAZIONALE METEOMONT**
**(Ten. Col. RFI Emanuela Gini)**
**FIRMA AUTOGRAFA OMESSA AI SENSI**
**DELL'ART.3 DEL D.LGS N.39/1993**