MINISTERO DELLA DIFESA

meteomont Servizio Nazionale di previsione neve e valanghe

EAWS EUROPEAN AVALANCHE WARNING SERVICES

CARABINIERI

AERONAUTICA MILITARE SERVIZIO METEOROLOGICO

# ALPI MARITTIME

Bollettino Valanghe N. 332/2026 del 01/02/2026 ore 14.00
Validità 48 ore prossima emissione 02/02/2026

**A cura del Servizio METEOMONT dell'ARMA dei CARABINIERI**
**In collaborazione con Servizio Meteorologico dell'Aeronautica militare**

## SITUAZIONE alle 14:00 del 01/02/2026

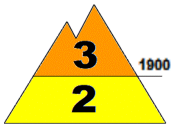


**SITUAZIONE TIPO: neve a debole coesione e vento.**




**SITUAZIONE TIPO: neve da slittamento.**

| Quota neve (mslm) | Nord | Sud |
|---|---|---|
| | 600 | 800 |

| Altezza Neve (cm) | Neve al suolo | Neve Fresca | Quota (mslm) |
|---|---|---|---|
| | 151 | 000 | 2020 |
| | 105 | 000 | 1680 |

**VALANGHE OSSERVATE: Nessuna valanga.**

## PREVISIONI 02/02/2026

# GRADO DI PERICOLO: MARCATO 3

## SITUAZIONE TIPO: neve a debole coesione e vento.

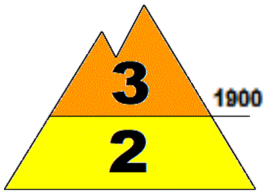


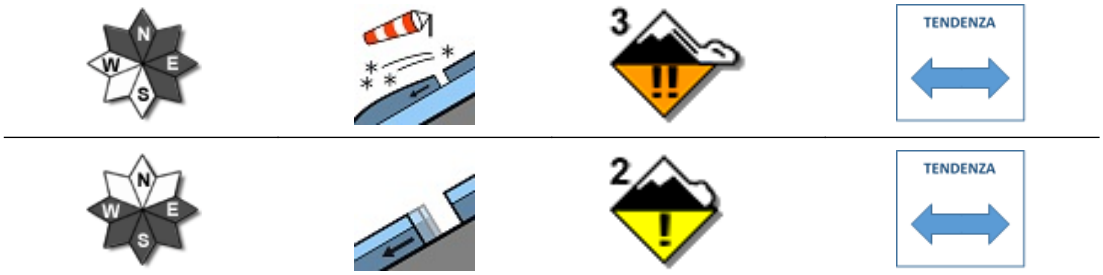


## SITUAZIONE TIPO: neve da slittamento.

**MANTO NEVOSO: La stabilità del manto nevoso è molto scarsa su alcuni punti (aree) per versanti da nord ovest a sud est compresi al di sopra di 1900 mslm, possibili valanghe di dimensioni grandi.**
**La stabilità del manto nevoso è scarsa su alcuni punti (aree) per versanti da est a ovest al di sotto di 1900 mslm, possibili valanghe di dimensioni medie.**

## AVVERTENZE

Viste le condizioni del manto nevoso, le attività al di fuori delle piste battute e segnalate richiedono ottime capacità di valutazione del pericolo locale.

## SCALA EUROPEA DEL GRADO DI PERICOLO VALANGHE

## LEGENDA PROBLEMA

**Bollettino realizzato su scala sinottica-regionale (standard EAWS). La sua valutazione non può escludere in alcun modo la necessità di una seria e capace valutazione locale del pericolo (singolo pendio) che può essere anche sensibilmente diverso. Le previsioni meteorologiche sono relative all'orario UTC (per l'Italia +1 in inverno e +2 in estate).**

MINISTERO DELLA DIFESA

meteomont
Servizio Nazionale di previsione neve e valanghe

EAWS EUROPEAN AVALANCHE WARNING SERVICES

CARABINIERI

# ALPI MARITTIME

## PREVISIONE METEO

| Quota | | 02/02/2026 h6:00 | 02/02/2026 h12:00 | 02/02/2026 h18:00 |
|---|---|---|---|---|
| 1000 | Venti | 01 Nodi da S-Ovest | 01 Nodi da S-Ovest | 01 Nodi da S-Ovest |
| | Temperature | -02 °C | -03 °C | -02 °C |
| | Temp.percepita | -2 °C | -3 °C | -2 °C |
| 2000 | Venti | 02 Nodi da S-Ovest | 03 Nodi da Sud | 04 Nodi da Sud |
| | Temperature | -04 °C | -04 °C | -04 °C |
| | Temp.percepita | -4 °C | -6 °C | -7 °C |
| 3000 | Venti | 11 Nodi da Ovest | 08 Nodi da S-Ovest | 13 Nodi da Sud |
| | Temperature | -07 °C | -06 °C | -06 °C |
| | Temp.percepita | -14 °C | -12 °C | -13 °C |
| Zero termico | | 0300-0500 m. | 0700-0900 m. | 0800-1000 m. |
| Fenomeno | | — | — | |
| Stato del cielo | | | | |

## LEGENDA FENOMENI

— Assenza Fenomeni
Nebbia
Foschia
Pioggia debole
Pioggia moderata
Pioggia forte
Temporali
Nevicata debole
Nevicata moderata
Nevicata forte

## STATO DEL CIELO

Sereno
Poco nuvoloso
Nuvoloso
Molto nuvoloso
Coperto

## Parametri meteonivometrici registrati presso i campi di rilevamento il 01/02/2026.

| Località | Comune | Quota (m.s.l.m.) | Altezza neve (cm) | Neve caduta nelle 24 ore (cm) | Temp. Min (°C) | Temp. Max (°C) | Condizioni del tempo |
|---|---|---|---|---|---|---|---|
| STREPEIS | Vinadio (CN) | 1320 | 135 | 0 | -7 | +3 | Assenza di precipitazioni |

(*) Rilievi fuori campo

**L'INFORMAZIONE E' PREVENZIONE - LEGGI L'ATTUALE GRADO DI PERICOLO VALANGHE!**

IL CAPO DEL CENTRO NAZIONALE METEOMONT
(Ten. Col. RFI Emanuela Gini)
FIRMA AUTOGRAFA OMESSA AI SENSI
DELL'ART.3 DEL D.LGS N.39/1993

Bollettino realizzato su scala sinottica-regionale (standard EAWS). La sua valutazione non può escludere in alcun modo la necessità di una seria e capace valutazione locale del pericolo (singolo pendio) che può essere anche sensibilmente diverso. Le previsioni meteorologiche sono relative all'orario UTC (per l'Italia +1 in inverno e +2 in estate).