MINISTERO DELLA DIFESA

meteomont
Servizio Nazionale di previsione neve e valanghe

EAWS EUROPEAN AVALANCHE WARNING SERVICES

CARABINIERI

ALPI LIGURI SUD

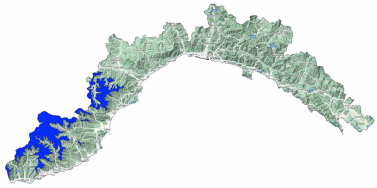

Bollettino Valanghe N. 284/2026 del 01/02/2026 ore 14.00
Validità 48 ore prossima emissione 02/02/2026

A cura del Servizio METEOMONT dell'ARMA dei CARABINIERI
In collaborazione con Servizio Meteorologico dell'Aeronautica militare

SITUAZIONE alle 14:00 del 01/02/2026

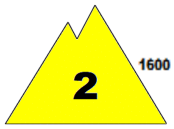

SITUAZIONE TIPO: neve a debole coesione e vento.



SITUAZIONE TIPO: situazione primaverile.

Quota neve (mslm)	Nord	Sud
	500 - 1500	1200 - 1600

Altezza Neve (cm)	Neve al suolo	Neve Fresca	Quota (mslm)
	112	0	1500
	81	0	1400

VALANGHE OSSERVATE: Nessuna valanga.

PREVISIONI 02/02/2026

GRADO DI PERICOLO: MODERATO 2

SITUAZIONE TIPO: neve a debole coesione e vento.



SITUAZIONE TIPO: situazione primaverile.

MANTO NEVOSO: La stabilità del manto nevoso è scarsa su alcuni punti (aree) per tutte le esposizioni al di sopra di 1600 mslm, possibili valanghe di dimensioni medie.
La stabilità del manto nevoso è scarsa su pochi punti (aree) per versanti da est a ovest al di sotto di 1600 mslm, possibili valanghe di dimensioni medie.

AVVERTENZE

In considerazione dei recenti apporti di neve fresca, è richiesta un'ottima valutazione locale della stabilità ed individuazione dell'itinerario.

SCALA EUROPEA DEL GRADO DI PERICOLO VALANGHE

LEGENDA PROBLEMA

Bollettino realizzato su scala sinottica-regionale (standard EAWS). La sua valutazione non può escludere in alcun modo la necessità di una seria e capace valutazione locale del pericolo (singolo pendio) che può essere anche sensibilmente diverso. Le previsioni meteorologiche sono relative all'orario UTC (per l'Italia +1 in inverno e +2 in estate).

Bollettino sottoposto a processi di: Acquisizione e controllo del C-Sifa e della rete di Osservatori e Esperti - Validazione del Previsore di turno - Certificazione della Sezione Meteomont.

MINISTERO DELLA DIFESA

meteomont
Servizio Nazionale di previsione neve e valanghe

EAWS EUROPEAN AVALANCHE WARNING SERVICES

CARABINIERI

ALPI LIGURI SUD

PREVISIONE METEO

Quota		02/02/2026 h6:00	02/02/2026 h12:00	02/02/2026 h18:00
1000	Venti	01 nodi da Ovest	02 Nodi da Sud	02 Nodi da Sud
	Temperature	-03 °C	-02 °C	-01 °C
	Temp.percepita	-3 °C	-2 °C	-1 °C
2000	Venti	03 Nodi da S-Ovest	05 Nodi da S-Ovest	06 Nodi da Sud
	Temperature	-04 °C	-04 °C	-02 °C
	Temp.percepita	-6 °C	-8 °C	-6 °C
3000	Venti	09 Nodi da Ovest	09 Nodi da Ovest	13 Nodi da Sud
	Temperature	-07 °C	-05 °C	-07 °C
	Temp.percepita	-13 °C	-11 °C	-15 °C
Zero termico		1000-1200 m.	1300-1500 m.	1400-1600 m.
Fenomeno		—	—	
Stato del cielo				

LEGENDA FENOMENI

Assenza Fenomeni — Nebbia — Foschia — Pioggia debole — Pioggia moderata — Pioggia forte — Temporali

Nevicata debole — Nevicata moderata — Nevicata forte

STATO DEL CIELO

Sereno — Poco nuvoloso — Nuvoloso — Molto nuvoloso — Coperto

Parametri meteonivometrici registrati presso i campi di rilevamento il 01/02/2026.

Località	Comune	Quota (m.s.l.m.)	Altezza neve (cm)	Neve caduta nelle 24 ore (cm)	Temp. Min (°C)	Temp. Max (°C)	Condizioni del tempo
PIAN DI FONTANA-MONESI	Triora (IM)	1525	112	0	-4	+4	Assenza di precipitazioni

(*) Rilievi fuori campo

L'INFORMAZIONE E' PREVENZIONE - LEGGI L'ATTUALE GRADO DI PERICOLO VALANGHE!

IL CAPO DEL CENTRO NAZIONALE METEOMONT
(Ten. Col. RFI Emanuela Gini)
FIRMA AUTOGRAFA OMESSA AI SENSI
DELL'ART.3 DEL D.LGS N.39/1993

Bollettino realizzato su scala sinottica-regionale (standard EAWS). La sua valutazione non può escludere in alcun modo la necessità di una seria e capace valutazione locale del pericolo (singolo pendio) che può essere anche sensibilmente diverso. Le previsioni meteorologiche sono relative all'orario UTC (per l'Italia +1 in inverno e +2 in estate).