MINISTERO DELLA DIFESA

meteomont
Servizio Nazionale di previsione neve e valanghe

EAWS EUROPEAN AVALANCHE WARNING SERVICES

CARABINIERI

ALPI LIGURI SUD

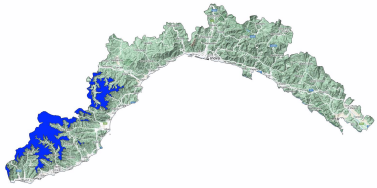

Bollettino Valanghe N. 285/2026 del 02/02/2026 ore 14.00
Validità 48 ore prossima emissione 03/02/2026

A cura del Servizio METEOMONT dell'ARMA dei CARABINIERI
In collaborazione con Servizio Meteorologico dell'Aeronautica militare

SITUAZIONE alle 14:00 del 02/02/2026

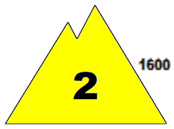

SITUAZIONE TIPO: neve a debole coesione e vento.



SITUAZIONE TIPO: situazione primaverile.

Quota neve (mslm)	Nord	Sud
	600 - 1600	1300 - 1700

Altezza Neve (cm)	Neve al suolo	Neve Fresca	Quota (mslm)
	112	0	1500
	81	0	1400

VALANGHE OSSERVATE: Nessuna valanga.

PREVISIONI 03/02/2026

GRADO DI PERICOLO: MARCATO 3

SITUAZIONE TIPO: neve a debole coesione e vento.

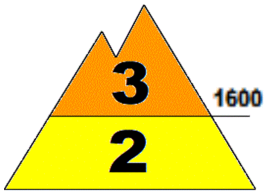

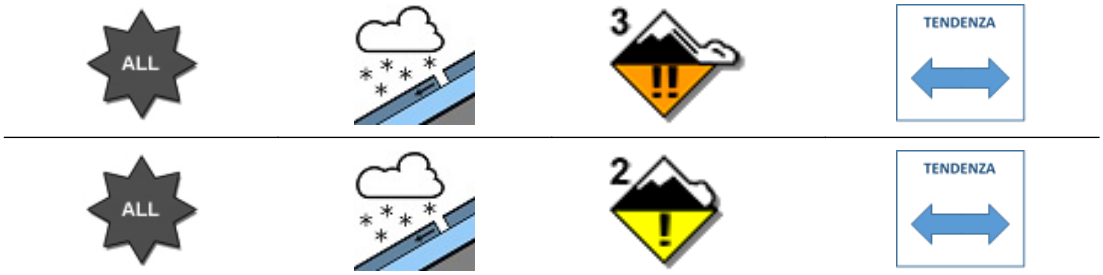

SITUAZIONE TIPO: neve a debole coesione e vento.

MANTO NEVOSO: La stabilità del manto nevoso è scarsa su molti punti (aree) per tutte le esposizioni al di sopra di 1600 mslm, possibili valanghe di dimensioni medie.
La stabilità del manto nevoso è scarsa su alcuni punti (aree) per tutte le esposizioni al di sotto di 1600 mslm, possibili valanghe di dimensioni medie.

AVVERTENZE

In considerazione delle avverse condizioni meteorologiche previste, le attività al di fuori delle piste battute e segnalate sono limitate. Se effettuate, richiedono ottime capacità di valutazione del pericolo locale.

SCALA EUROPEA DEL GRADO DI PERICOLO VALANGHE

LEGENDA PROBLEMA

Bollettino realizzato su scala sinottica-regionale (standard EAWS). La sua valutazione non può escludere in alcun modo la necessità di una seria e capace valutazione locale del pericolo (singolo pendio) che può essere anche sensibilmente diverso. Le previsioni meteorologiche sono relative all'orario UTC (per l'Italia +1 in inverno e +2 in estate).

MINISTERO DELLA DIFESA

meteomont
Servizio Nazionale di previsione neve e valanghe

EAWS EUROPEAN AVALANCHE WARNING SERVICES

CARABINIERI

ALPI LIGURI SUD

PREVISIONE METEO

Quota		03/02/2026 h6:00	03/02/2026 h12:00	03/02/2026 h18:00
1000	Venti	03 Nodi da S-Ovest	03 Nodi da Sud	02 Nodi da S-Ovest
	Temperature	+00 °C	+00 °C	-01 °C
	Temp.percepita	-2 °C	-2 °C	-1 °C
2000	Venti	09 Nodi da S-Ovest	08 Nodi da S-Ovest	05 Nodi da S-Ovest
	Temperature	-02 °C	-02 °C	-03 °C
	Temp.percepita	-7 °C	-7 °C	-7 °C
3000	Venti	18 Nodi da S-Ovest	16 Nodi da S-Ovest	12 Nodi da S-Ovest
	Temperature	-08 °C	-08 °C	-08 °C
	Temp.percepita	-17 °C	-17 °C	-16 °C
Zero termico		1600-1800 m.	1600-1800 m.	1300-1500 m.
Fenomeno			—	—
Stato del cielo				

LEGENDA FENOMENI

Assenza Fenomeni — Nebbia — Foschia — Pioggia debole — Pioggia moderata — Pioggia forte — Temporali

Nevicata debole — Nevicata moderata — Nevicata forte

STATO DEL CIELO

Sereno — Poco nuvoloso — Nuvoloso — Molto nuvoloso — Coperto

Parametri meteonivometrici registrati presso i campi di rilevamento il 02/02/2026.

Località	Comune	Quota (m.s.l.m.)	Altezza neve (cm)	Neve caduta nelle 24 ore (cm)	Temp. Min (°C)	Temp. Max (°C)	Condizioni del tempo
PASSO MELOGNO	Calizzano (SV)	1028	69	0	N.P.	N.P.	Assenza di precipitazioni
PIAN DI FONTANA-MONESI	Triora (IM)	1525	112	0	-3	+3	Assenza di precipitazioni

(*) Rilievi fuori campo

L'INFORMAZIONE E' PREVENZIONE - LEGGI L'ATTUALE GRADO DI PERICOLO VALANGHE!

IL CAPO DEL CENTRO NAZIONALE METEOMONT
(Ten. Col. RFI Emanuela Gini)
FIRMA AUTOGRAFA OMESSA AI SENSI
DELL'ART.3 DEL D.LGS N.39/1993