MINISTERO DELLA DIFESA

meteomont Servizio Nazionale di previsione neve e valanghe

EAWS EUROPEAN AVALANCHE WARNING SERVICES

CARABINIERI

In collaborazione con: MARCHE

APPENNINO UMBRO-MARCHIGIANO SETTENTRIONALE

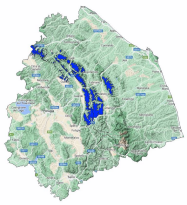

Bollettino Valanghe N. 144/2026 del 02/02/2026 ore 14.00
Validità 48 ore prossima emissione 03/02/2026

A cura del Servizio METEOMONT dell'ARMA dei CARABINIERI
In collaborazione con Servizio Meteorologico dell'Aeronautica militare

SITUAZIONE alle 14:00 del 02/02/2026

SITUAZIONE TIPO: nessuna situazione tipo evidente.

Quota neve (mslm)	Nord	Sud
	1400 - 1500	1500

Altezza Neve (cm)	Neve al suolo	Neve Fresca	Quota (mslm)
	00 -21	002	1450

VALANGHE OSSERVATE: Nessuna valanga.

PREVISIONI 03/02/2026

GRADO DI PERICOLO: DEBOLE 1

SITUAZIONE TIPO: nessuna situazione tipo evidente.



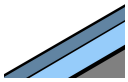

MANTO NEVOSO: La stabilità del manto nevoso è discreta su pochi punti (aree) per isolati pendii, possibili valanghe di dimensioni piccole.

AVVERTENZE

Meteomont ricorda ARTVA, pala e sonda sempre al seguito.

SCALA EUROPEA DEL GRADO DI PERICOLO VALANGHE

LEGENDA PROBLEMA

Bollettino realizzato su scala sinottica-regionale (standard EAWS). La sua valutazione non può escludere in alcun modo la necessità di una seria e capace valutazione locale del pericolo (singolo pendio) che può essere anche sensibilmente diverso. Le previsioni meteorologiche sono relative all'orario UTC (per l'Italia +1 in inverno e +2 in estate).

MINISTERO DELLA DIFESA

meteomont
Servizio Nazionale di previsione neve e valanghe

EAWS EUROPEAN AVALANCHE WARNING SERVICES

CARABINIERI

In collaborazione con: MARCHE

APPENNINO UMBRO-MARCHIGIANO SETTENTRIONALE

PREVISIONE METEO

Quota		03/02/2026 h6:00	03/02/2026 h12:00	03/02/2026 h18:00
1000	Venti	19 Nodi da S-Ovest	20 Nodi da S-Ovest	04 Nodi da S-Ovest
	Temperature	+05 °C	+06 °C	+06 °C
	Temp.percepita	-0 °C	1 °C	4 °C
2000	Venti	22 Nodi da S-Ovest	24 Nodi da S-Ovest	08 Nodi da S-Ovest
	Temperature	+02 °C	+02 °C	+00 °C
	Temp.percepita	-5 °C	-5 °C	-4 °C
3000	Venti	23 Nodi da Ovest	22 Nodi da S-Ovest	16 Nodi da Sud
	Temperature	-04 °C	-02 °C	-05 °C
	Temp.percepita	-13 °C	-10 °C	-13 °C
Zero termico		2300-2500 m.	2500-2700 m.	1900-2100 m.
Fenomeno				
Stato del cielo				

LEGENDA FENOMENI

Assenza Fenomeni · Nebbia · Foschia · Pioggia debole · Pioggia moderata · Pioggia forte · Temporali

Nevicata debole · Nevicata moderata · Nevicata forte

STATO DEL CIELO

Sereno · Poco nuvoloso · Nuvoloso · Molto nuvoloso · Coperto

Parametri meteonivometrici registrati presso i campi di rilevamento il 02/02/2026.

Località	Comune	Quota (m.s.l.m.)	Altezza neve (cm)	Neve caduta nelle 24 ore (cm)	Temp. Min (°C)	Temp. Max (°C)	Condizioni del tempo
MONTE NERONE	Apecchio (PU)	1400	0	0	-6	-2	Assenza di precipitazioni
VALSORDA	Gualdo Tadino (PG)	1005	0	N.P.	-5	0	Assenza di precipitazioni
MONTE ACUTO	Frontone (PU)	1450	21	0	-5	-1	Assenza di precipitazioni

(*) Rilievi fuori campo

L'INFORMAZIONE E' PREVENZIONE - LEGGI L'ATTUALE GRADO DI PERICOLO VALANGHE!

IL CAPO DEL CENTRO NAZIONALE METEOMONT
(Ten. Col. RFI Emanuela Gini)
FIRMA AUTOGRAFA OMESSA AI SENSI
DELL'ART.3 DEL D.LGS N.39/1993

Bollettino realizzato su scala sinottica-regionale (standard EAWS). La sua valutazione non può escludere in alcun modo la necessità di una seria e capace valutazione locale del pericolo (singolo pendio) che può essere anche sensibilmente diverso. Le previsioni meteorologiche sono relative all'orario UTC (per l'Italia +1 in inverno e +2 in estate).