MINISTERO DELLA DIFESA

meteomont Servizio Nazionale di previsione neve e valanghe

EAWS EUROPEAN AVALANCHE WARNING SERVICES

CARABINIERI

In collaborazione con: MARCHE

APPENNINO UMBRO-MARCHIG. MERID. - MONTI SIBILLINI

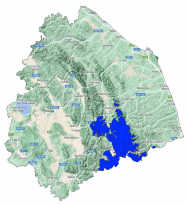

Bollettino Valanghe N. 287/2026 del 02/02/2026 ore 14.00
Validità 48 ore prossima emissione 03/02/2026

A cura del Servizio METEOMONT dell'ARMA dei CARABINIERI
In collaborazione con Servizio Meteorologico dell'Aeronautica militare

SITUAZIONE alle 14:00 del 02/02/2026

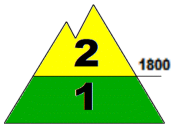

SITUAZIONE TIPO: passaggio da poca a molta neve.



SITUAZIONE TIPO: situazione primaverile.

	Nord	Sud
Quota neve (mslm)	*1200 - 1400*	*1500 - 1600*

	Neve al suolo	Neve Fresca	Quota (mslm)
Altezza Neve (cm)	*80-120*	*001*	*2100*
	20 -35	*001*	*1700*

VALANGHE OSSERVATE: Nessuna valanga.

PREVISIONI 03/02/2026

GRADO DI PERICOLO: MODERATO 2

SITUAZIONE TIPO: passaggio da poca a molta neve.

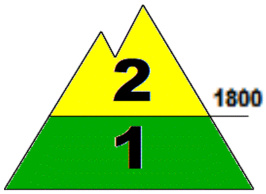

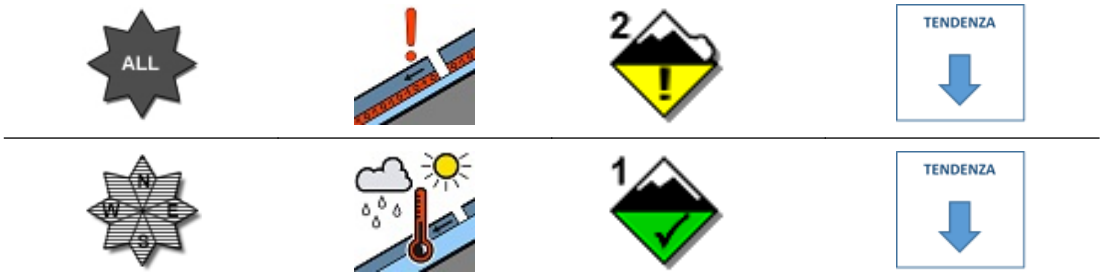

SITUAZIONE TIPO: situazione primaverile.

MANTO NEVOSO: La stabilità del manto nevoso è discreta su alcuni punti (aree) per tutte le esposizioni al di sopra di 1800 mslm, possibili valanghe di dimensioni medie.
La stabilità del manto nevoso è discreta su pochi punti (aree) per isolati pendii al di sotto di 1800 mslm, possibili valanghe di dimensioni piccole.

AVVERTENZE

Meteomont ricorda ARTVA, pala e sonda sempre al seguito.

SCALA EUROPEA DEL GRADO DI PERICOLO VALANGHE

5 - MOLTO FORTE | 4 - FORTE | 3 - MARCATO | 2 - MODERATO | 1 - DEBOLE | NO NEVE | NO INFO

LEGENDA PROBLEMA

NEVE FRESCA | LASTRONI DA VENTO | STRATI DEBOLI PERSISTENTI | NEVE BAGNATA | SLITTAMENTO | CORNICI | NESSUN PROBLEMA VALANGHIVO EVIDENTE | NO_INFO

Bollettino realizzato su scala sinottica-regionale (standard EAWS). La sua valutazione non può escludere in alcun modo la necessità di una seria e capace valutazione locale del pericolo (singolo pendio) che può essere anche sensibilmente diverso. Le previsioni meteorologiche sono relative all'orario UTC (per l'Italia +1 in inverno e +2 in estate).

MINISTERO DELLA DIFESA

meteomont
Servizio Nazionale di previsione neve e valanghe

EAWS EUROPEAN AVALANCHE WARNING SERVICES

CARABINIERI

In collaborazione con: MARCHE

APPENNINO UMBRO-MARCHIG. MERID. - MONTI SIBILLINI

PREVISIONE METEO

Quota		03/02/2026 h6:00	03/02/2026 h12:00	03/02/2026 h18:00
1000	Venti	06 Nodi da S-Ovest	04 Nodi da S-Ovest	03 Nodi da Sud
	Temperature	+04 °C	+05 °C	+04 °C
	Temp.percepita	1 °C	3 °C	3 °C
2000	Venti	19 Nodi da S-Ovest	16 Nodi da S-Ovest	11 Nodi da S-Ovest
	Temperature	+02 °C	+01 °C	+01 °C
	Temp.percepita	-4 °C	-5 °C	-4 °C
3000	Venti	20 Nodi da S-Ovest	22 Nodi da S-Ovest	17 Nodi da S-Ovest
	Temperature	-03 °C	-03 °C	-05 °C
	Temp.percepita	-11 °C	-11 °C	-13 °C
Zero termico		2500-2700 m.	2100-2300 m.	2000-2200 m.
Fenomeno		—	—	
Stato del cielo				

LEGENDA FENOMENI

— Assenza Fenomeni · Nebbia · Foschia · Pioggia debole · Pioggia moderata · Pioggia forte · Temporali

Nevicata debole · Nevicata moderata · Nevicata forte

STATO DEL CIELO

Sereno · Poco nuvoloso · Nuvoloso · Molto nuvoloso · Coperto

Parametri meteonivometrici registrati presso i campi di rilevamento il 02/02/2026.

Località	Comune	Quota (m.s.l.m.)	Altezza neve (cm)	Neve caduta nelle 24 ore (cm)	Temp. Min (°C)	Temp. Max (°C)	Condizioni del tempo
FORCA DI GUALDO	Castelsantangelo sul Nera (MC)	1496	34	0	-5	0	Assenza di precipitazioni
LA VALLETTA	Bolognola (MC)	1352	5	N.P.	-6	+2	Assenza di precipitazioni
COLLE	Montegallo (AP)	1036	0	N.P.	-5	+3	Assenza di precipitazioni
PARCO GUARNIERI	Montemonaco (AP)	980	0	0	-1	+5	Assenza di precipitazioni
RIFUGIO PERUGIA	Norcia (PG)	1500	0	0	N.P.	N.P.	Nebbia con cielo non visibile
FRONTIGNANO *	Ussita (MC)	1696	27	0	-7	+1	Assenza di precipitazioni

(*) Rilievi fuori campo

L'INFORMAZIONE E' PREVENZIONE - LEGGI L'ATTUALE GRADO DI PERICOLO VALANGHE!

IL CAPO DEL CENTRO NAZIONALE METEOMONT
(Ten. Col. RFI Emanuela Gini)
FIRMA AUTOGRAFA OMESSA AI SENSI
DELL'ART.3 DEL D.LGS N.39/1993

Bollettino realizzato su scala sinottica-regionale (standard EAWS). La sua valutazione non può escludere in alcun modo la necessità di una seria e capace valutazione locale del pericolo (singolo pendio) che può essere anche sensibilmente diverso. Le previsioni meteorologiche sono relative all'orario UTC (per l'Italia +1 in inverno e +2 in estate).