MINISTERO DELLA DIFESA

meteomont Servizio Nazionale di previsione neve e valanghe

EAWS EUROPEAN AVALANCHE WARNING SERVICES

CARABINIERI

GRAN SASSO EST - LAGA EST

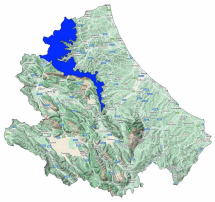

Bollettino Valanghe N. 321/2026 del 01/02/2026 ore 14.00
Validità 48 ore prossima emissione 02/02/2026

A cura del Servizio METEOMONT dell'ARMA dei CARABINIERI
In collaborazione con Servizio Meteorologico dell'Aeronautica militare

SITUAZIONE alle 14:00 del 01/02/2026

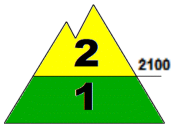

SITUAZIONE TIPO: neve a debole coesione e vento.



SITUAZIONE TIPO: situazione primaverile.

Quota neve (mslm)	Nord	Sud
	1000 - 1400	1000 - 1500

Altezza Neve (cm)	Neve al suolo	Neve Fresca	Quota (mslm)
	034	011	1380
	007	004	1349

VALANGHE OSSERVATE: -.

PREVISIONI 02/02/2026

GRADO DI PERICOLO: MODERATO 2

SITUAZIONE TIPO: passaggio da poca a molta neve.

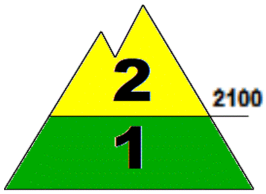

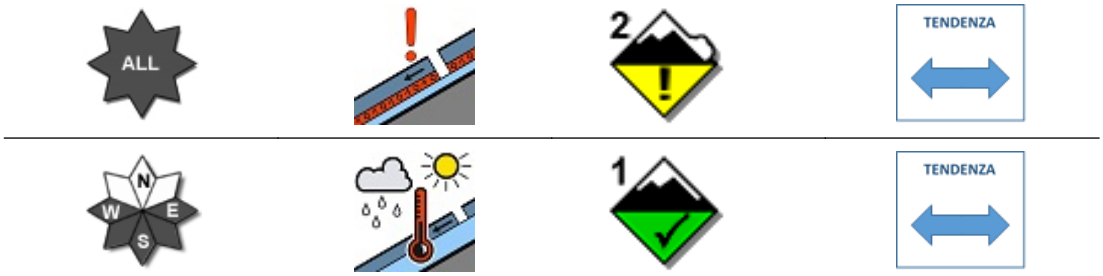

SITUAZIONE TIPO: pioggia su neve.

MANTO NEVOSO: La stabilità del manto nevoso è scarsa su pochi punti (aree) per tutte le esposizioni al di sopra di 2100 mslm, possibili valanghe di dimensioni grandi.
La stabilità del manto nevoso è discreta su pochi punti (aree) per versanti da est a ovest al di sotto di 2100 mslm, possibili valanghe di dimensioni medie.

AVVERTENZE

Attenzione alla presenza di accumuli eolici di difficile individuazione.

SCALA EUROPEA DEL GRADO DI PERICOLO VALANGHE

5 - MOLTO FORTE | 4 - FORTE | 3 - MARCATO | 2 - MODERATO | 1 - DEBOLE | NO NEVE | NO INFO

LEGENDA PROBLEMA

NEVE FRESCA | LASTRONI DA VENTO | STRATI DEBOLI PERSISTENTI | NEVE BAGNATA | SLITTAMENTO | CORNICI | NESSUN PROBLEMA VALANGHIVO EVIDENTE | NO_INFO

Bollettino realizzato su scala sinottica-regionale (standard EAWS). La sua valutazione non può escludere in alcun modo la necessità di una seria e capace valutazione locale del pericolo (singolo pendio) che può essere anche sensibilmente diverso. Le previsioni meteorologiche sono relative all'orario UTC (per l'Italia +1 in inverno e +2 in estate).

MINISTERO DELLA DIFESA

meteomont
Servizio Nazionale di previsione neve e valanghe

EAWS EUROPEAN AVALANCHE WARNING SERVICES

CARABINIERI

GRAN SASSO EST - LAGA EST

PREVISIONE METEO

Quota		02/02/2026 h6:00	02/02/2026 h12:00	02/02/2026 h18:00
1000	Venti	00 Calma	02 Nodi da S-Ovest	02 Nodi da Sud
	Temperature	+00 °C	+01 °C	+00 °C
	Temp.percepita	0 °C	1 °C	0 °C
2000	Venti	06 nodi da N-Ovest	06 Nodi da Ovest	05 Nodi da Ovest
	Temperature	-03 °C	-02 °C	-02 °C
	Temp.percepita	-7 °C	-6 °C	-5 °C
3000	Venti	09 nodi da N-Ovest	10 Nodi da Ovest	09 Nodi da Ovest
	Temperature	-09 °C	-08 °C	-05 °C
	Temp.percepita	-16 °C	-15 °C	-11 °C
Zero termico		0800-1000 m.	1500-1700 m.	1200-1400 m.
Fenomeno		—	—	—
Stato del cielo				

LEGENDA FENOMENI

— Assenza Fenomeni · Nebbia · Foschia · Pioggia debole · Pioggia moderata · Pioggia forte · Temporali

Nevicata debole · Nevicata moderata · Nevicata forte

STATO DEL CIELO

Sereno · Poco nuvoloso · Nuvoloso · Molto nuvoloso · Coperto

Parametri meteonivometrici registrati presso i campi di rilevamento il 01/02/2026.

Località	Comune	Quota (m.s.l.m.)	Altezza neve (cm)	Neve caduta nelle 24 ore (cm)	Temp. Min (°C)	Temp. Max (°C)	Condizioni del tempo
FAVACCHIOLE	Crognaleto (TE)	1016	0	0	0	+5	Assenza di precipitazioni
PIANO SAN PIETRO	Isola del Gran Sasso d'Italia (TE)	950	0	0	N.P.	N.P.	Assenza di precipitazioni
PRATI DI TIVO	Pietracamela (TE)	1380	34	11	-2	+3	Nevicata debole continua
CEPPO	Rocca Santa Maria (TE)	1349	7	4	-1	+1	Nebbia con cielo non visibile
SAN PAOLO	Acquasanta Terme (AP)	960	0	0	+1	+6	Pioggia debole intermittente

(*) Rilievi fuori campo

L'INFORMAZIONE E' PREVENZIONE - LEGGI L'ATTUALE GRADO DI PERICOLO VALANGHE!

IL CAPO DEL CENTRO NAZIONALE METEOMONT
(Ten. Col. RFI Emanuela Gini)
FIRMA AUTOGRAFA OMESSA AI SENSI
DELL'ART.3 DEL D.LGS N.39/1993

Bollettino realizzato su scala sinottica-regionale (standard EAWS). La sua valutazione non può escludere in alcun modo la necessità di una seria e capace valutazione locale del pericolo (singolo pendio) che può essere anche sensibilmente diverso. Le previsioni meteorologiche sono relative all'orario UTC (per l'Italia +1 in inverno e +2 in estate).