MINISTERO DELLA DIFESA

meteomont
Servizio Nazionale di previsione neve e valanghe

EAWS EUROPEAN AVALANCHE WARNING SERVICES

CARABINIERI

GRAN SASSO OVEST

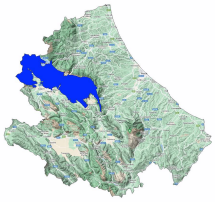

Bollettino Valanghe N. 323/2026 del 02/02/2026 ore 14.00
Validità 48 ore prossima emissione 03/02/2026

A cura del Servizio METEOMONT dell'ARMA dei CARABINIERI
In collaborazione con Servizio Meteorologico dell'Aeronautica militare

SITUAZIONE alle 14:00 del 02/02/2026

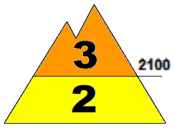

SITUAZIONE TIPO: passaggio da poca a molta neve.



SITUAZIONE TIPO: situazione primaverile.

Quota neve (mslm)	Nord	Sud
	1500	1600 - 1700

Altezza Neve (cm)	Neve al suolo	Neve Fresca	Quota (mslm)
	210	000	2411
	096	000	2135

VALANGHE OSSERVATE: Nessuna valanga.

PREVISIONI 03/02/2026

GRADO DI PERICOLO: MARCATO 3

SITUAZIONE TIPO: passaggio da poca a molta neve.

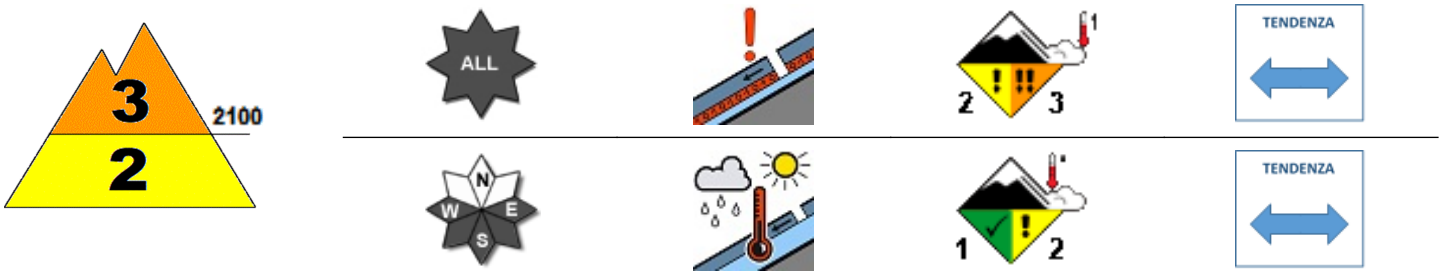

SITUAZIONE TIPO: situazione primaverile.

MANTO NEVOSO: La stabilità del manto nevoso è scarsa su alcuni punti (aree) per tutte le esposizioni al di sopra di 2100 mslm, possibili valanghe di dimensioni grandi.
La stabilità del manto nevoso è discreta su alcuni punti (aree) per versanti da est a ovest al di sotto di 2100 mslm, possibili valanghe di dimensioni medie.

AVVERTENZE

A seguito dell'attività eolica registrata sono da evitare le zone di accumulo, conche, canaloni, cambi di pendenza e pendii sotto vento in genere.

SCALA EUROPEA DEL GRADO DI PERICOLO VALANGHE

LEGENDA PROBLEMA

Bollettino realizzato su scala sinottica-regionale (standard EAWS). La sua valutazione non può escludere in alcun modo la necessità di una seria e capace valutazione locale del pericolo (singolo pendio) che può essere anche sensibilmente diverso. Le previsioni meteorologiche sono relative all'orario UTC (per l'Italia +1 in inverno e +2 in estate).

MINISTERO DELLA DIFESA

meteomont
Servizio Nazionale di previsione neve e valanghe

EAWS EUROPEAN AVALANCHE WARNING SERVICES

CARABINIERI

GRAN SASSO OVEST

PREVISIONE METEO

Quota		03/02/2026 h6:00	03/02/2026 h12:00	03/02/2026 h18:00
1000	Venti	02 Nodi da Ovest	03 Nodi da Sud	03 Nodi da Ovest
	Temperature	+04 °C	+05 °C	+04 °C
	Temp.percepita	4 °C	4 °C	3 °C
2000	Venti	12 Nodi da S-Ovest	08 Nodi da S-Ovest	14 Nodi da S-Ovest
	Temperature	+01 °C	+01 °C	+01 °C
	Temp.percepita	-4 °C	-3 °C	-5 °C
3000	Venti	19 Nodi da S-Ovest	20 Nodi da S-Ovest	22 Nodi da S-Ovest
	Temperature	-04 °C	-03 °C	-04 °C
	Temp.percepita	-12 °C	-11 °C	-13 °C
Zero termico		2100-2300 m.	2200-2400 m.	2100-2300 m.
Fenomeno		—	—	
Stato del cielo				

LEGENDA FENOMENI

— Assenza Fenomeni
Nebbia
Foschia
Pioggia debole
Pioggia moderata
Pioggia forte
Temporali
Nevicata debole
Nevicata moderata
Nevicata forte

STATO DEL CIELO

Sereno
Poco nuvoloso
Nuvoloso
Molto nuvoloso
Coperto

Parametri meteonivometrici registrati presso i campi di rilevamento il 02/02/2026.

Località	Comune	Quota (m.s.l.m.)	Altezza neve (cm)	Neve caduta nelle 24 ore (cm)	Temp. Min (°C)	Temp. Max (°C)	Condizioni del tempo
S. DONATO	Castel del Monte (AQ)	1400	0	0	-5	+8	Assenza di precipitazioni
CAMPO IMPERATORE	L'Aquila (AQ)	2135	96	0	-7	-2	Assenza di precipitazioni
CAMPO PERICOLI *	Pietracamela (TE)	2411	210	0	N.P.	N.P.	Assenza di precipitazioni

(*) Rilievi fuori campo

L'INFORMAZIONE E' PREVENZIONE - LEGGI L'ATTUALE GRADO DI PERICOLO VALANGHE!

IL CAPO DEL CENTRO NAZIONALE METEOMONT
(Ten. Col. RFI Emanuela Gini)
FIRMA AUTOGRAFA OMESSA AI SENSI
DELL'ART.3 DEL D.LGS N.39/1993