MINISTERO DELLA DIFESA

meteomont Servizio Nazionale di previsione neve e valanghe

EAWS EUROPEAN AVALANCHE WARNING SERVICES

CARABINIERI

AERONAUTICA MILITARE SERVIZIO METEOROLOGICO

P.N. ABRUZZO

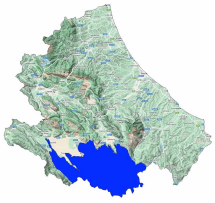

Bollettino Valanghe N. 288/2026 del 01/02/2026 ore 14.00
Validità 48 ore prossima emissione 02/02/2026

A cura del Servizio METEOMONT dell'ARMA dei CARABINIERI
In collaborazione con Servizio Meteorologico dell'Aeronautica militare

SITUAZIONE alle 14:00 del 01/02/2026

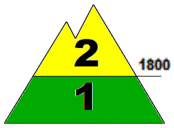

SITUAZIONE TIPO: passaggio da poca a molta neve.



SITUAZIONE TIPO: situazione primaverile.

Quota neve (mslm)	Nord	Sud
	1300 - 1400	1300 - 1400

Altezza Neve (cm)	Neve al suolo	Neve Fresca	Quota (mslm)
	026	001	1520
	006	005	1466

VALANGHE OSSERVATE: -.

PREVISIONI 02/02/2026

GRADO DI PERICOLO: MODERATO 2

SITUAZIONE TIPO: passaggio da poca a molta neve.

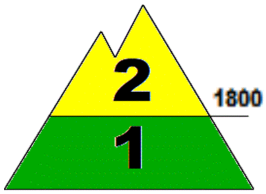

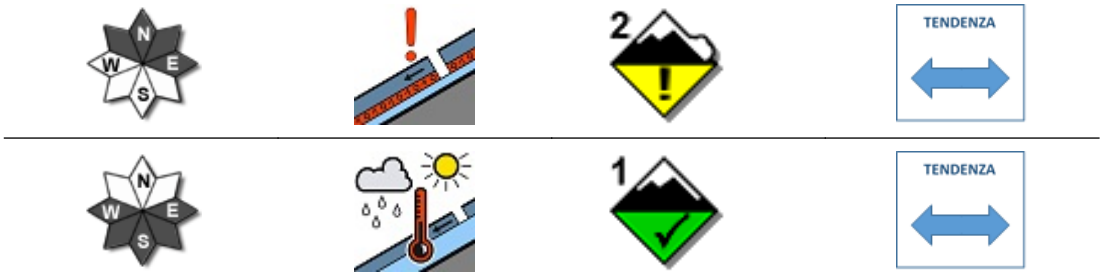

SITUAZIONE TIPO: situazione primaverile.

MANTO NEVOSO: La stabilità del manto nevoso è scarsa su alcuni punti (aree) per versanti in ombra al di sopra di 1800 mslm, possibili valanghe di dimensioni grandi.
La stabilità del manto nevoso è discreta su alcuni punti (aree) per versanti da est a ovest al di sotto di 1800 mslm, possibili valanghe di dimensioni piccole.

AVVERTENZE

Attenzione alla presenza di accumuli eolici di difficile individuazione.

SCALA EUROPEA DEL GRADO DI PERICOLO VALANGHE

5 - MOLTO FORTE | 4 - FORTE | 3 - MARCATO | 2 - MODERATO | 1 - DEBOLE | NO NEVE | NO INFO

LEGENDA PROBLEMA

NEVE FRESCA | LASTRONI DA VENTO | STRATI DEBOLI PERSISTENTI | NEVE BAGNATA | SLITTAMENTO | CORNICI | NESSUN PROBLEMA VALANGHIVO EVIDENTE | NO_INFO

Bollettino realizzato su scala sinottica-regionale (standard EAWS). La sua valutazione non può escludere in alcun modo la necessità di una seria e capace valutazione locale del pericolo (singolo pendio) che può essere anche sensibilmente diverso. Le previsioni meteorologiche sono relative all'orario UTC (per l'Italia +1 in inverno e +2 in estate).

MINISTERO DELLA DIFESA

meteomont
Servizio Nazionale di previsione neve e valanghe

EAWS EUROPEAN AVALANCHE WARNING SERVICES

CARABINIERI

P.N. ABRUZZO

PREVISIONE METEO

Quota		02/02/2026 h6:00	02/02/2026 h12:00	02/02/2026 h18:00
1000	Venti	03 Nodi da Nord	02 Nodi da S-Ovest	01 Nodi da Sud
	Temperature	-01 °C	+00 °C	+00 °C
	Temp.percepita	-3 °C	0 °C	0 °C
2000	Venti	08 nodi da N-Ovest	05 Nodi da Ovest	04 Nodi da Ovest
	Temperature	-03 °C	-02 °C	-01 °C
	Temp.percepita	-8 °C	-5 °C	-4 °C
3000	Venti	10 nodi da N-Ovest	11 Nodi da Ovest	11 Nodi da Ovest
	Temperature	-09 °C	-08 °C	-05 °C
	Temp.percepita	-16 °C	-15 °C	-12 °C
Zero termico		0600-0800 m.	1400-1600 m.	1000-1200 m.
Fenomeno		—	—	—
Stato del cielo				

LEGENDA FENOMENI

— Assenza Fenomeni · Nebbia · Foschia · Pioggia debole · Pioggia moderata · Pioggia forte · Temporali

Nevicata debole · Nevicata moderata · Nevicata forte

STATO DEL CIELO

Sereno · Poco nuvoloso · Nuvoloso · Molto nuvoloso · Coperto

Parametri meteonivometrici registrati presso i campi di rilevamento il 01/02/2026.

Località	Comune	Quota (m.s.l.m.)	Altezza neve (cm)	Neve caduta nelle 24 ore (cm)	Temp. Min (°C)	Temp. Max (°C)	Condizioni del tempo
VALLE GELATA	Pescocostanzo (AQ)	1466	6	5	-1	+7	Nevicata debole continua
COPPO DELL'ORSO	Villetta Barrea (AQ)	1520	26	1	-4	+5	Assenza di precipitazioni
PIANO AREMOGNA	Roccaraso (AQ)	1456	17	6	-5	+5	Nevicata debole intermittente
MIMOLA	Scanno (AQ)	1495	7	2	-2	+10	Nevicata debole continua

(*) Rilievi fuori campo

L'INFORMAZIONE E' PREVENZIONE - LEGGI L'ATTUALE GRADO DI PERICOLO VALANGHE!

IL CAPO DEL CENTRO NAZIONALE METEOMONT
(Ten. Col. RFI Emanuela Gini)
FIRMA AUTOGRAFA OMESSA AI SENSI
DELL'ART.3 DEL D.LGS N.39/1993

Bollettino realizzato su scala sinottica-regionale (standard EAWS). La sua valutazione non può escludere in alcun modo la necessità di una seria e capace valutazione locale del pericolo (singolo pendio) che può essere anche sensibilmente diverso. Le previsioni meteorologiche sono relative all'orario UTC (per l'Italia +1 in inverno e +2 in estate).