MINISTERO DELLA DIFESA

meteomont Servizio Nazionale di previsione neve e valanghe

EAWS EUROPEAN AVALANCHE WARNING SERVICES

CARABINIERI

VELINO - SIRENTE

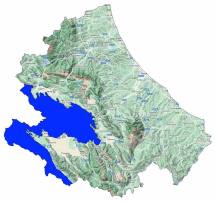

Bollettino Valanghe N. 306/2026 del 02/02/2026 ore 14.00
Validità 48 ore prossima emissione 03/02/2026

A cura del Servizio METEOMONT dell'ARMA dei CARABINIERI
In collaborazione con Servizio Meteorologico dell'Aeronautica militare

SITUAZIONE alle 14:00 del 02/02/2026

SITUAZIONE TIPO: situazione primaverile.

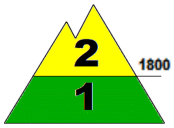



SITUAZIONE TIPO: situazione primaverile.

Quota neve (mslm)	Nord	Sud
	1300 - 1400	1500 - 1800

Altezza Neve (cm)	Neve al suolo	Neve Fresca	Quota (mslm)
	30	000	1729
	021	000	1450

VALANGHE OSSERVATE: Nessuna valanga.

PREVISIONI 03/02/2026

GRADO DI PERICOLO: MODERATO 2

SITUAZIONE TIPO: situazione primaverile.

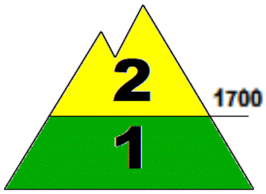



SITUAZIONE TIPO: situazione primaverile.

MANTO NEVOSO: La stabilità del manto nevoso è scarsa su pochi punti (aree) per versanti orientali al di sopra di 1700 mslm, possibili valanghe di dimensioni grandi.
La stabilità del manto nevoso è discreta su pochi punti (aree) per tutte le esposizioni al di sotto di 1700 mslm, possibili valanghe di dimensioni medie.

AVVERTENZE

Attenzione alla presenza di accumuli eolici di difficile individuazione.

SCALA EUROPEA DEL GRADO DI PERICOLO VALANGHE

5 - MOLTO FORTE | 4 - FORTE | 3 - MARCATO | 2 - MODERATO | 1 - DEBOLE | NO NEVE | NO INFO

LEGENDA PROBLEMA

NEVE FRESCA | LASTRONI DA VENTO | STRATI DEBOLI PERSISTENTI | NEVE BAGNATA | SLITTAMENTO | CORNICI | NESSUN PROBLEMA VALANGHIVO EVIDENTE | NO_INFO

Bollettino realizzato su scala sinottica-regionale (standard EAWS). La sua valutazione non può escludere in alcun modo la necessità di una seria e capace valutazione locale del pericolo (singolo pendio) che può essere anche sensibilmente diverso. Le previsioni meteorologiche sono relative all'orario UTC (per l'Italia +1 in inverno e +2 in estate).

MINISTERO DELLA DIFESA

meteomont
Servizio Nazionale di previsione neve e valanghe

EAWS EUROPEAN AVALANCHE WARNING SERVICES

CARABINIERI

VELINO - SIRENTE

PREVISIONE METEO

Quota		03/02/2026 h6:00	03/02/2026 h12:00	03/02/2026 h18:00
1000	Venti	06 Nodi da S-Ovest	08 Nodi da Sud	07 Nodi da Sud
	Temperature	+01 °C	+01 °C	+01 °C
	Temp.percepita	-2 °C	-3 °C	-3 °C
2000	Venti	10 Nodi da S-Ovest	13 Nodi da Sud	11 Nodi da Sud
	Temperature	+01 °C	+01 °C	+01 °C
	Temp.percepita	-4 °C	-4 °C	-4 °C
3000	Venti	19 Nodi da S-Ovest	21 Nodi da S-Ovest	20 Nodi da S-Ovest
	Temperature	-04 °C	-03 °C	-05 °C
	Temp.percepita	-12 °C	-11 °C	-14 °C
Zero termico		2100-2300 m.	2100-2300 m.	2100-2300 m.
Fenomeno			—	
Stato del cielo				

LEGENDA FENOMENI

— Assenza Fenomeni · Nebbia · Foschia · Pioggia debole · Pioggia moderata · Pioggia forte · Temporali

Nevicata debole · Nevicata moderata · Nevicata forte

STATO DEL CIELO

Sereno · Poco nuvoloso · Nuvoloso · Molto nuvoloso · Coperto

Parametri meteonivometrici registrati presso i campi di rilevamento il 02/02/2026.

Località	Comune	Quota (m.s.l.m.)	Altezza neve (cm)	Neve caduta nelle 24 ore (cm)	Temp. Min (°C)	Temp. Max (°C)	Condizioni del tempo
PASSO LE FORCHE	Magliano de' Marsi (AQ)	1276	0	N.P.	-3	+9	Assenza di precipitazioni
SANT'ELIA *	Collelongo (AQ)	1470	17	0	N.P.	N.P.	Assenza di precipitazioni
CAMPO FELICE - BRECCIARA	Rocca di Cambio (AQ)	1729	30	5	-7	0	Assenza di precipitazioni
MARSIA	Tagliacozzo (AQ)	1450	21	0	-8	+9	Assenza di precipitazioni
LA CROCETTA	Lucoli (AQ)	1573	13	0	-12	+7	Assenza di precipitazioni

(*) Rilievi fuori campo

L'INFORMAZIONE E' PREVENZIONE - LEGGI L'ATTUALE GRADO DI PERICOLO VALANGHE!

IL CAPO DEL CENTRO NAZIONALE METEOMONT
(Ten. Col. RFI Emanuela Gini)
FIRMA AUTOGRAFA OMESSA AI SENSI
DELL'ART.3 DEL D.LGS N.39/1993

Bollettino realizzato su scala sinottica-regionale (standard EAWS). La sua valutazione non può escludere in alcun modo la necessità di una seria e capace valutazione locale del pericolo (singolo pendio) che può essere anche sensibilmente diverso. Le previsioni meteorologiche sono relative all'orario UTC (per l'Italia +1 in inverno e +2 in estate).