MINISTERO DELLA DIFESA

meteomont
Servizio Nazionale di previsione neve e valanghe

EAWS EUROPEAN AVALANCHE WARNING SERVICES

CARABINIERI

AERONAUTICA MILITARE SERVIZIO METEOROLOGICO

# MAINARDE-ALTO MOLISE

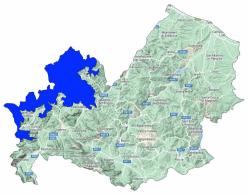

Bollettino Valanghe N. 283/2026 del 02/02/2026 ore 14.00
Validità 48 ore prossima emissione 03/02/2026

**A cura del Servizio METEOMONT dell'ARMA dei CARABINIERI**
**In collaborazione con Servizio Meteorologico dell'Aeronautica militare**

## SITUAZIONE alle 14:00 del 02/02/2026

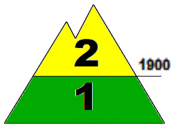


**SITUAZIONE TIPO: passaggio da poca a molta neve.**




**SITUAZIONE TIPO: situazione primaverile.**

| Quota neve (mslm) | Nord | Sud |
|---|---|---|
| | 1300 - 1400 | 1300 - 1500 |

| Altezza Neve (cm) | Neve al suolo | Neve Fresca | Quota (mslm) |
|---|---|---|---|
| | 015 | 000 | 1500 |
| | 000 | 000 | 1220 |

**VALANGHE OSSERVATE: Nessuna valanga.**

## PREVISIONI 03/02/2026

## GRADO DI PERICOLO: MODERATO 2

## SITUAZIONE TIPO: passaggio da poca a molta neve.

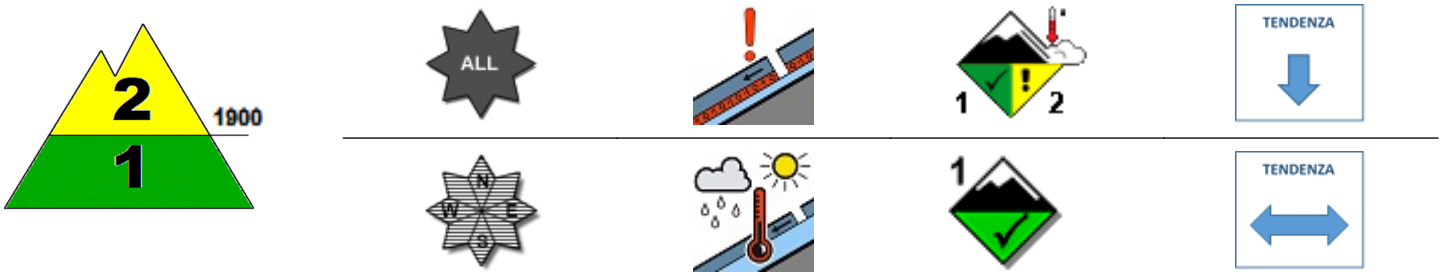


## SITUAZIONE TIPO: situazione primaverile.

**MANTO NEVOSO: La stabilità del manto nevoso è scarsa su pochi punti (aree) per tutte le esposizioni al di sopra di 1900 mslm, possibili valanghe di dimensioni grandi.**
**La stabilità del manto nevoso è discreta su alcuni punti (aree) per isolati pendii al di sotto di 1900 mslm, possibili valanghe di dimensioni piccole.**

## AVVERTENZE

Viste le condizioni del manto nevoso, le attività al di fuori delle piste battute e segnalate richiedono buone capacità di valutazione del pericolo locale.

## SCALA EUROPEA DEL GRADO DI PERICOLO VALANGHE

## LEGENDA PROBLEMA

**Bollettino realizzato su scala sinottica-regionale (standard EAWS). La sua valutazione non può escludere in alcun modo la necessità di una seria e capace valutazione locale del pericolo (singolo pendio) che può essere anche sensibilmente diverso. Le previsioni meteorologiche sono relative all'orario UTC (per l'Italia +1 in inverno e +2 in estate).**

MINISTERO DELLA DIFESA

meteomont
Servizio Nazionale di previsione neve e valanghe

EAWS EUROPEAN AVALANCHE WARNING SERVICES

CARABINIERI

# MAINARDE-ALTO MOLISE

## PREVISIONE METEO

| Quota | | 03/02/2026 h6:00 | 03/02/2026 h12:00 | 03/02/2026 h18:00 |
|---|---|---|---|---|
| 1000 | Venti | 03 Nodi da S-Ovest | 04 Nodi da S-Ovest | 04 Nodi da S-Ovest |
| | Temperature | +03 °C | +04 °C | +06 °C |
| | Temp.percepita | 2 °C | 2 °C | 4 °C |
| 2000 | Venti | 09 Nodi da S-Ovest | 13 Nodi da S-Ovest | 11 Nodi da S-Ovest |
| | Temperature | +00 °C | +01 °C | +02 °C |
| | Temp.percepita | -5 °C | -4 °C | -3 °C |
| 3000 | Venti | 19 Nodi da S-Ovest | 21 Nodi da S-Ovest | 21 Nodi da S-Ovest |
| | Temperature | -03 °C | -01 °C | -03 °C |
| | Temp.percepita | -11 °C | -9 °C | -11 °C |
| Zero termico | | 2000-2200 m. | 2200-2400 m. | 2200-2400 m. |
| Fenomeno | | | — | |
| Stato del cielo | | | | |

## LEGENDA FENOMENI

Assenza Fenomeni — Nebbia — Foschia — Pioggia debole — Pioggia moderata — Pioggia forte — Temporali

Nevicata debole — Nevicata moderata — Nevicata forte

## STATO DEL CIELO

Sereno — Poco nuvoloso — Nuvoloso — Molto nuvoloso — Coperto

## Parametri meteonivometrici registrati presso i campi di rilevamento il 02/02/2026.

| Località | Comune | Quota (m.s.l.m.) | Altezza neve (cm) | Neve caduta nelle 24 ore (cm) | Temp. Min (°C) | Temp. Max (°C) | Condizioni del tempo |
|---|---|---|---|---|---|---|---|
| PRATO GENTILE | Capracotta (IS) | 1490 | 15 | 0 | -3 | 0 | Assenza di precipitazioni |
| PESCOPENNATARO | Pescopennataro (IS) | 1220 | 0 | 0 | -3 | +3 | Assenza di precipitazioni |

(*) Rilievi fuori campo

**L'INFORMAZIONE E' PREVENZIONE - LEGGI L'ATTUALE GRADO DI PERICOLO VALANGHE!**

IL CAPO DEL CENTRO NAZIONALE METEOMONT
(Ten. Col. RFI Emanuela Gini)
FIRMA AUTOGRAFA OMESSA AI SENSI
DELL'ART.3 DEL D.LGS N.39/1993

Bollettino realizzato su scala sinottica-regionale (standard EAWS). La sua valutazione non può escludere in alcun modo la necessità di una seria e capace valutazione locale del pericolo (singolo pendio) che può essere anche sensibilmente diverso. Le previsioni meteorologiche sono relative all'orario UTC (per l'Italia +1 in inverno e +2 in estate).